MINISTERO DELLA DIFESA

meteomont
Servizio Nazionale di previsione neve e valanghe

EAWS EUROPEAN AVALANCHE WARNING SERVICES

CARABINIERI

AERONAUTICA MILITARE SERVIZIO METEOROLOGICO

TERMINILLO MONTI REATINI E LAGA OVEST

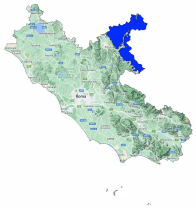

Bollettino Valanghe N. 274/2026 del 01/02/2026 ore 14.00
Validità 48 ore prossima emissione 02/02/2026

A cura del Servizio METEOMONT dell'ARMA dei CARABINIERI
In collaborazione con Servizio Meteorologico dell'Aeronautica militare

SITUAZIONE alle 14:00 del 01/02/2026

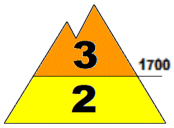

SITUAZIONE TIPO: neve a debole coesione e vento.



SITUAZIONE TIPO: passaggio da poca a molta neve.

Quota neve (mslm)	Nord	Sud
	1100 - 1300	1300 - 1400

Altezza Neve (cm)	Neve al suolo	Neve Fresca	Quota (mslm)
	150	000	1825
	028	000	1350

VALANGHE OSSERVATE: Nessuna valanga.

PREVISIONI 02/02/2026

GRADO DI PERICOLO: MARCATO 3

SITUAZIONE TIPO: neve a debole coesione e vento.

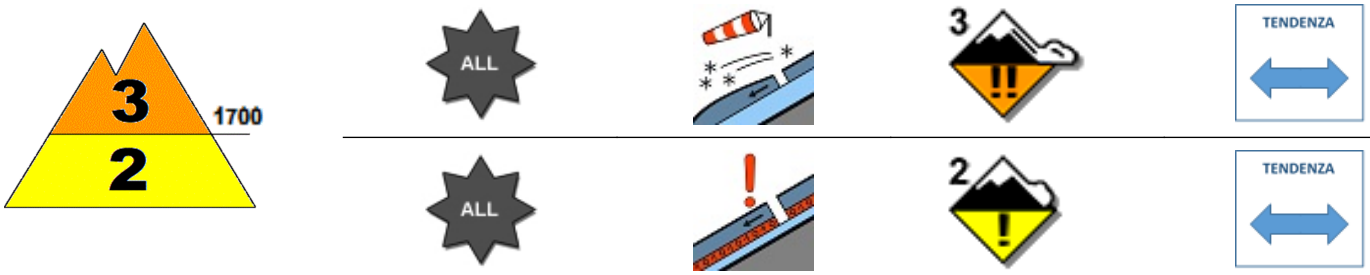

SITUAZIONE TIPO: passaggio da poca a molta neve.

MANTO NEVOSO: La stabilità del manto nevoso è molto scarsa su molti punti (aree) per tutte le esposizioni al di sopra di 1700 mslm, possibili valanghe di dimensioni medie.
La stabilità del manto nevoso è discreta su alcuni punti (aree) per tutte le esposizioni al di sotto di 1700 mslm, possibili valanghe di dimensioni medie.

AVVERTENZE

A seguito dell'attività eolica registrata sono da evitare le zone di accumulo, conche, canaloni, cambi di pendenza e pendii sotto vento in genere.

SCALA EUROPEA DEL GRADO DI PERICOLO VALANGHE

LEGENDA PROBLEMA

Bollettino realizzato su scala sinottica-regionale (standard EAWS). La sua valutazione non può escludere in alcun modo la necessità di una seria e capace valutazione locale del pericolo (singolo pendio) che può essere anche sensibilmente diverso. Le previsioni meteorologiche sono relative all'orario UTC (per l'Italia +1 in inverno e +2 in estate).

MINISTERO DELLA DIFESA

meteomont
Servizio Nazionale di previsione neve e valanghe

EAWS EUROPEAN AVALANCHE WARNING SERVICES

CARABINIERI

TERMINILLO MONTI REATINI E LAGA OVEST

PREVISIONE METEO

Quota		02/02/2026 h6:00	02/02/2026 h12:00	02/02/2026 h18:00
1000	Venti	01 Nodi da Ovest	01 Nodi da Ovest	02 Nodi da S-Ovest
	Temperature	+00 °C	+02 °C	+00 °C
	Temp.percepita	0 °C	2 °C	0 °C
2000	Venti	05 nodi da N-Ovest	04 Nodi da Ovest	03 Nodi da Ovest
	Temperature	-03 °C	-03 °C	-02 °C
	Temp.percepita	-7 °C	-6 °C	-4 °C
3000	Venti	09 nodi da N-Ovest	09 nodi da Ovest	10 nodi da Ovest
	Temperature	-09 °C	-09 °C	-05 °C
	Temp.percepita	-16 °C	-16 °C	-11 °C
Zero termico		1200-1400 m.	1600-1800 m.	1300-1500 m.
Fenomeno		—	—	—
Stato del cielo				

LEGENDA FENOMENI

— Assenza Fenomeni
Nebbia
Foschia
Pioggia debole
Pioggia moderata
Pioggia forte
Temporali
Nevicata debole
Nevicata moderata
Nevicata forte

STATO DEL CIELO

Sereno
Poco nuvoloso
Nuvoloso
Molto nuvoloso
Coperto

Parametri meteonivometrici registrati presso i campi di rilevamento il 01/02/2026.

Località	Comune	Quota (m.s.l.m.)	Altezza neve (cm)	Neve caduta nelle 24 ore (cm)	Temp. Min (°C)	Temp. Max (°C)	Condizioni del tempo
PESCHIERE	Amatrice (RI)	1270	0	0	-1	+11	Assenza di precipitazioni
M. CAIDURO	Cittareale (RI)	1300	13	0	-1	+12	Assenza di precipitazioni
VALLONINA	Leonessa (RI)	1350	28	0	-3	+6	Assenza di precipitazioni
LA MALGA *	Micigliano (RI)	1747	60	0	-4	-3	Assenza di precipitazioni

(*) Rilievi fuori campo

L'INFORMAZIONE E' PREVENZIONE - LEGGI L'ATTUALE GRADO DI PERICOLO VALANGHE!

IL CAPO DEL CENTRO NAZIONALE METEOMONT
(Ten. Col. RFI Emanuela Gini)
FIRMA AUTOGRAFA OMESSA AI SENSI
DELL'ART.3 DEL D.LGS N.39/1993

Bollettino realizzato su scala sinottica-regionale (standard EAWS). La sua valutazione non può escludere in alcun modo la necessità di una seria e capace valutazione locale del pericolo (singolo pendio) che può essere anche sensibilmente diverso. Le previsioni meteorologiche sono relative all'orario UTC (per l'Italia +1 in inverno e +2 in estate).