MINISTERO DELLA DIFESA

meteomont
Servizio Nazionale di previsione neve e valanghe

EAWS EUROPEAN AVALANCHE WARNING SERVICES

CARABINIERI

AERONAUTICA MILITARE SERVIZIO METEOROLOGICO

MONTI SIMBRUINI E META

Bollettino Valanghe N. 268/2026 del 02/02/2026 ore 14.00
Validità 48 ore prossima emissione 03/02/2026

A cura del Servizio METEOMONT dell'ARMA dei CARABINIERI
In collaborazione con Servizio Meteorologico dell'Aeronautica militare

SITUAZIONE alle 14:00 del 02/02/2026

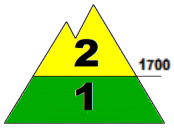

SITUAZIONE TIPO: neve a debole coesione e vento.



SITUAZIONE TIPO: passaggio da poca a molta neve.

Quota neve (mslm)	Nord	Sud
	1300 - 1400	1400 - 1600

Altezza Neve (cm)	Neve al suolo	Neve Fresca	Quota (mslm)
	071	000	1790
	036	000	1550

VALANGHE OSSERVATE: Nessuna valanga.

PREVISIONI 03/02/2026

GRADO DI PERICOLO: MODERATO 2

SITUAZIONE TIPO: neve a debole coesione e vento.

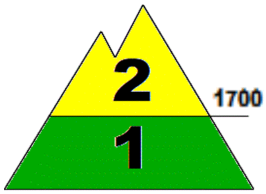

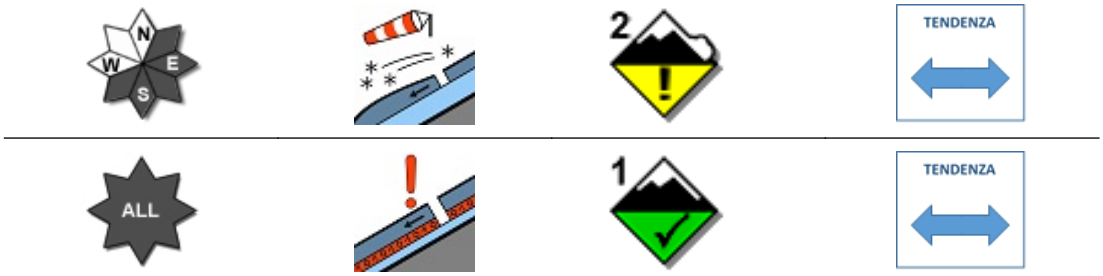

SITUAZIONE TIPO: passaggio da poca a molta neve.

MANTO NEVOSO: La stabilità del manto nevoso è scarsa su alcuni punti (aree) per versanti da nord est a sud ovest al di sopra di 1700 mslm, possibili valanghe di dimensioni medie.
La stabilità del manto nevoso è discreta su alcuni punti (aree) per tutte le esposizioni al di sotto di 1700 mslm, possibili valanghe di dimensioni piccole.

AVVERTENZE

Meteomont ricorda ARTVA, pala e sonda sempre al seguito.

SCALA EUROPEA DEL GRADO DI PERICOLO VALANGHE

5 - MOLTO FORTE | 4 - FORTE | 3 - MARCATO | 2 - MODERATO | 1 - DEBOLE | NO NEVE | NO INFO

LEGENDA PROBLEMA

NEVE FRESCA | LASTRONI DA VENTO | STRATI DEBOLI PERSISTENTI | NEVE BAGNATA | SLITTAMENTO | CORNICI | NESSUN PROBLEMA VALANGHIVO EVIDENTE | NO_INFO

Bollettino realizzato su scala sinottica-regionale (standard EAWS). La sua valutazione non può escludere in alcun modo la necessità di una seria e capace valutazione locale del pericolo (singolo pendio) che può essere anche sensibilmente diverso. Le previsioni meteorologiche sono relative all'orario UTC (per l'Italia +1 in inverno e +2 in estate).

MINISTERO DELLA DIFESA

meteomont
Servizio Nazionale di previsione neve e valanghe

EAWS EUROPEAN AVALANCHE WARNING SERVICES

CARABINIERI

MONTI SIMBRUINI E META

PREVISIONE METEO

Quota		03/02/2026 h6:00	03/02/2026 h12:00	03/02/2026 h18:00
1000	Venti	05 Nodi da Sud	05 Nodi da Sud	05 Nodi da Sud
	Temperature	+04 °C	+04 °C	+05 °C
	Temp.percepita	2 °C	2 °C	3 °C
2000	Venti	14 Nodi da Sud	16 Nodi da Sud	15 Nodi da Sud
	Temperature	+01 °C	+01 °C	+01 °C
	Temp.percepita	-5 °C	-5 °C	-5 °C
3000	Venti	16 Nodi da S-Ovest	20 Nodi da S-Ovest	19 Nodi da S-Ovest
	Temperature	-03 °C	-04 °C	-05 °C
	Temp.percepita	-10 °C	-12 °C	-14 °C
Zero termico		2200-2400 m.	2200-2400 m.	2100-2300 m.
Fenomeno		—		
Stato del cielo				

LEGENDA FENOMENI

— Assenza Fenomeni · Nebbia · Foschia · Pioggia debole · Pioggia moderata · Pioggia forte · Temporali

Nevicata debole · Nevicata moderata · Nevicata forte

STATO DEL CIELO

Sereno · Poco nuvoloso · Nuvoloso · Molto nuvoloso · Coperto

Parametri meteonivometrici registrati presso i campi di rilevamento il 02/02/2026.

Località	Comune	Quota (m.s.l.m.)	Altezza neve (cm)	Neve caduta nelle 24 ore (cm)	Temp. Min (°C)	Temp. Max (°C)	Condizioni del tempo
PRATI DI MEZZO	Picinisco (FR)	1430	16	0	-4	+4	Assenza di precipitazioni
C.STAFFI	Filettino (FR)	1780	68	0	-6	+4	Assenza di precipitazioni
CAMPO CATINO	Guarcino (FR)	1790	71	0	-5	+4	Assenza di precipitazioni

(*) Rilievi fuori campo

L'INFORMAZIONE E' PREVENZIONE - LEGGI L'ATTUALE GRADO DI PERICOLO VALANGHE!

IL CAPO DEL CENTRO NAZIONALE METEOMONT
(Ten. Col. RFI Emanuela Gini)
FIRMA AUTOGRAFA OMESSA AI SENSI
DELL'ART.3 DEL D.LGS N.39/1993