MINISTERO DELLA DIFESA

meteomont Servizio Nazionale di previsione neve e valanghe

EAWS EUROPEAN AVALANCHE WARNING SERVICES

CARABINIERI

APPENNINO CALABRO

Bollettino Valanghe N. 217/2026 del 02/02/2026 ore 14.00
Validità 48 ore prossima emissione 03/02/2026

A cura del Servizio METEOMONT dell'ARMA dei CARABINIERI
In collaborazione con Servizio Meteorologico dell'Aeronautica militare

SITUAZIONE alle 14:00 del 02/02/2026

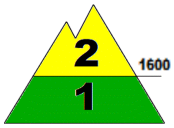

SITUAZIONE TIPO: neve a debole coesione e vento.



SITUAZIONE TIPO: pioggia su neve.

Quota neve (mslm)	Nord	Sud
	1200	1300 - 1600

Altezza Neve (cm)	Neve al suolo	Neve Fresca	Quota (mslm)
	050	025	1530
	005	000	1369

VALANGHE OSSERVATE: Nessuna valanga.

PREVISIONI 03/02/2026

GRADO DI PERICOLO: MODERATO 2

SITUAZIONE TIPO: neve a debole coesione e vento.

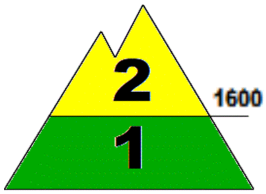



SITUAZIONE TIPO: pioggia su neve.

MANTO NEVOSO: La stabilità del manto nevoso è discreta su alcuni punti (aree) per tutte le esposizioni al di sopra di 1600 mslm, possibili valanghe di dimensioni medie.
La stabilità del manto nevoso è discreta su pochi punti (aree) per tutte le esposizioni al di sotto di 1600 mslm, possibili valanghe di dimensioni piccole.

AVVERTENZE

In considerazione dei recenti apporti di neve fresca, è richiesta una buona valutazione locale della stabilità ed individuazione dell'itinerario.

SCALA EUROPEA DEL GRADO DI PERICOLO VALANGHE

5 - MOLTO FORTE | 4 - FORTE | 3 - MARCATO | 2 - MODERATO | 1 - DEBOLE | NO NEVE | NO INFO

LEGENDA PROBLEMA

NEVE FRESCA | LASTRONI DA VENTO | STRATI DEBOLI PERSISTENTI | NEVE BAGNATA | SLITTAMENTO | CORNICI | NESSUN PROBLEMA VALANGHIVO EVIDENTE | NO_INFO

Bollettino realizzato su scala sinottica-regionale (standard EAWS). La sua valutazione non può escludere in alcun modo la necessità di una seria e capace valutazione locale del pericolo (singolo pendio) che può essere anche sensibilmente diverso. Le previsioni meteorologiche sono relative all'orario UTC (per l'Italia +1 in inverno e +2 in estate).

MINISTERO DELLA DIFESA

meteomont
Servizio Nazionale di previsione neve e valanghe

EAWS EUROPEAN AVALANCHE WARNING SERVICES

CARABINIERI

APPENNINO CALABRO

PREVISIONE METEO

Quota		03/02/2026 h6:00	03/02/2026 h12:00	03/02/2026 h18:00
1000	Venti	03 Nodi da Sud	05 Nodi da Sud	03 Nodi da Sud
	Temperature	+04 °C	+05 °C	+05 °C
	Temp.percepita	3 °C	3 °C	4 °C
2000	Venti	09 Nodi da S-Ovest	13 Nodi da S-Ovest	11 Nodi da S-Ovest
	Temperature	+04 °C	+05 °C	+05 °C
	Temp.percepita	0 °C	1 °C	1 °C
3000	Venti	12 Nodi da Ovest	17 Nodi da S-Ovest	14 Nodi da S-Ovest
	Temperature	+00 °C	+01 °C	-01 °C
	Temp.percepita	-6 °C	-5 °C	-7 °C
Zero termico		2900-3100 m.	3000-3200 m.	2800-3000 m.
Fenomeno		—	—	—
Stato del cielo				

LEGENDA FENOMENI

— Assenza Fenomeni · Nebbia · Foschia · Pioggia debole · Pioggia moderata · Pioggia forte · Temporali

Nevicata debole · Nevicata moderata · Nevicata forte

STATO DEL CIELO

Sereno · Poco nuvoloso · Nuvoloso · Molto nuvoloso · Coperto

Parametri meteonivometrici registrati presso i campi di rilevamento il 02/02/2026.

Località	Comune	Quota (m.s.l.m.)	Altezza neve (cm)	Neve caduta nelle 24 ore (cm)	Temp. Min (°C)	Temp. Max (°C)	Condizioni del tempo
BIVIO NARDODIPACE	Mongiana (VV)	1339	0	0	+1	+5	Pioggia moderata
GAMBARIE	Santo Stefano in Aspromonte (RC)	1367	5	N.P.	-2	+2	Pioggia mista a neve
VALICO DI MONTE SCURO	Celico (CS)	1600	48	10	-1	+9	Nebbia con cielo visibile
BUTURO	Albi (CZ)	1530	50	25	-3	+3	Nevicata debole intermittente

(*) Rilievi fuori campo

L'INFORMAZIONE E' PREVENZIONE - LEGGI L'ATTUALE GRADO DI PERICOLO VALANGHE!

IL CAPO DEL CENTRO NAZIONALE METEOMONT
(Ten. Col. RFI Emanuela Gini)
FIRMA AUTOGRAFA OMESSA AI SENSI
DELL'ART.3 DEL D.LGS N.39/1993

Bollettino realizzato su scala sinottica-regionale (standard EAWS). La sua valutazione non può escludere in alcun modo la necessità di una seria e capace valutazione locale del pericolo (singolo pendio) che può essere anche sensibilmente diverso. Le previsioni meteorologiche sono relative all'orario UTC (per l'Italia +1 in inverno e +2 in estate).