Bulletin d'estimation du risque d'avalanche

(valable en dehors des pistes balisées et ouvertes)

MASSIF : Aspe Ossau

Rédigé le lundi 2 février 2026 à 16h

Estimation des risques pour le : MARDI 03 FÉVRIER

NEIGE VENTÉE EN ALTITUDE, HUMIDIFICATION PLUS BAS.

3

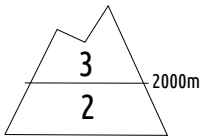

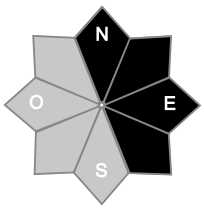

Plaques en altitude.

Au-dessus de 2000m indice de risque marqué, plus bas indice limité.

Départs spontanés : Départs ponctuels en neige ventée et humide, avalanches de fond possibles.

Déclenchements provoqués : Plaques en altitude.

Indices de risque : 5 très fort - 4 fort - 3 marqué - 2 limité - 1 faible -- En noir : les pentes les plus dangereuses

Stabilité du manteau neigeux

Situation avalancheuse typique : neige ventée neige humide

Déclenchements provoqués :
Au-dessus de 2000m, dans les pentes raides des versants allant du Nord au Sud-Est, des plaques à vent peu épaisses se forment ce mardi, se superposant sur d'autres plaques à vent plus épaisses provenant des chutes de neige de la veille. Elles restent facilement déclenchables par un simple skieur et leur rupture peut engendrer une cassure linéaire moyenne (taille 2), voire grande (taille 3) notamment en secteur frontalier où les accumulations de neige restent les plus importantes. Il n'est pas exclu de trouver des plaques à vent dans un large secteur Ouest, leur déclenchement engendrant des avalanches moyennes (taille 2).
Sous 2000m, quelques plaques à vent peu épaisses se forment ce mardi, s'ajoutant à celles de lundi plus épaisses, leur rupture engendrant des avalanches petites à moyennes (taille 1 à 2), plus rarement des grandes (taille 3) sur les pentes raides des versants allant du Nord vers le Sud-Est et notamment en secteur frontalier (accumulations plus importantes).

Départs spontanés :
Au-dessus de 2000m, des départs ponctuels de plaques décrites ci-dessus restent possibles, par surcharge par le vent, engendrant ainsi des avalanches généralement moyennes (taille 2), voire des grandes (taille 3) notamment en secteur frontalier.
Sous 2000m, avec l'humidification de la veille, des départs ponctuels sont attendus en journée, de taille petite à moyenne (taille 1 à 2), plus rarement de grande taille (taille 3) dans les versants Nord à Sud-Est et notamment en secteur frontalier. Des avalanches de fond restent aussi possibles lorsque l'humidification atteint le sol, engendrant ainsi des avalanches moyennes (taille 2), à parfois grandes (taille 3) dans les zones d'accumulation les plus importantes.

Qualité de la neige

Enneigement : L'enneigement est assez correct pour la saison, mais les crêtes, cols et sommets sont souvent pelés par le vent dans les expositions ouest. Le manteau neigeux s'est bien humidifié lundi sous 1800m, se réduisant progressivement. Nouvelles chutes de neige mardi, surtout en secteur frontalier dès 1200m, venant s'ajouter à celles de lundi après-midi.
Limites skiables : Manteau neigeux skiable à partir de 1400/1500m ce mardi, bien humidifié en-dessous.
État de la neige : Neige croûtée sous 1500/1600m ce mardi matin, plus souvent travaillée par le vent de Sud à Sud-Ouest au-dessus. Accumulations de neige ventée plus importantes en secteur frontalier.

Aperçu météo pour le mardi 03 février

nuit	matin	après-midi	soir

Sommets frontaliers accrochés dès la matinée, ciel voilé ailleurs. Quelques averses de neige en journée. Vent de Sud à Sud-Ouest modéré à assez fort.

	nuit	matin	après-midi	soir
Pluie-Neige	1 000 m	1 100 m	1 100 m	1 100 m
Iso 0 °C	1 400 m	1 500 m	1 500 m	1 500 m
Vent 1500 m	30 km/h	25 km/h	35 km/h	55 km/h
Vent 3000 m	40 km/h	45 km/h	50 km/h	70 km/h

Épaisseur de neige hors-piste

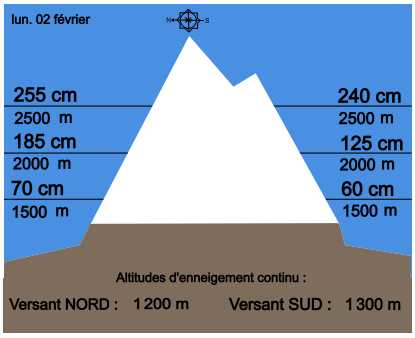

Précipitations à 1800 m

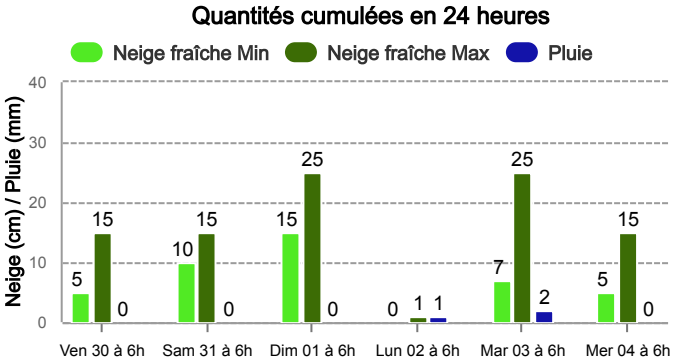

Tendance du mercredi 04 février

3 **Indice de risque marqué**

Maintien du risque marqué. Quelques averses de neige à venir avec du vent assez fort de Sud-Ouest le matin, basculant Ouest/Nord-Ouest ensuite.

Pour consulter la vigilance en cours, veuillez vous rendre sur le site https://vigilance.meteofrance.fr/fr

Météo-France - 73 avenue de Paris, 94165 Saint-Mandé cedex - Contact : contact@meteo.fr

Rédigé par Météo-France avec la contribution des observateurs du réseau nivo-météorologiques. Partenariat : ANMSM (Maires de Stations de Montagne), DSF (Domaines Skiables de France), ADSP (Directeurs de Pistes et de la Sécurité des Stations de Sports d'Hiver) et autres acteurs de la montagne.

Bulletin neige & avalanches par téléphone au
0 892 68 10 20 Service 0,35 € / min + prix appel

RÉPUBLIQUE FRANÇAISE
Liberté Égalité Fraternité

METEO FRANCE
À VOS CÔTÉS, DANS UN CLIMAT QUI CHANGE

Bulletin d'estimation du risque d'avalanche

(valable en dehors des pistes balisées et ouvertes)

MASSIF : Aspe Ossau

Rédigé le lundi 2 février 2026 à 16h

Conditions nivo-météo des 7 derniers jours

	mar. 27/01				mer. 28/01				jeu. 29/01				ven. 30/01				sam. 31/01				dim. 01/02				lun. 02/02			
	03h	09h	15h	21h	03h	09h	15h	21h	03h	09h	15h	21h	03h	09h	15h	21h	03h	09h	15h	21h	03h	09h	15h	21h	03h	09h	15h	21h
Météo																												
Vent (km/h)	110	110	65	70	60	55	55	80	70	100	70	90	100	90	60	90	100	100	100	70	40	40	45	50	70	115	110	80
à 3000m																												
Vent (km/h)	70	60	25	20	15	15	10	25	20	40	30	50	65	50	30	45	60	70	70	35	25	20	20	35	50	80	80	45
à 1500m																												

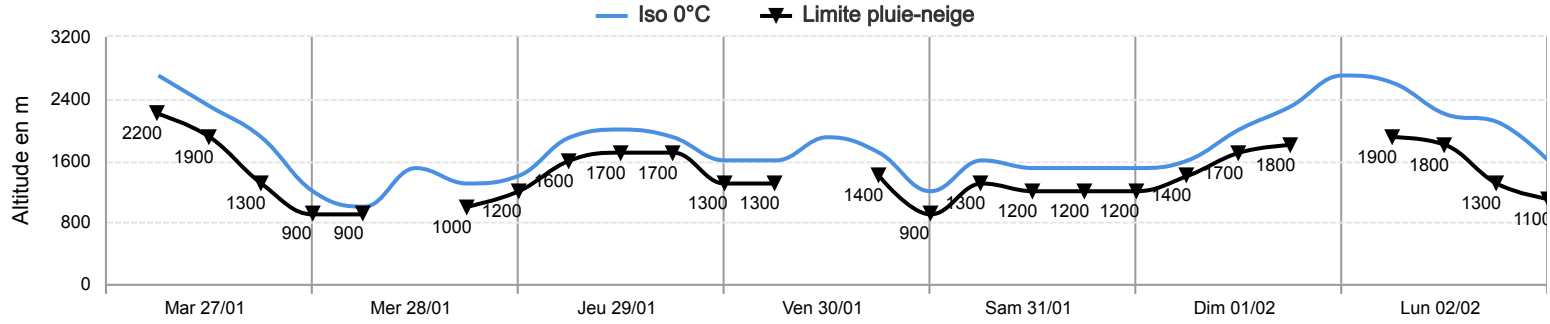

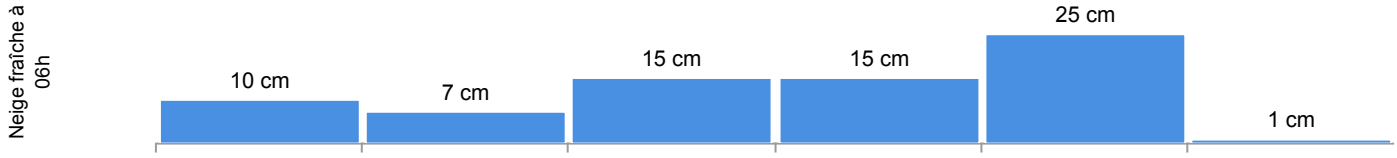

Risque d'avalanche	mar. 27/01	mer. 28/01	jeu. 29/01	ven. 30/01	sam. 31/01	dim. 01/02	lun. 02/02
	4	3	3	3	4	4	3

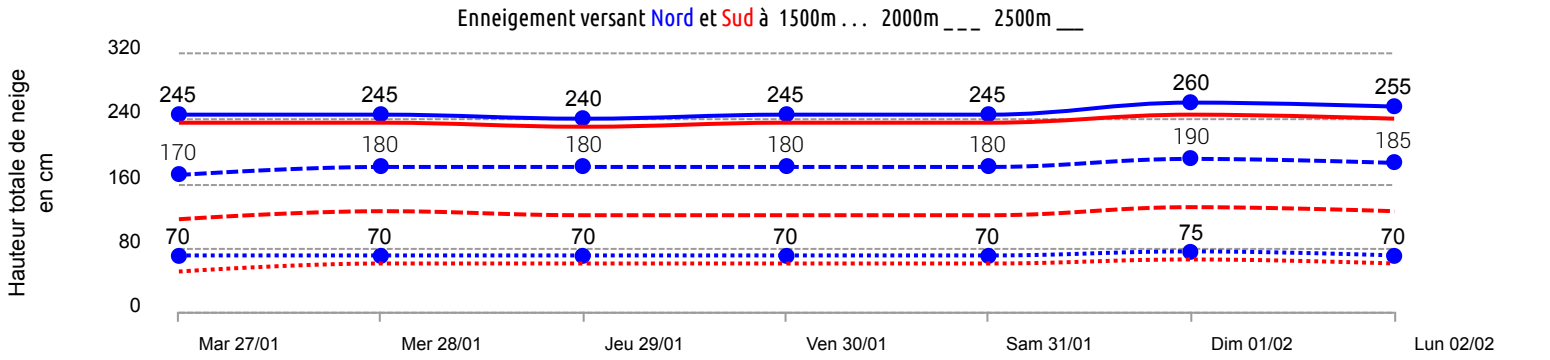

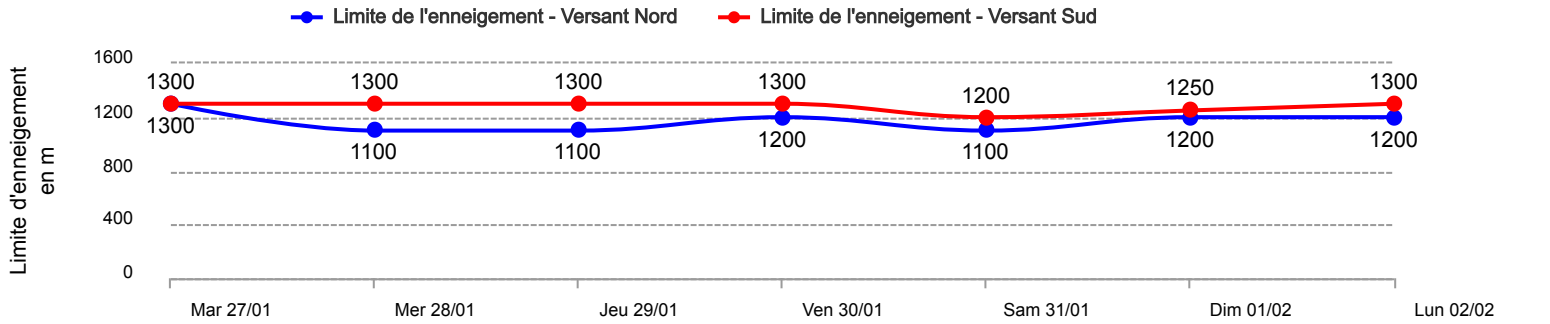

Pour consulter la vigilance en cours, veuillez vous rendre sur le site https://vigilance.meteofrance.fr/fr

Météo-France - 73 avenue de Paris, 94165 Saint-Mandé cedex - Contact : contact@meteo.fr

Rédigé par Météo-France avec la contribution des observateurs du réseau nivo-météorologiques. Partenariat : ANMSM (Maires de Stations de Montagne), DSF (Domaines Skiables de France), ADSP (Directeurs de Pistes et de la Sécurité des Stations de Sports d'Hiver) et autres acteurs de la montagne.

Bulletin neige & avalanches par téléphone au
0 892 68 10 20 Service 0,35 € / min + prix appel