Bulletin d'estimation du risque d'avalanche

(valable en dehors des pistes balisées et ouvertes)

MASSIF : Belledonne

Rédigé le lundi 2 février 2026 à 16h

Estimation des risques pour le : MARDI 03 FÉVRIER

NOUVELLES INSTABILITÉS EN FORMATION, AVEC LOCALEMENT DES COUCHES FRAGILES ENFOUIES DANS LES VERSANTS FROIDS.

3

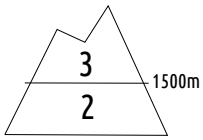

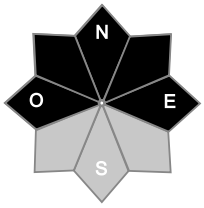

Au-dessus de 1500m indice de risque marqué, plus bas indice limité.

Départs spontanés : quelques ruptures de plaques sous le vent. Mardi en journée rares départs humide dans les pentes raides au soleil.

Déclenchements provoqués : nouvelles instabilités sous le vent de sud. Très localement, possibilité de grande avalanche avec déclenchement en cascade.

Indices de risque : 5 très fort - 4 fort - 3 marqué - 2 limité - 1 faible -- En noir : les pentes les plus dangereuses

Stabilité du manteau neigeux

Situation avalancheuse typique : neige ventée couche fragile persistante

Déclenchements provoqués : le vent de sud à sud-ouest qui souffle depuis ce lundi et qui se renforce dans la nuit (100 km/h et plus), favorise et va favoriser la formation de nombreuses plaques, y compris loin des crêtes. Ruptures faciles au passage d'un skieur sur de nombreuses pentes, surtout en plaques dures, avec des épaisseurs de cassures importantes. De plus, un peu de neige est annoncée (très ventée) d'ici mardi matin, 5 cm voire 10 cm localement plus haut que 2000 m, suffisant pour amplifier le phénomène. Très ponctuellement au-dessus de 1800/2000 m environ, le départ d'une avalanche de surface pourrait également déclencher en cascade une avalanche de plus grande ampleur, en venant solliciter des couches fragiles persistantes enfouies dans le manteau. Ces couches fragiles pourraient être davantage présentes sur l'Est du massif, côté Maurienne, mais très localement on a pu également en observer plus à l'Ouest...Sous 1400/1600 m environ, le risque devrait rester plus limité, la neige récente s'étant davantage alourdie/humidifiée.

Départs spontanés : des ruptures naturelles de plaques peuvent se produire sous l'action du vent et des chutes de neige, pouvant atteindre la taille 2, voire 3 dans de rares cas. Mardi au fil de la journée, rares avalanches de neige humide de taille 1 à 2 (petites à moyennes) non exclues dans les pentes raides exposées au soleil et près des rochers.

Qualité de la neige

Qualification de l'enneigement : l'enneigement s'est bien amélioré depuis la semaine dernière et est désormais typique d'une fin janvier sur le massif (quoi que légèrement déficitaire à basse altitude). Les crêtes sont toutefois assez peu enneigées ainsi que les pentes plein Sud, les chemins sous les sapins... Le vent de sud en cours va créer de nombreuses disparités...

Limites skiables : à partir de 1000/1300 m.

Qualité de la neige mardi : neige récente en cours de tassement à l'abri du vent. Vers les crêtes, neige récente qui devient franchement plus dense, travaillée voire arrachée par le fort vent, parfois loin des crêtes. Sous 1400/1600 m et dans les versants ensoleillés, la neige s'est davantage alourdie, voire jusque 1800/2000 m avec la petite pluie de la nuit. Les quelques cm de neige prévus d'ici mardi matin sont souvent non visibles à cause du vent...

Aperçu météo pour le mardi 03 février

	nuit	matin	après-midi	soir

Tempête de sud et neige jusque mardi matin, puis le soleil revient peu à peu. Encore un peu de vent de sud mardi en journée.

Pluie-Neige	1 600 m	1 300 m		
Iso 0 °C	2 200 m	1 700 m	1 800 m	1 800 m
Vent 2000 m	↖ 85 km/h	↗ 50 km/h	↗ 40 km/h	↖ 35 km/h
Vent 3000 m	↑ 100 km/h	↗ 60 km/h	↗ 50 km/h	↗ 45 km/h

Épaisseur de neige hors-piste

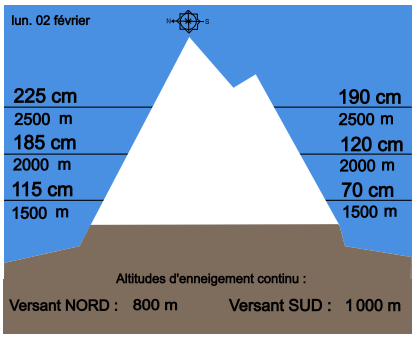

Précipitations à 1800 m

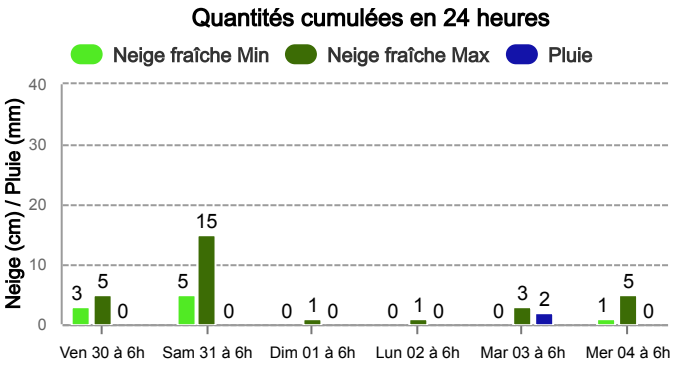

Tendance du mercredi 04 février

3 **Indice de risque marqué**

Le manteau neigeux reste globalement instable ce mercredi. Vent du sud soufflant à 50-60 km/h sur les crêtes.

Pour consulter la vigilance en cours, veuillez vous rendre sur le site https://vigilance.meteofrance.fr/fr

Météo-France - 73 avenue de Paris, 94165 Saint-Mandé cedex - Contact : contact@meteo.fr

Rédigé par Météo-France avec la contribution des observateurs du réseau nivo-météorologiques. Partenariat : ANMSM (Maires de Stations de Montagne), DSF (Domaines Skiables de France), ADSP (Directeurs de Pistes et de la Sécurité des Stations de Sports d'Hiver) et autres acteurs de la montagne.

Bulletin neige & avalanches par téléphone au 0 892 68 10 20 Service 0,35 € / min + prix appel

RÉPUBLIQUE FRANÇAISE
Liberté Égalité Fraternité

METEO FRANCE
À VOS CÔTÉS, DANS UN CLIMAT QUI CHANGE

Bulletin d'estimation du risque d'avalanche

(valable en dehors des pistes balisées et ouvertes)

MASSIF : Belledonne

Rédigé le lundi 2 février 2026 à 16h

Conditions nivo-météo des 7 derniers jours

	mar. 27/01				mer. 28/01				jeu. 29/01				ven. 30/01				sam. 31/01				dim. 01/02				lun. 02/02			
	03h	09h	15h	21h	03h	09h	15h	21h	03h	09h	15h	21h	03h	09h	15h	21h	03h	09h	15h	21h	03h	09h	15h	21h	03h	09h	15h	21h
Météo																												
Vent (km/h)	60	85	100	95	15	15	35	45	35	25	25	30	40	35	25	20	25	15	15	20	20	20	30	25	30	40	70	110
à 3000m																												
Vent (km/h)	45	80	90	90	5	5	10	15	10	5	5	5	15	20	15	15	15	10	10	10	10	10	15	15	15	20	60	100
à 2000m																												

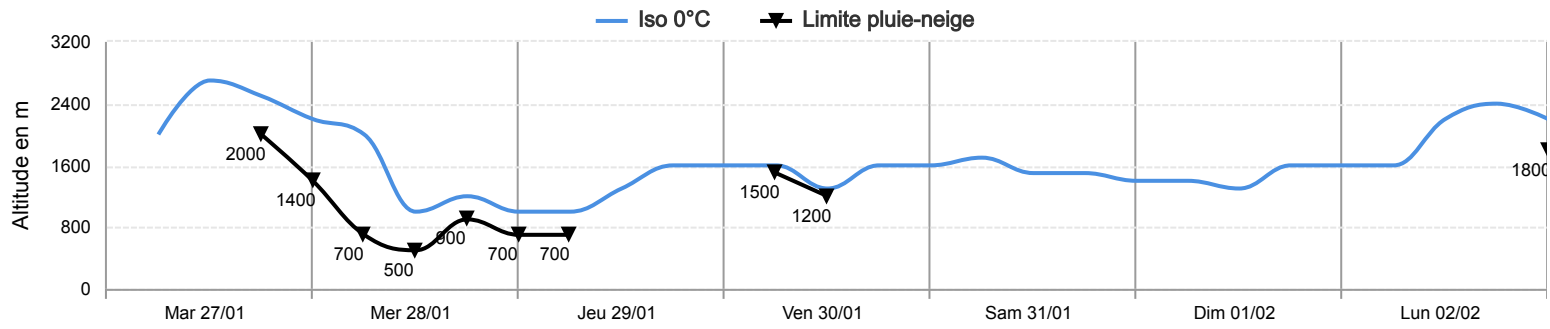

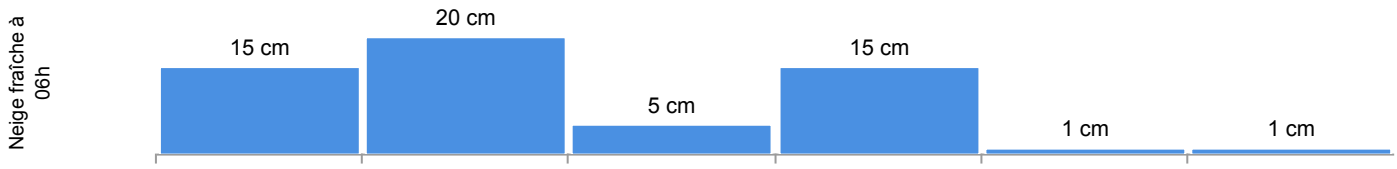

Risque d'avalanche	mar. 27/01	mer. 28/01	jeu. 29/01	ven. 30/01	sam. 31/01	dim. 01/02	lun. 02/02
	3	3	3	3	3	3	3

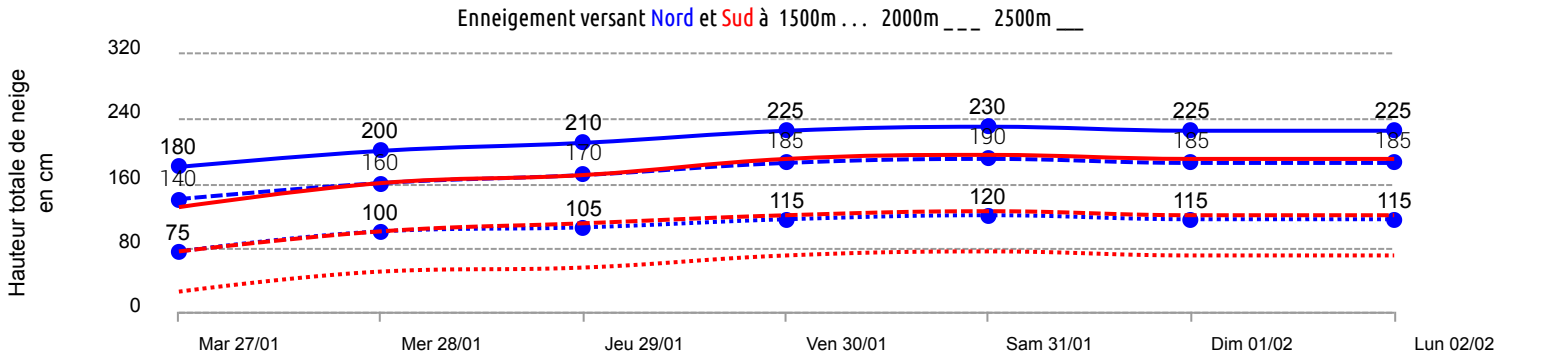

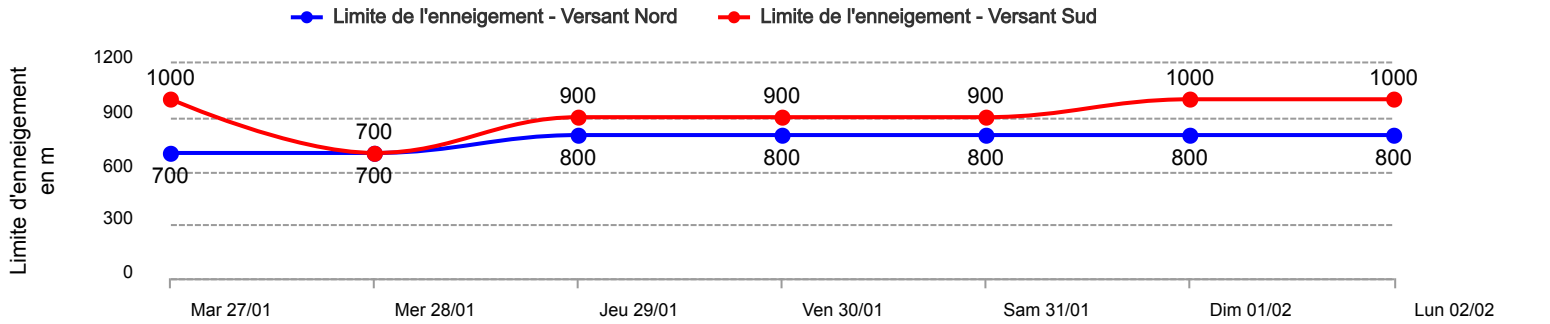

Pour consulter la vigilance en cours, veuillez vous rendre sur le site https://vigilance.meteofrance.fr/fr

Météo-France - 73 avenue de Paris, 94165 Saint-Mandé cedex - Contact : contact@meteo.fr

Bulletin neige & avalanches par téléphone au

0 892 68 10 20 Service 0,35 € / min + prix appel

Rédigé par Météo-France avec la contribution des observateurs du réseau nivo-météorologiques. Partenariat : ANMSM (Maires de Stations de Montagne), DSF (Domaines Skiables de France), ADSP (Directeurs de Pistes et de la Sécurité des Stations de Sports d'Hiver) et autres acteurs de la montagne.