Bulletin d'estimation du risque d'avalanche

(valable en dehors des pistes balisées et ouvertes)

MASSIF : Champsaur

Rédigé le lundi 2 février 2026 à 16h

Estimation des risques pour le : MARDI 03 FÉVRIER

FORTE INSTABILITÉ DU MANTEAU NEIGEUX - IMPORTANTS VOLUMES DE NEIGE MOBILISABLES

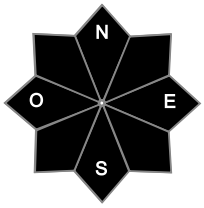

Indice de risque fort.

Départs spontanés : dans la neige fraîche, sous forme de départs en poires ou de plaques parfois volumineuses.

Déclenchements provoqués : nombreuses plaques faciles à déclencher. Cassures pouvant être larges et épaisses.

Indices de risque : 5 très fort - 4 fort - 3 marqué - 2 limité - 1 faible -- En noir : les pentes les plus dangereuses

Stabilité du manteau neigeux

Situation avalancheuse typique : neige fraîche couche fragile persistante

Déclenchements provoqués : l'instabilité du manteau neigeux est à nouveau particulièrement importante ce mardi. Nombreuses plaques faciles à déclencher dans la neige fraîche, parfois à distance, et même en secteur forestier. Ces instabilités sont difficiles à détecter dans les pentes où le vent n'a pas soufflé très fort. Le passage d'un seul skieur suffit pour déclencher ces plaques et engendrer des avalanches moyennes à grandes (taille 2 à 3), avec parfois de larges cassures. Une très grande avalanche (taille 4) possible en cas de rupture sur une couche fragile persistante très enfouie, dans un secteur à la topographie favorable (large cirque par exemple). Le déclenchement d'une première plaque de surface peut favoriser le départ d'une de ces avalanches très volumineuses.

Départs spontanés : - fréquentes avalanches de plaques avec la surcharge de la neige fraîche et du transport par le vent (taille 2 à 3, voire ponctuellement 4).
- Départs en poire dans les pentes/couloirs raides chargés par le vent de sud, ou avec les éclaircies l'après-midi. Avalanches taille 2, voire 3 si la topographie est favorable. Certaines de ces avalanches peuvent aussi déclencher des plaques en contrebas.
- Quelques talus bien chargés peuvent se délester ponctuellement sur les portions de routes habituellement exposées.

Qualité de la neige

L'enneigement est un peu excédentaire pour un début février, notamment en vallées. Données observées : 44 cm au hameau des Portes dans le Valgaudemar à 1270 m, 87 cm à la Nivôse d'Orcières à 2280 m, et 125 cm au-dessus de Prapic à 2480 m.

Limite d'enneigement skiable : dès les fonds de vallées, mais avec une sous-couche un peu limite en adrets sous 1600 m.

État de la neige de surface : mardi matin, neige fraîche en quantité, plus humide sous 1800/2000 m, souvent travaillée par le vent de sud à sud-est en altitude. Elle se dépose sur un manteau neigeux encore meuble dans les versants ombragés, plus dense ou légèrement croûté dans les pentes sud.

Aperçu météo pour le mardi 03 février

	nuit	matin	après-midi	soir

Fortes chutes de neige dans la nuit et tout début de matinée (30/40 cm), plus faibles en journée de mardi (10/15 cm supplémentaires). Vent de sud passagèrement tempétueux, faiblissant dans la journée.

Pluie-Neige	1 500 m	1 000 m	1 200 m	
Iso 0 °C	2 000 m	1 500 m	1 600 m	1 600 m
Vent 2000 m	↖ 50 km/h	↑ 35 km/h	↑ 20 km/h	↖ 15 km/h
Vent 3000 m	↑ 100 km/h	↑ 70 km/h	↗ 40 km/h	↖ 20 km/h

Épaisseur de neige hors-piste

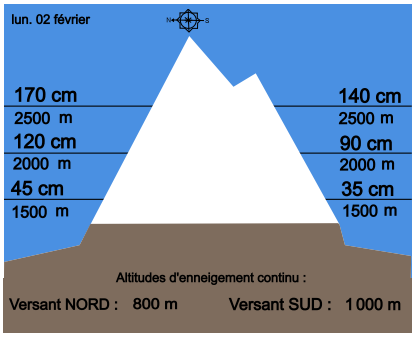

Précipitations à 1800 m

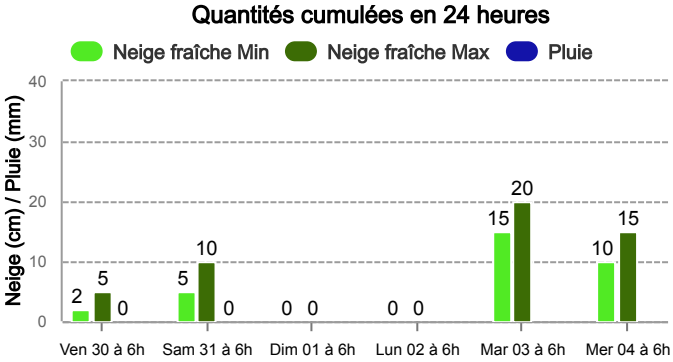

Tendance du mercredi 04 février

Indice de risque fort

La stabilisation du manteau neigeux est lente, le risque de déclenchement de plaque reste probablement fort.

Pour consulter la vigilance en cours, veuillez vous rendre sur le site https://vigilance.meteofrance.fr/fr

Météo-France - 73 avenue de Paris, 94165 Saint-Mandé cedex - Contact : contact@meteo.fr

Rédigé par Météo-France avec la contribution des observateurs du réseau nivo-météorologiques. Partenariat : ANMSM (Maires de Stations de Montagne), DSF (Domaines Skiables de France), ADSP (Directeurs de Pistes et de la Sécurité des Stations de Sports d'Hiver) et autres acteurs de la montagne.

Bulletin neige & avalanches par téléphone au 0 892 68 10 20 Service 0,35 € / min + prix appel

RÉPUBLIQUE FRANÇAISE
Liberté Égalité Fraternité

METEO FRANCE
À VOS CÔTÉS, DANS UN CLIMAT QUI CHANGE

Bulletin d'estimation du risque d'avalanche

(valable en dehors des pistes balisées et ouvertes)

MASSIF : Champsaur

Rédigé le lundi 2 février 2026 à 16h

Conditions nivo-météo des 7 derniers jours

	mar. 27/01				mer. 28/01				jeu. 29/01				ven. 30/01				sam. 31/01				dim. 01/02				lun. 02/02			
	03h	09h	15h	21h	03h	09h	15h	21h	03h	09h	15h	21h	03h	09h	15h	21h	03h	09h	15h	21h	03h	09h	15h	21h	03h	09h	15h	21h
Météo																												
Vent (km/h)	20	45	60	70	60	50	35	50	40	30	20	15	20	30	40	25	20	20	10	10	10	10	25	45	35	25	50	80
à 3000m																												
Vent (km/h)	15	30	50	50	45	35	35	40	30	20	15	10	10	20	25	15	10	10	10	10	10	10	15	20	20	10	20	35
à 2000m																												

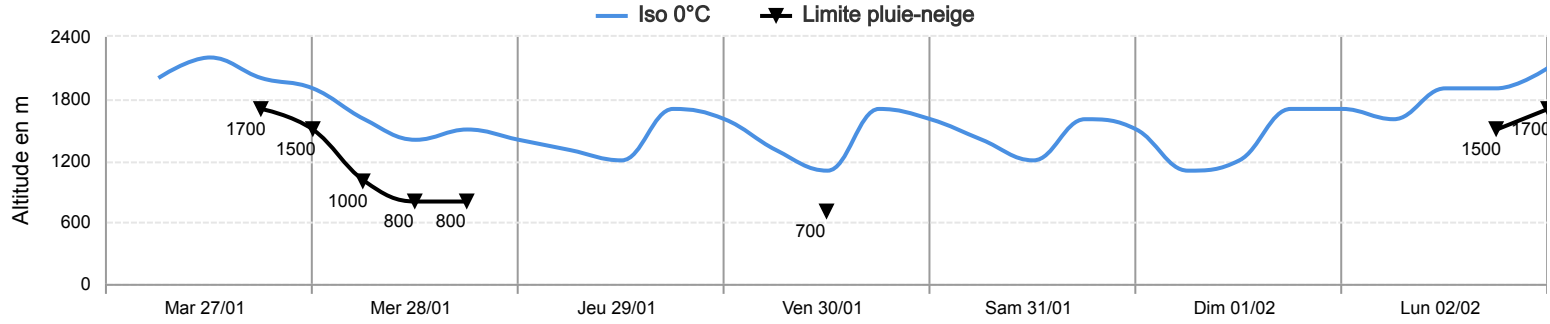

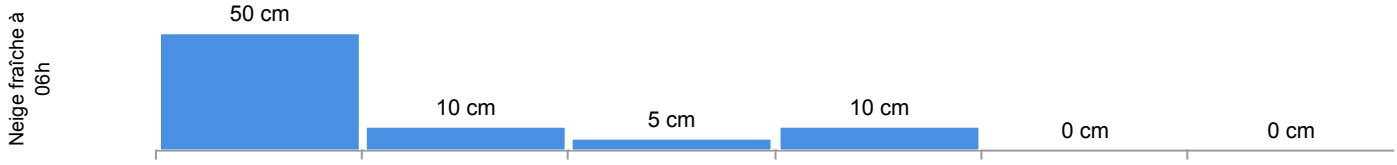

Risque d'avalanche	mar. 27/01	mer. 28/01	jeu. 29/01	ven. 30/01	sam. 31/01	dim. 01/02	lun. 02/02
	4	4	4	4	3	3	3

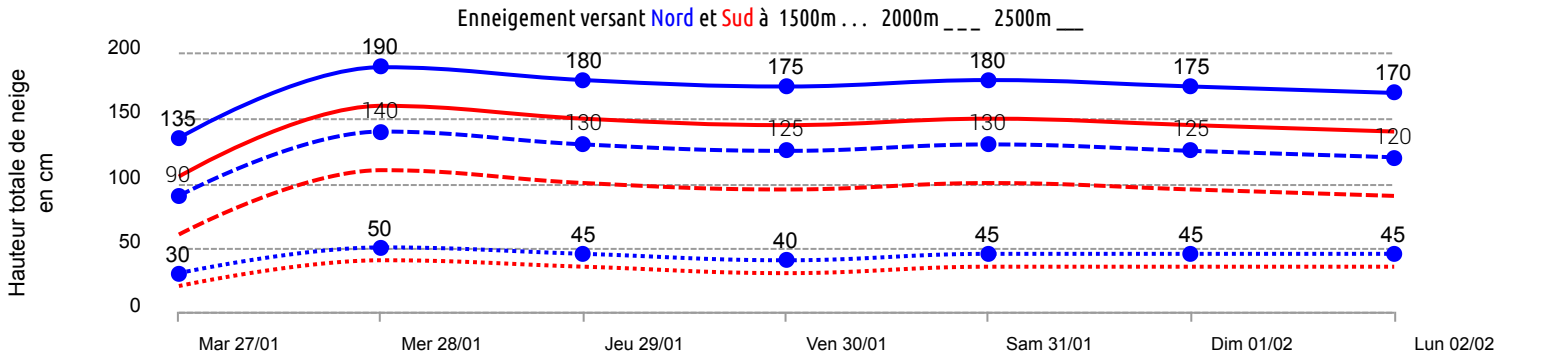

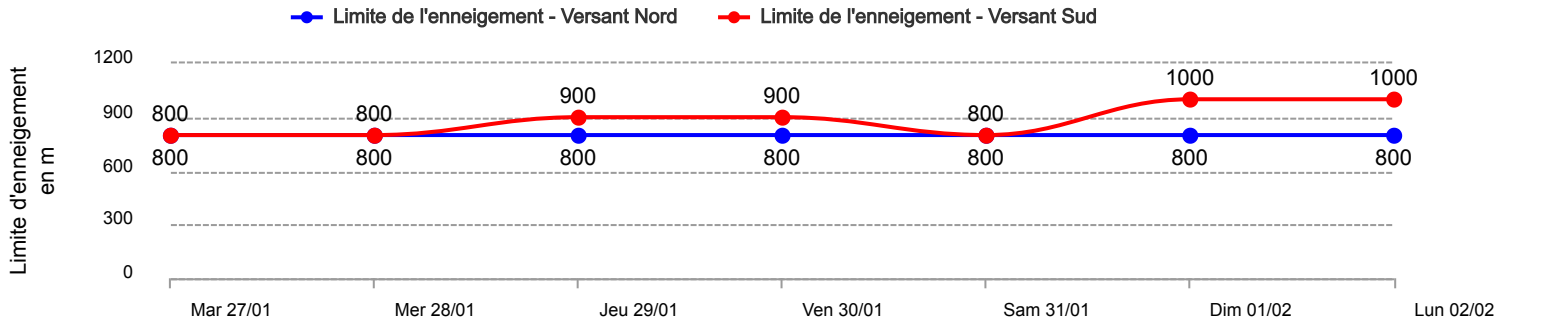

Pour consulter la vigilance en cours, veuillez vous rendre sur le site https://vigilance.meteofrance.fr/fr

Météo-France - 73 avenue de Paris, 94165 Saint-Mandé cedex - Contact : contact@meteo.fr

Rédigé par Météo-France avec la contribution des observateurs du réseau nivo-météorologiques. Partenariat : ANMSM (Maires de Stations de Montagne), DSF (Domaines Skiables de France), ADSP (Directeurs de Pistes et de la Sécurité des Stations de Sports d'Hiver) et autres acteurs de la montagne.

Bulletin neige & avalanches par téléphone au
0 892 68 10 20 Service 0,35 € / min + prix appel