Bulletin d'estimation du risque d'avalanche

(valable en dehors des pistes balisées et ouvertes)

MASSIF : Devoluy

Rédigé le lundi 2 février 2026 à 16h

Estimation des risques pour le : MARDI 03 FÉVRIER

MANTEAU NEIGEUX INSTABLE, EN PARTICULIER DANS LA NEIGE FRAICHE EN ALTITUDE

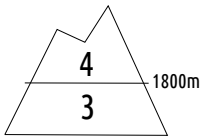

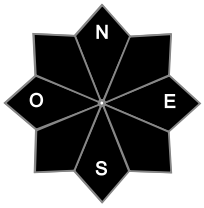

Au-dessus de 1800m indice de risque fort, plus bas indice marqué.

Départs spontanés : plaques ou départs en poire dans la neige fraîche au-dessus de 1800/2000 m - en neige humide sous 1800 m.

Déclenchements provoqués : nombreuses plaques en altitude, faciles à déclencher.

Indices de risque : 5 très fort - 4 fort - 3 marqué - 2 limité - 1 faible -- En noir : les pentes les plus dangereuses

Stabilité du manteau neigeux

Situation avalancheuse typique : neige fraîche couche fragile persistante

Déclenchements provoqués : l'instabilité du manteau neigeux est forte ce mardi. Au-dessus de 1800/2000 m environ, nombreuses plaques faciles à déclencher dans la neige fraîche fortement ventée. Le passage d'un seul skieur suffit pour déclencher ces plaques et engendrer des avalanches moyennes à grandes (taille 2 à 3), avec parfois de larges cassures. Le déclenchement d'une première plaque de surface peut favoriser ponctuellement le départ d'une avalanche plus volumineuse.
Sous 1800 m, risque nettement plus faible suite à la remontée temporaire de la limite pluie-neige qui humidifie le manteau neigeux.

Départs spontanés : - avalanches de plaques avec la surcharge de la neige fraîche et du transport par le vent en altitude (taille 2, voire 3).
- Départs en poire dans les pentes/couloirs raides d'altitude chargés par le vent de sud, ou avec les éclaircies l'après-midi. Avalanches taille 2, voire 3 si la topographie est favorable. Certaines de ces avalanches peuvent aussi déclencher des plaques en contrebas.
- Sous 1800 m environ, quelques avalanches de neige humide ou coulées de talus, avec la pluie qui humidifie la neige de surface encore froide, notamment dans les ubacs.

Qualité de la neige

L'enneigement est plutôt excédentaire pour un début février en vallées, proche des normales au-dessus de 2000 m.

Limite d'enneigement skiable : vers 1000/1200 m en ubacs. Sous-couche un peu limite en adrets sous 1400/1500 m.

État de la neige de surface : mardi matin, neige fraîche en quantité, plus humide sous 1800/2000 m, et souvent travaillée par le vent de sud à sud-est en altitude. Elle se dépose sur un manteau neigeux encore meuble dans les versants ombragés, plus dense ou légèrement croûté dans les pentes sud.

Aperçu météo pour le mardi 03 février

	nuit	matin	après-midi	soir

Fortes chutes de neige en altitude dans la nuit et tout début de matinée (30 cm vers 2200 m), plus faibles en journée de mardi (5/10 cm supplémentaires). Vent de sud tempétueux, faiblissant dans la journée.

Pluie-Neige	1 500 m	1 100 m	1 200 m	
Iso 0 °C	2 000 m	1 500 m	1 600 m	1 700 m
Vent 2000 m	↖ 70 km/h	↑ 45 km/h	↑ 35 km/h	↑ 35 km/h
Vent 3000 m	↑ 120 km/h	↗ 60 km/h	↗ 40 km/h	↑ 35 km/h

Épaisseur de neige hors-piste

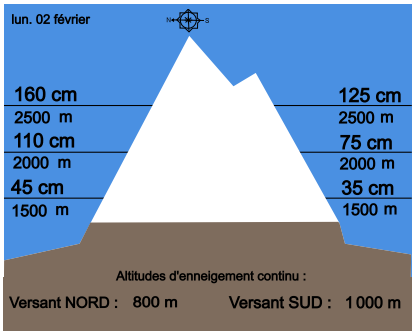

Précipitations à 1800 m

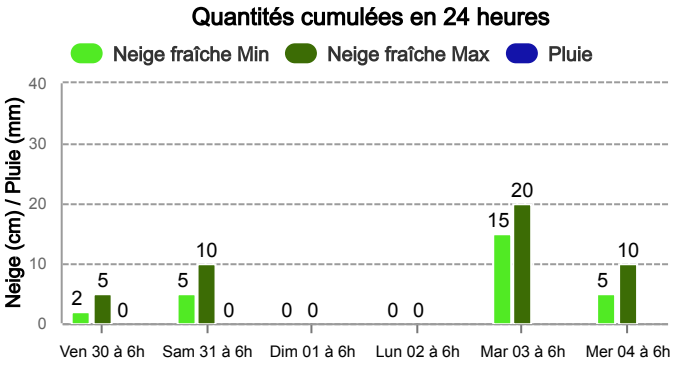

Tendance du mercredi 04 février

Indice de risque marqué

Le manteau neigeux reste instable, avec des plaques récentes faciles à déclencher au-dessus de 1800/2000 m.

Pour consulter la vigilance en cours, veuillez vous rendre sur le site https://vigilance.meteofrance.fr/fr

Météo-France - 73 avenue de Paris, 94165 Saint-Mandé cedex - Contact : contact@meteo.fr

Rédigé par Météo-France avec la contribution des observateurs du réseau nivo-météorologiques. Partenariat : ANMSM (Maires de Stations de Montagne), DSF (Domaines Skiables de France), ADSP (Directeurs de Pistes et de la Sécurité des Stations de Sports d'Hiver) et autres acteurs de la montagne.

Bulletin neige & avalanches par téléphone au
0 892 68 10 20 Service 0,35 € / min + prix appel

RÉPUBLIQUE FRANÇAISE
Liberté Égalité Fraternité

METEO FRANCE
À VOS CÔTÉS, DANS UN CLIMAT QUI CHANGE

Bulletin d'estimation du risque d'avalanche

(valable en dehors des pistes balisées et ouvertes)

MASSIF : Devoluy

Rédigé le lundi 2 février 2026 à 16h

Conditions nivo-météo des 7 derniers jours

	mar. 27/01				mer. 28/01				jeu. 29/01				ven. 30/01				sam. 31/01				dim. 01/02				lun. 02/02			
	03h	09h	15h	21h	03h	09h	15h	21h	03h	09h	15h	21h	03h	09h	15h	21h	03h	09h	15h	21h	03h	09h	15h	21h	03h	09h	15h	21h
Météo																												
Vent (km/h)	20	50	70	70	60	40	35	50	50	35	30	30	35	40	40	25	25	5	5	10	20	20	40	30	35	50	70	100
à 3000m																												
Vent (km/h)	10	45	65	55	40	30	25	50	50	30	20	15	15	30	25	15	15	15	15	10	20	20	15	10	10	25	45	80
à 2000m																												

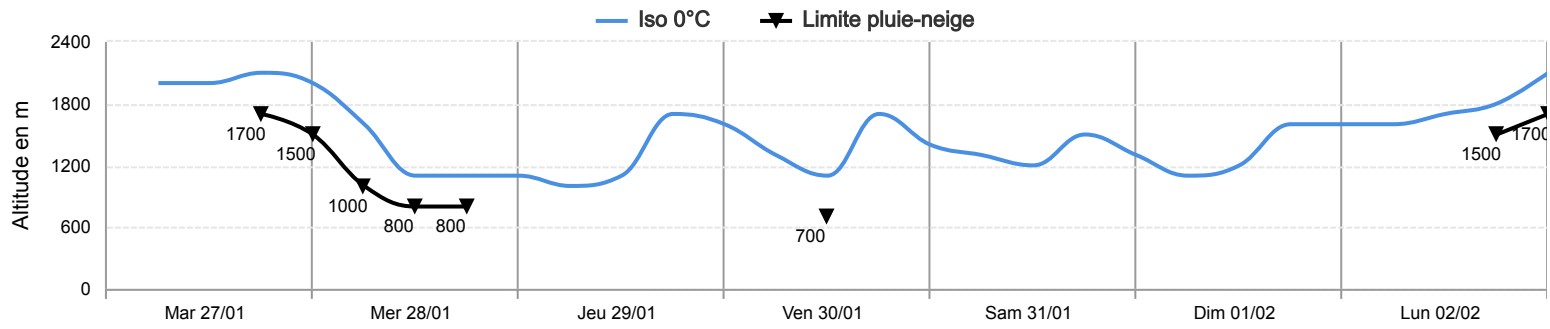

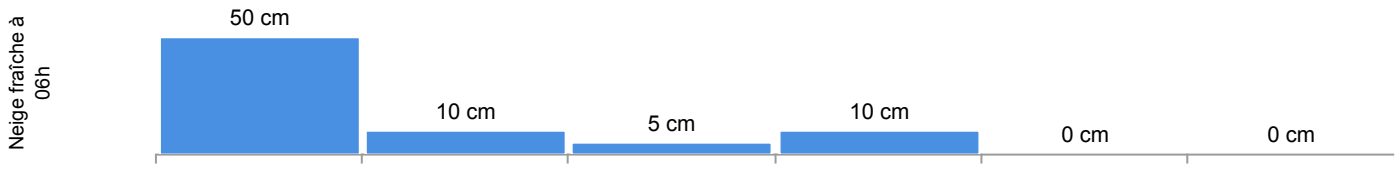

Risque d'avalanche	mar. 27/01	mer. 28/01	jeu. 29/01	ven. 30/01	sam. 31/01	dim. 01/02	lun. 02/02
	4	4	4	4	3	3	3

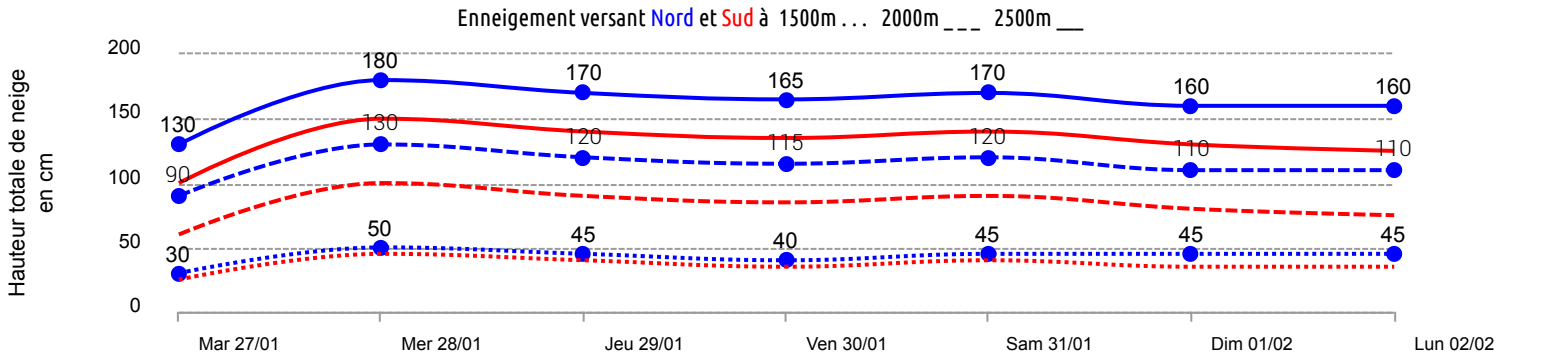

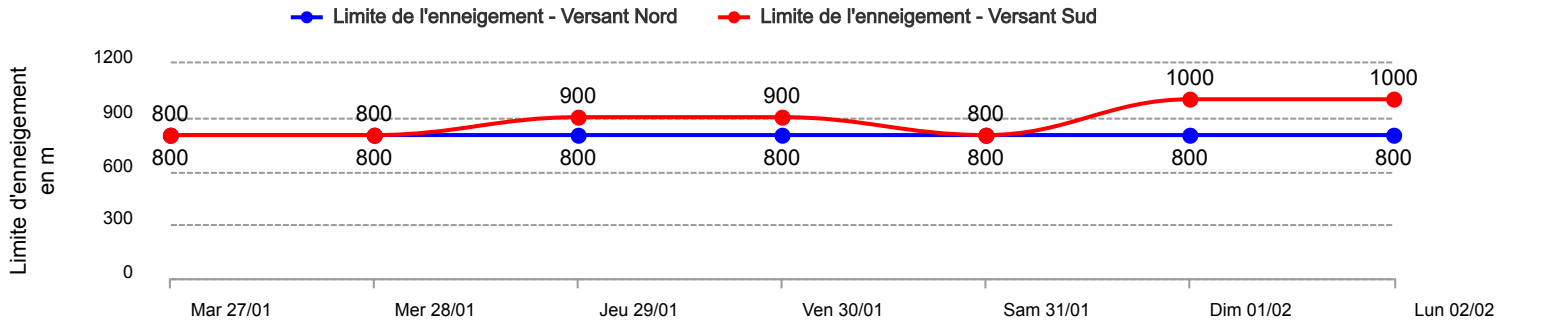

Pour consulter la vigilance en cours, veuillez vous rendre sur le site https://vigilance.meteofrance.fr/fr

Météo-France - 73 avenue de Paris, 94165 Saint-Mandé cedex - Contact : contact@meteo.fr

Bulletin neige & avalanches par téléphone au

0 892 68 10 20 Service 0,35 € / min + prix appel

Rédigé par Météo-France avec la contribution des observateurs du réseau nivo-météorologiques. Partenariat : ANMSM (Maires de Stations de Montagne), DSF (Domaines Skiables de France), ADSP (Directeurs de Pistes et de la Sécurité des Stations de Sports d'Hiver) et autres acteurs de la montagne.