Bulletin d'estimation du risque d'avalanche

(valable en dehors des pistes balisées et ouvertes)

MASSIF : Embrunais Parpaillon

Rédigé le lundi 2 février 2026 à 16h

Estimation des risques pour le : MARDI 03 FÉVRIER

MANTEAU NEIGEUX PARTICULIÈREMENT INSTABLE

4

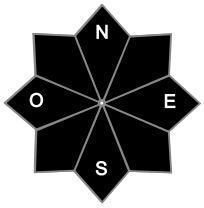

Indice de risque fort.

Départs spontanés : en plaques ou en poire dans la neige fraîche, avec le transport par le vent ou au retour des éclaircies.

Déclenchements provoqués : nombreuses plaques très faciles à déclencher. Cassures pouvant être larges et épaisses.

Indices de risque : 5 très fort - 4 fort - 3 marqué - 2 limité - 1 faible -- En noir : les pentes les plus dangereuses

Stabilité du manteau neigeux

Situation avalancheuse typique : neige fraîche couche fragile persistante

Déclenchements provoqués : forte instabilité du manteau neigeux dans de nombreuses pentes, sous forme de plaques très faciles à déclencher dans la neige fraîche, parfois à distance, et même en zone de forêt. Elles sont difficiles à identifier là où le vent n'a pas soufflé trop fort. Le passage d'un seul skieur engendre fréquemment des avalanches de taille moyenne à grande (taille 2 à 3). Cassures parfois larges, emportant toute la couche de neige récente, voire la quasi-totalité du manteau neigeux en place. La rupture d'une première plaque de surface facilite le déclenchement de ces avalanches plus volumineuses.
Ces nouvelles chutes de neige se déposent sur un manteau très peu consolidé et constitué de plusieurs couches fragiles très réactives, situées soit à l'interface avec la chute de neige précédente, soit enfouie plus en profondeur.

Départs spontanés : - fréquentes avalanches de plaques avec la surcharge de la neige fraîche et du transport par le vent (taille 2 à 3), principalement jusqu'à mardi matin.
- Quelques départs en poire dans les pentes/couloirs raides chargés par le vent de sud, ou avec les éclaircies l'après-midi. Avalanches petites à moyennes (taille 1 à 2). Certaines de ces avalanches en poire peuvent aussi déclencher des plaques en contrebas.

Qualité de la neige

L'enneigement est proche des normales pour un début février.
Données observées : 70 cm à la Nivôse du Parpaillon à 2550 m.

Limite d'enneigement skiable : dès 1200/1300 m en ubacs, plutôt 1700/1800 m en adrets avec peu de sous-couche jusqu'à haute altitude.

État de la neige de surface : mardi matin, neige fraîche en surface du manteau neigeux, souvent travaillée par le vent de sud à sud-est. Elle se dépose sur un manteau neigeux encore meuble et peu consolidé dans les versants ombragés, plus dense ou légèrement croûté dans les pentes sud.

Aperçu météo pour le mardi 03 février

	nuit	matin	après-midi	soir

Chutes de neige passagèrement soutenues dans la nuit de lundi à mardi (vers 2000 m, 15 à 25 cm), plus faibles en journée de mardi (2 à 5 cm). Vent de sud à sud-est fort en altitude, faiblissant progressivement en cours de journée.

Pluie-Neige	1 500 m	1 100 m	1 200 m	
Iso 0 °C	1 900 m	1 500 m	1 600 m	1 600 m
Vent 2000 m	↑ 40 km/h	↑ 30 km/h	↑ 20 km/h	↖ 15 km/h
Vent 3000 m	↑ 80 km/h	↗ 60 km/h	↗ 40 km/h	↗ 30 km/h

Épaisseur de neige hors-piste

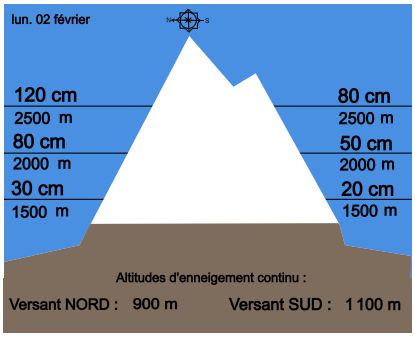

Précipitations à 1800 m

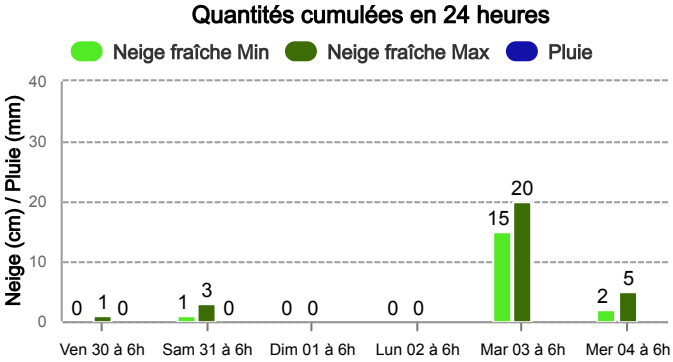

Tendance du mercredi 04 février

4 **Indice de risque fort**

La stabilisation du manteau neigeux est très lente, le risque de déclenchement de plaque reste fort.

Pour consulter la vigilance en cours, veuillez vous rendre sur le site https://vigilance.meteofrance.fr/fr

Météo-France - 73 avenue de Paris, 94165 Saint-Mandé cedex - Contact : contact@meteo.fr

Rédigé par Météo-France avec la contribution des observateurs du réseau nivo-météorologiques. Partenariat : ANMSM (Maires de Stations de Montagne), DSF (Domaines Skiables de France), ADSP (Directeurs de Pistes et de la Sécurité des Stations de Sports d'Hiver) et autres acteurs de la montagne.

Bulletin neige & avalanches par téléphone au 0 892 68 10 20 Service 0,35 € / min + prix appel

RÉPUBLIQUE FRANÇAISE
Liberté Égalité Fraternité

METEO FRANCE
À VOS CÔTÉS, DANS UN CLIMAT QUI CHANGE

Bulletin d'estimation du risque d'avalanche

(valable en dehors des pistes balisées et ouvertes)

MASSIF : Embrunais Parpaillon

Rédigé le lundi 2 février 2026 à 16h

Conditions nivo-météo des 7 derniers jours

	mar. 27/01				mer. 28/01				jeu. 29/01				ven. 30/01				sam. 31/01				dim. 01/02				lun. 02/02			
	03h	09h	15h	21h	03h	09h	15h	21h	03h	09h	15h	21h	03h	09h	15h	21h	03h	09h	15h	21h	03h	09h	15h	21h	03h	09h	15h	21h
Météo																												
Vent (km/h)	20	40	55	60	60	50	30	40	40	30	25	30	35	35	40	30	25	20	10	15	15	15	25	35	30	30	45	80
à 3000m																												
Vent (km/h)	5	25	45	50	40	25	15	25	25	15	15	20	20	25	30	20	15	15	10	10	10	10	10	10	10	10	15	40
à 2000m																												

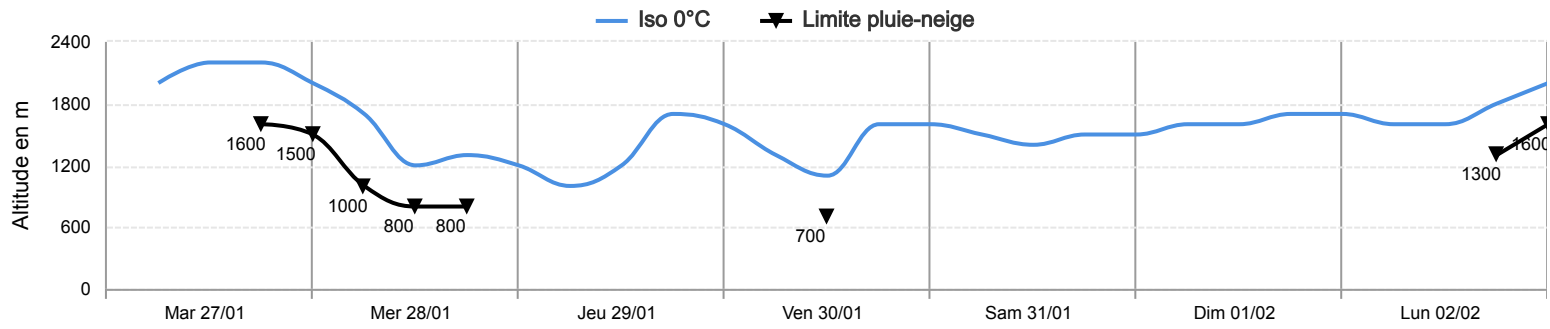

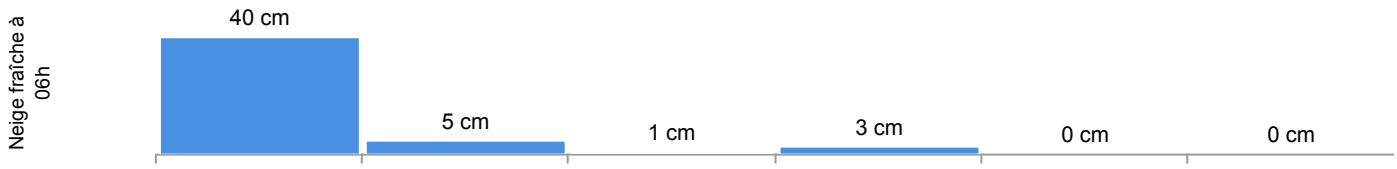

Risque d'avalanche	mar. 27/01	mer. 28/01	jeu. 29/01	ven. 30/01	sam. 31/01	dim. 01/02	lun. 02/02
	4	4	4	4	3	3	3

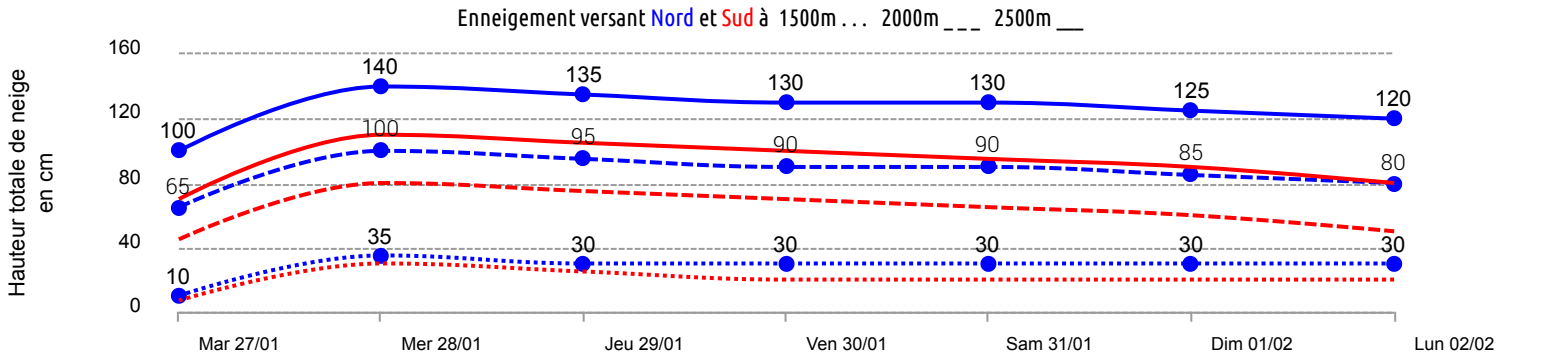

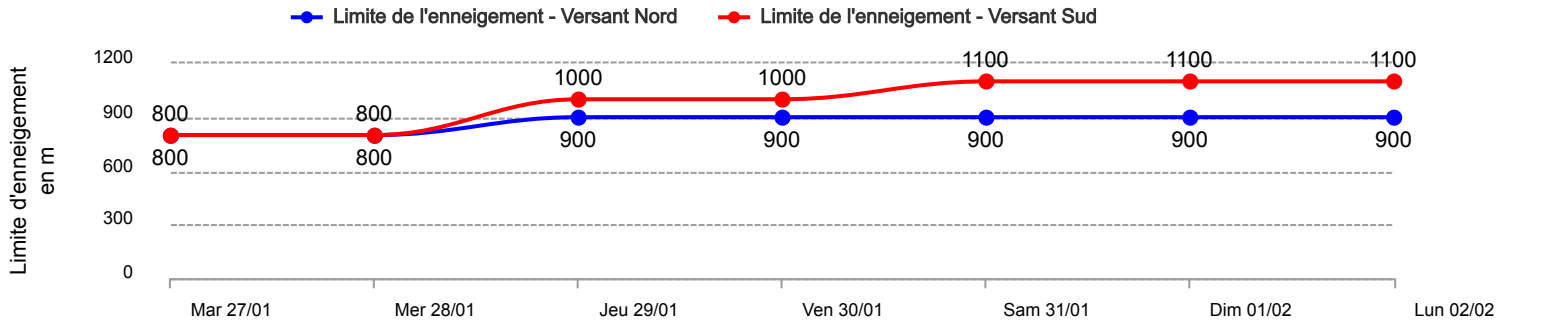

Pour consulter la vigilance en cours, veuillez vous rendre sur le site https://vigilance.meteofrance.fr/fr

Météo-France - 73 avenue de Paris, 94165 Saint-Mandé cedex - Contact : contact@meteo.fr

Rédigé par Météo-France avec la contribution des observateurs du réseau nivo-météorologiques. Partenariat : ANMSM (Maires de Stations de Montagne), DSF (Domaines Skiables de France), ADSP (Directeurs de Pistes et de la Sécurité des Stations de Sports d'Hiver) et autres acteurs de la montagne.

Bulletin neige & avalanches par téléphone au
0 892 68 10 20 Service 0,35 € / min + prix appel