Bulletin d'estimation du risque d'avalanche

(valable en dehors des pistes balisées et ouvertes)

MASSIF : Grandes-Rousses

Rédigé le lundi 2 février 2026 à 16h

Estimation des risques pour le : MARDI 03 FÉVRIER

NOUVELLES INSTABILITÉS EN FORMATION, REPOSANT PARFOIS SUR DES COUCHES FRAGILES PERSISTANTES DANS LES VERSANTS FROIDS.

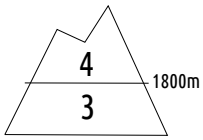

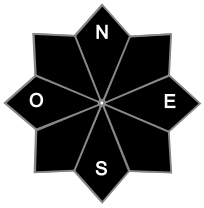

Au-dessus de 1800m indice de risque fort, plus bas indice marqué.

Départs spontanés : quelques ruptures de plaques sous le vent. Mardi en journée rares départs humide dans les pentes raides au soleil.

Déclenchements provoqués : nouvelles et nombreuses instabilités sous le vent de Sud, faciles à déclencher par un skieur. Possibilité de grandes avalanches avec déclenchements en cascade.

Indices de risque : 5 très fort - 4 fort - 3 marqué - 2 limité - 1 faible -- En noir : les pentes les plus dangereuses

Stabilité du manteau neigeux

Situation avalancheuse typique : neige ventée couche fragile persistante

Déclenchements provoqués : le vent de sud à sud-ouest qui souffle depuis ce lundi et qui se renforce dans la nuit (100 km/h et plus), favorise et va favoriser la formation de nombreuses plaques, y compris loin des crêtes. Ruptures faciles au passage d'un skieur sur de nombreuses pentes, surtout en plaques dures, avec des épaisseurs de cassures importantes. La neige annoncée (très ventée) d'ici mardi matin, environ 15-20 cm vers les Emparis plus haut que 2000 m, 5-10 cm vers Huez, va amplifier le phénomène. De plus, ces nouvelles structures instables reposent elles mêmes par endroits sur des sous couches fragiles persistantes, bien enfouies dans le manteau, surtout dans les secteurs Maurienne, Galibier ou Emparis. Certes enfouies, ça n'empêche pas à un skieur de les solliciter à distance depuis un secteur moins enneigé/pelé (typiquement sur un bord de couloir), ou /et indirectement via un déclenchement en cascade depuis une plaque dure récente. S'attendre à une grande et épaisse plaque si déclenchement de ce type. Sous 1800/2000 m environ, le risque est marqué (3/5) avec des problématiques neige ventée favorisant des structures de plaques récentes, parfois épaisses. Ce risque décroît progressivement à mesure que l'on descend en altitude, surtout sous 1500 m.

Départs spontanés : des ruptures naturelles de plaques peuvent se produire sous l'action du vent et des chutes de neige, pouvant atteindre la taille 2 à 3. Mardi au fil de la journée, rares avalanches de neige humide de taille 1 à 2 (petites à moyennes) non exclues dans les pentes raides exposées au soleil et près des rochers.

Qualité de la neige

Qualification de l'enneigement : L'enneigement s'est amélioré et est redevenu correct à bon pour la saison dès les vallées et en combes d'altitude. Les crêtes sont toutefois assez peu enneigées ainsi que les pentes Sud raides...

Limites skiables : à partir de 1100/1500 m.

Qualité de la neige mardi : neige récente en cours de tassement à l'abri du vent. Vers les crêtes, neige récente qui devient franchement plus dense, travaillée voire arrachée par le fort vent, parfois loin des crêtes. Sous 1800/2000 m la neige s'est davantage alourdie avec la pluie de la nuit. Les 10-20 cm de neige prévus d'ici mardi matin sur le sud-est du massif à plus de 2000 m (plutôt 5 à 10 cm sur le nord Grandes Rousses) sont souvent non visibles à cause du vent...

Aperçu météo pour le mardi 03 février

	nuit	matin	après-midi	soir

Tempête de sud et neige jusque mardi matin, puis le soleil revient peu à peu. Encore un peu de vent de sud mardi en journée.

Pluie-Neige	1 600 m	1 300 m		
Iso 0 °C	2 200 m	1 800 m	1 800 m	1 700 m
Vent 2000 m	↑ 80 km/h	↗ 60 km/h	↗ 45 km/h	↑ 35 km/h
Vent 3000 m	↑ 100 km/h	↗ 70 km/h	↗ 55 km/h	↑ 45 km/h

Épaisseur de neige hors-piste

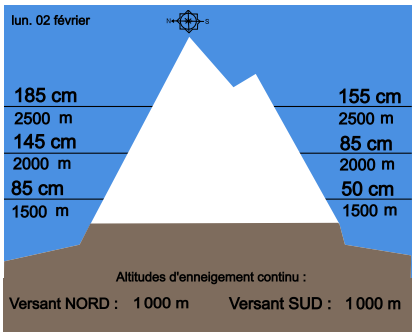

Précipitations à 1800 m

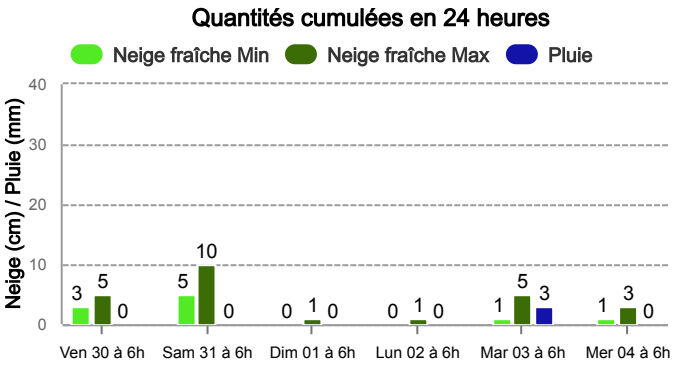

Tendance du mercredi 04 février

Indice de risque fort

Manteau neigeux restant instable ce mercredi Vent de sud 40-50 km/h.

Pour consulter la vigilance en cours, veuillez vous rendre sur le site https://vigilance.meteofrance.fr/fr

Météo-France - 73 avenue de Paris, 94165 Saint-Mandé cedex - Contact : contact@meteo.fr

Rédigé par Météo-France avec la contribution des observateurs du réseau nivo-météorologiques. Partenariat : ANMSM (Maires de Stations de Montagne), DSF (Domaines Skiables de France), ADSP (Directeurs de Pistes et de la Sécurité des Stations de Sports d'Hiver) et autres acteurs de la montagne.

Bulletin neige & avalanches par téléphone au **0 892 68 10 20** Service 0,35 € / min + prix appel

RÉPUBLIQUE FRANÇAISE
Liberté Égalité Fraternité

METEO FRANCE
À VOS CÔTÉS, DANS UN CLIMAT QUI CHANGE

Bulletin d'estimation du risque d'avalanche
(valable en dehors des pistes balisées et ouvertes)
MASSIF : Grandes-Rousses

Rédigé le lundi 2 février 2026 à 16h

Conditions nivo-météo des 7 derniers jours

	mar. 27/01				mer. 28/01				jeu. 29/01				ven. 30/01				sam. 31/01				dim. 01/02				lun. 02/02			
	03h	09h	15h	21h	03h	09h	15h	21h	03h	09h	15h	21h	03h	09h	15h	21h	03h	09h	15h	21h	03h	09h	15h	21h	03h	09h	15h	21h
Météo																												
Vent (km/h)	40	80	100	110	15	15	25	50	40	25	25	30	30	30	25	25	20	15	20	15	20	20	20	20	25	40	65	105
à 3000m																												
Vent (km/h)	30	75	85	95	0	5	25	35	25	15	10	10	15	15	15	10	10	10	15	10	10	10	10	10	15	25	50	90
à 2000m																												

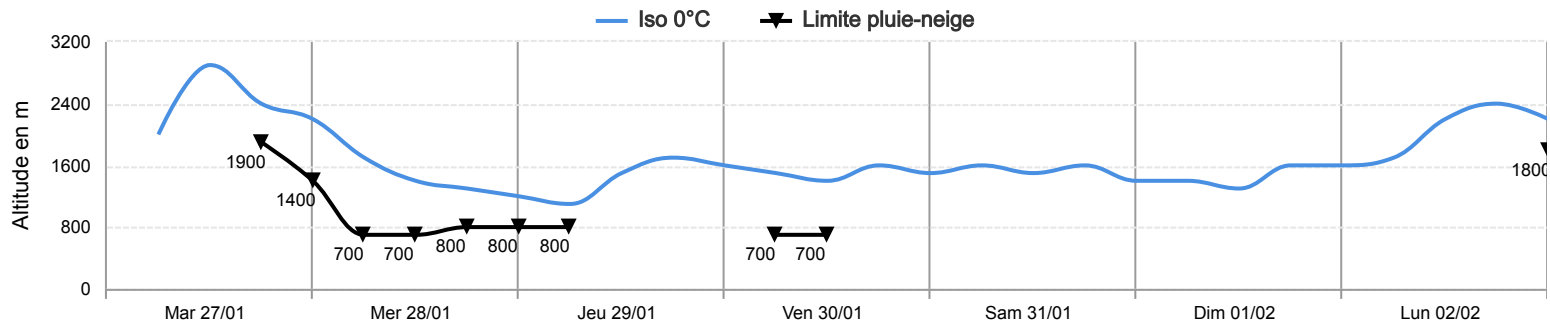

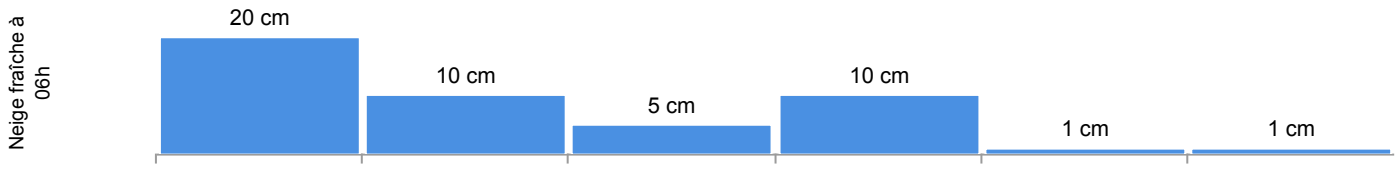

Risque d'avalanche							
	mar. 27/01	mer. 28/01	jeu. 29/01	ven. 30/01	sam. 31/01	dim. 01/02	lun. 02/02

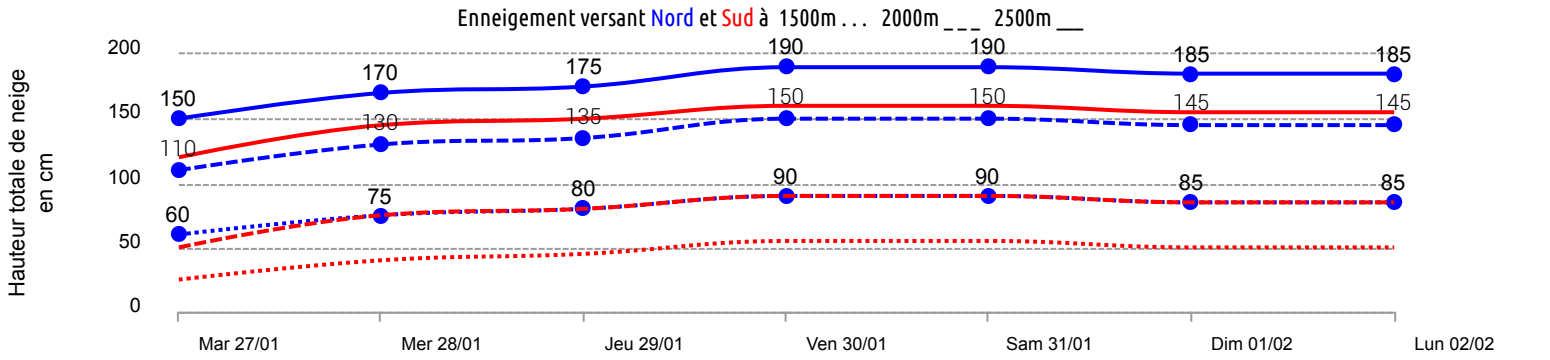

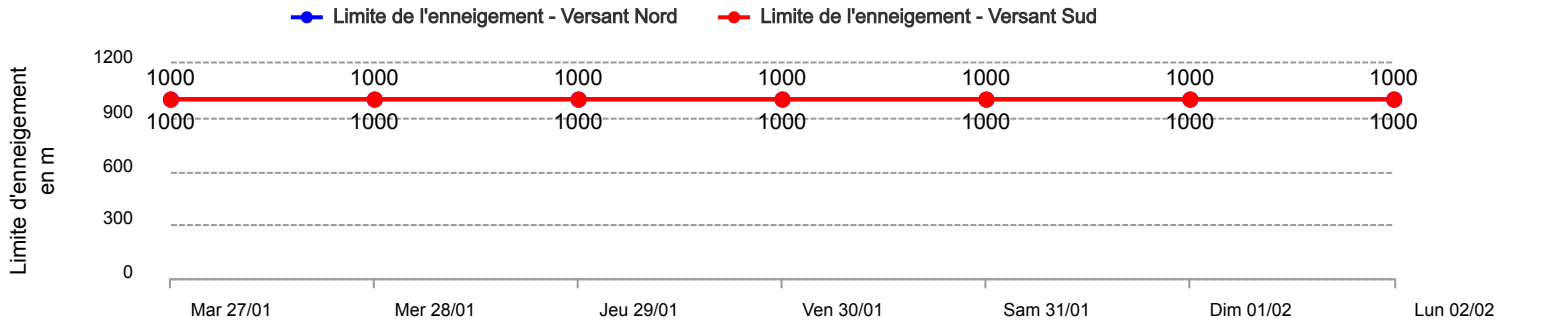

Pour consulter la vigilance en cours, veuillez vous rendre sur le site https://vigilance.meteofrance.fr/fr

Météo-France - 73 avenue de Paris, 94165 Saint-Mandé cedex - Contact : contact@meteo.fr

Rédigé par Météo-France avec la contribution des observateurs du réseau nivo-météorologiques. Partenariat : ANMSM (Maires de Stations de Montagne), DSF (Domaines Skiables de France), ADSP (Directeurs de Pistes et de la Sécurité des Stations de Sports d'Hiver) et autres acteurs de la montagne.

Bulletin neige & avalanches par téléphone au
0 892 68 10 20 Service 0,35 € / min + prix appel