RÉPUBLIQUE FRANÇAISE
Liberté Égalité Fraternité

METEO FRANCE
À VOS CÔTÉS, DANS UN CLIMAT QUI CHANGE

Bulletin d'estimation du risque d'avalanche
(valable en dehors des pistes balisées et ouvertes)
MASSIF : Haute-Tarentaise

Rédigé le lundi 2 février 2026 à 16h

Estimation des risques pour le : MARDI 03 FÉVRIER

NOMBREUSES PLAQUES "À VENT" REPOSANT SUR UN MANTEAU GLOBALEMENT INSTABLE.

3

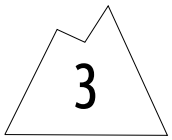

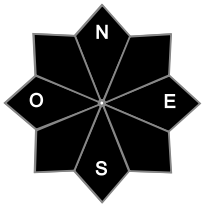

Même loin des crêtes

Indices de risque : 5 très fort - 4 fort - 3 marqué - 2 limité - 1 faible -- En noir : les pentes les plus dangereuses

Indice de risque marqué.

Départs spontanés : en net baisse en journée avec le vent qui tombe.

Déclenchements provoqués : nombreuses plaques. Couche fragile persistante dans de nombreuses pentes.

Stabilité du manteau neigeux

Situation avalancheuse typique : neige ventée couche fragile persistante

Déclenchements provoqués :
(1) Des plaques sont en place suite au fort coup de vent de Sud de la nuit de lundi à mardi. On le trouve en tous versants aussi bien **près des crêtes qu'en pied de pentes**. Tailles 2 (moyennes) avec des cassures très variables, pour une moyenne **de 40-60 cm** d'épaisseur. *Observables : indices de transport, accumulation ferme sous les skis.*
(2) La **couche fragile persistante** (**grains anguleux** semblables à du gros sel)**, enfouie** depuis plusieurs semaine, reste **généralisée dès 1800 m**, dans les pentes **Nord**, **Est** et **Ouest** mais **aussi en Sud à haute altitude**. Elle vient former une épaisse structure de plaque qui, en cas de déclenchement, entraîne l'ensemble du manteau neigeux. Déclenchement aléatoire, parfois possible à distance, provoquant des avalanches de taille 2 à 3 (grandes), avec des cassures s'approchant d'1m. *Observables : woumfs, tests CT/ECT pour identifier la couche fragile.*
A fortiori, une première avalanche dans la neige ventée (1) pourrait mobiliser en cascade la couche fragile enfouie (2).

Départs spontanés : en forte baisse avec l'arrêt progressif du vent. Rares décrochements de plaques dans les pentes raides sous le vent, le matin (tant que le vent souffle).

Qualité de la neige

Enneigement : tout à fait correct pour la saison.

Limite skiable : à basse altitude sur l'herbe. Sur terrain rocheux, gare à l'absence de sous-couche en-dessous de 1500 m en N, 2000 m en Sud.

Qualité de la neige : manteau neigeux travaillé par le vent. Il faut chercher les rares pentes protégées par situation de foehn pour skier de la neige encore poudreuse. Enfin, en Sud raide sous 2000/2200 m, la neige est faiblement croutée, potentiellement pénible à skier.

Aperçu météo pour le mardi 03 février

	nuit	matin	après-midi	soir
Belles éclaircies et baisse du vent l'après-midi.				
Pluie-Neige	1 400 m	1 200 m		
Iso 0 °C	2 200 m	1 900 m	1 800 m	1 700 m
Vent 2500 m	← 75 km/h	↖ 55 km/h	↑ 35 km/h	↙ 20 km/h
Vent 3500 m	↑ 90 km/h	↗ 75 km/h	↗ 50 km/h	↑ 35 km/h

Épaisseur de neige hors-piste

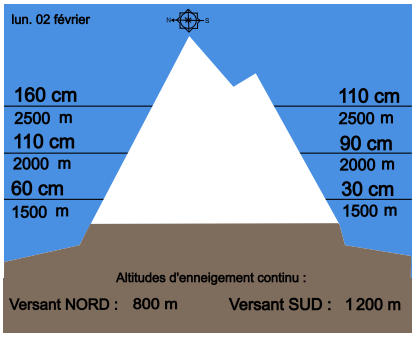

Précipitations à 1800 m

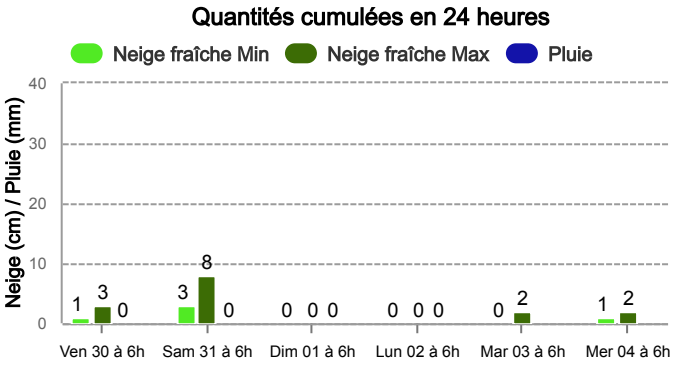

Tendance du mercredi 04 février

3

Indice de risque marqué

Très lente stabilisation d'un manteau globalement instable.

Pour consulter la vigilance en cours, veuillez vous rendre sur le site https://vigilance.meteofrance.fr/fr

Météo-France - 73 avenue de Paris, 94165 Saint-Mandé cedex - Contact : contact@meteo.fr

Rédigé par Météo-France avec la contribution des observateurs du réseau nivo-météorologiques. Partenariat : ANMSM (Maires de Stations de Montagne), DSF (Domaines Skiables de France), ADSP (Directeurs de Pistes et de la Sécurité des Stations de Sports d'Hiver) et autres acteurs de la montagne.

Bulletin neige & avalanches par téléphone au
0 892 68 10 20 Service 0,35 € / min + prix appel

Bulletin d'estimation du risque d'avalanche

(valable en dehors des pistes balisées et ouvertes)

MASSIF : Haute-Tarentaise

Rédigé le lundi 2 février 2026 à 16h

Conditions nivo-météo des 7 derniers jours

	mar. 27/01				mer. 28/01				jeu. 29/01				ven. 30/01				sam. 31/01				dim. 01/02				lun. 02/02			
	03h	09h	15h	21h	03h	09h	15h	21h	03h	09h	15h	21h	03h	09h	15h	21h	03h	09h	15h	21h	03h	09h	15h	21h	03h	09h	15h	21h
Météo																												
Vent (km/h)	25	35	50	60	45	30	30	35	45	25	20	30	40	40	35	30	30	20	20	20	20	20	30	30	40	45	60	85
à 3500m																												
Vent (km/h)	10	20	35	45	35	20	15	20	20	15	15	10	10	15	20	10	10	10	10	10	10	10	10	10	10	25	45	70
à 2500m																												

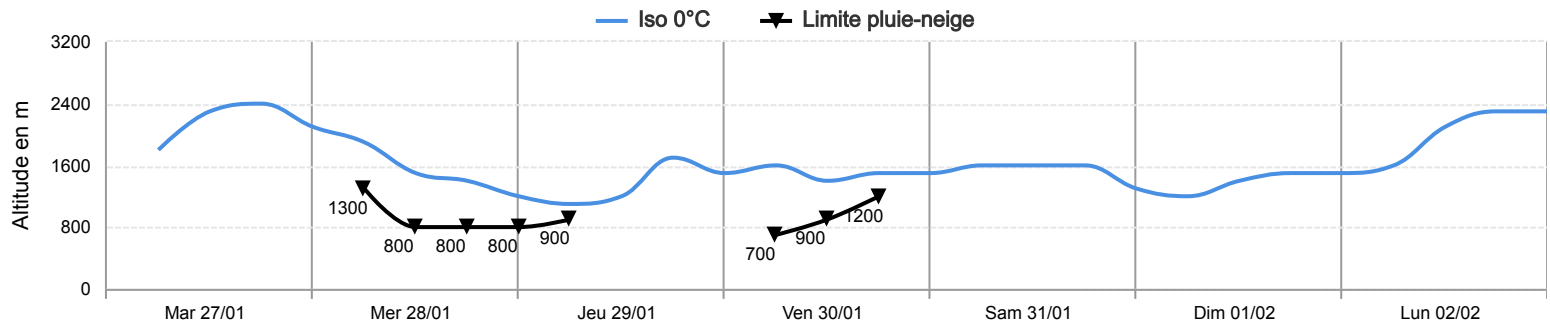

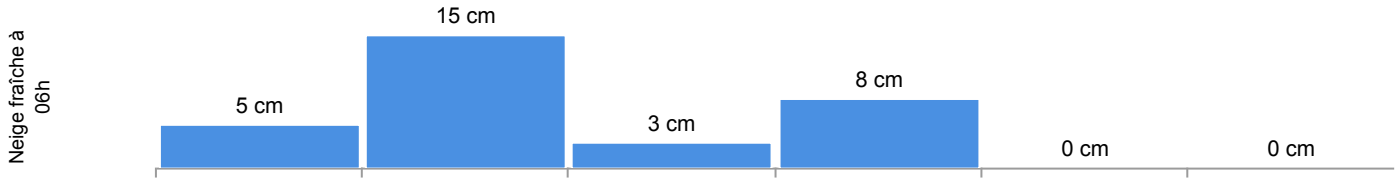

Risque d'avalanche	mar. 27/01	mer. 28/01	jeu. 29/01	ven. 30/01	sam. 31/01	dim. 01/02	lun. 02/02
	3	3	3	3	3	3	3

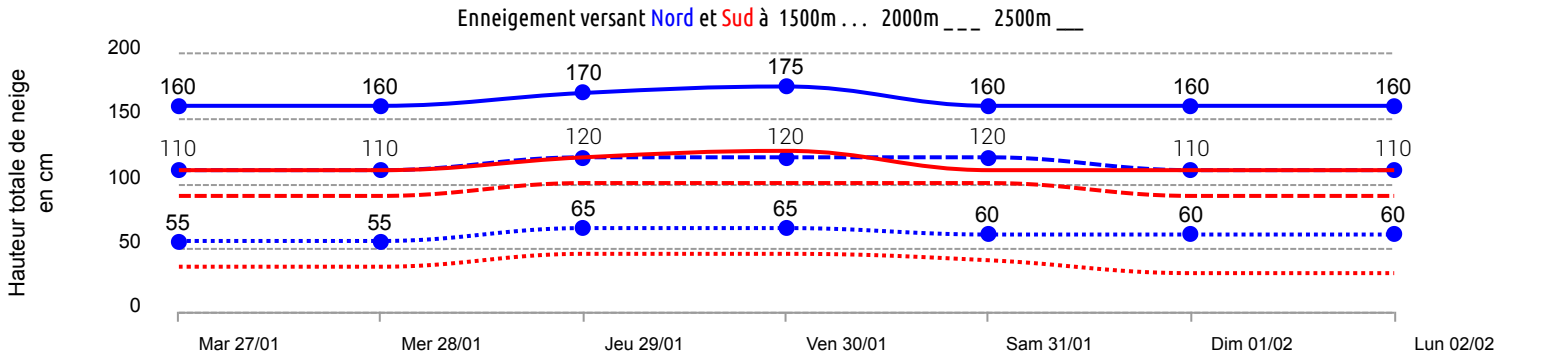

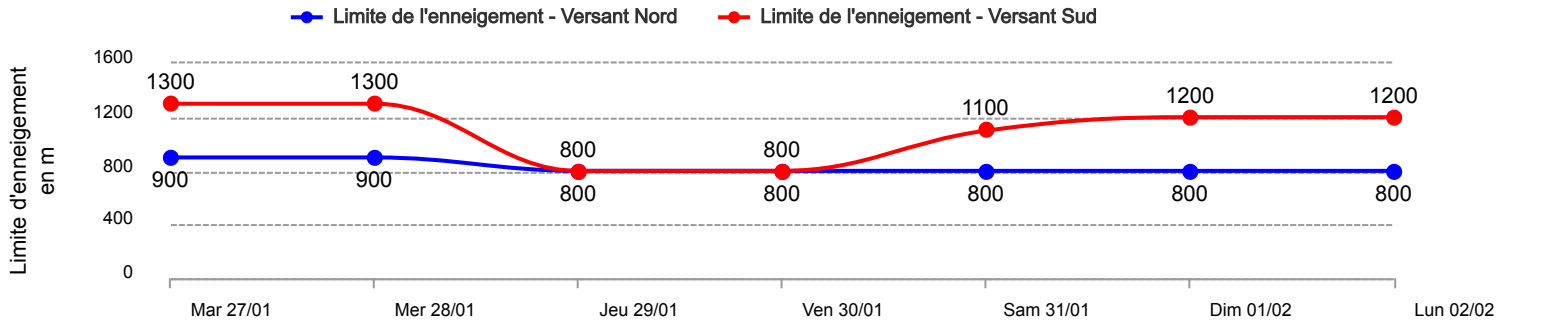

Pour consulter la vigilance en cours, veuillez vous rendre sur le site https://vigilance.meteofrance.fr/fr

Météo-France - 73 avenue de Paris, 94165 Saint-Mandé cedex - Contact : contact@meteo.fr

Rédigé par Météo-France avec la contribution des observateurs du réseau nivo-météorologiques. Partenariat : ANMSM (Maires de Stations de Montagne), DSF (Domaines Skiables de France), ADSP (Directeurs de Pistes et de la Sécurité des Stations de Sports d'Hiver) et autres acteurs de la montagne.

Bulletin neige & avalanches par téléphone au

0 892 68 10 20 Service 0,35 € / min + prix appel