Bulletin d'estimation du risque d'avalanche
(valable en dehors des pistes balisées et ouvertes)

MASSIF : Mercantour

Rédigé le lundi 2 février 2026 à 16h

Estimation des risques pour le : MARDI 03 FÉVRIER

NEIGE ABONDANTE, FORTE INSTABILITÉ DU MANTEAU NEIGEUX

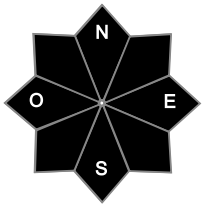

Indice de risque fort.

Départs spontanés : nombreuses avalanches de neige fraîche, localement de très grande taille.

Déclenchements provoqués : forte instabilité dans la neige fraîche ventée.

Indices de risque : 5 très fort - 4 fort - 3 marqué - 2 limité - 1 faible -- En noir : les pentes les plus dangereuses

Stabilité du manteau neigeux

Situation avalancheuse typique : neige fraîche couche fragile persistante

Départs spontanés : dans la nuit de lundi à mardi et mardi matin, nombreux départs ponctuels liés aux fortes chutes de neige, de taille moyenne à grande (taille 2 à 3) avec aérosol. Dans les zones de départ situées en versants est, nord et ouest d'altitude, des départs linéaires de très grande taille (taille 4) sont possibles, s'approchant voir atteignant certains fonds de vallées. Cette activité naturelle faiblit en journée, mais des départs spontanés volumineux restent possibles avec le maintien d'un vent de sud modérée, favorisant le transport de la neige fraiche.

Déclenchements provoqués :
Nombreuses plaques en place dans la neige fraîche, principalement au-dessus de 1600/1800 m. Plaques dures/travaillées par le vent proche des crêtes, mais d'aspect friable dans les secteurs plus abrités, possibles même en forêt, et très facile à déclencher. Elles génèrent des avalanches de taille moyenne à grande (taille 2 à 3) notamment dans les zones de forte accumulation par le vent. En versant est, nord et ouest au-dessus de 1800/2000 des avalanches de très grande taille sont possibles par sollicitation de couches fragiles enfouies, emportant alors la totalité du manteau neigeux.

Qualité de la neige

Enneigement excédentaire à basse altitude pour une fin janvier.
Données observées : 111 cm à la nivôse de Millefonts à 2400 m, 106 à Isola 2000.

Enneigement skiable dès 1200/1300 m en terrain favorable, mais peu de sous-couche sous 1600 m en général.

État de la neige en surface : épaisse couche de neige récente : 10/20 cm à 1500 m, 30/50 cm à partir de 1800 m. Cette neige est humide à collante en toutes orientations sous 1700/1800 m, froide et légère au-dessus, mais fortement travaillée par le vent de sud-est en altitude et dans les secteurs exposés. Corniches parfois volumineuses en place sur les crêtes.

Aperçu météo pour le mardi 03 février

	nuit	matin	après-midi	soir
	Averses de neige éparses en journée, s'estompant en cours d'après-midi. Cumuls de l'ordre de 1 à 5 cm sous averses.			
Pluie-Neige	1 600 m	1 300 m	1 400 m	
Iso 0 °C	1 800 m	1 600 m	1 700 m	1 500 m
Vent 2000 m	↖ 25 km/h	↗ 40 km/h	↗ 25 km/h	↑ 15 km/h
Vent 3000 m	↑ 80 km/h	↑ 65 km/h	↗ 45 km/h	↗ 30 km/h

Épaisseur de neige hors-piste

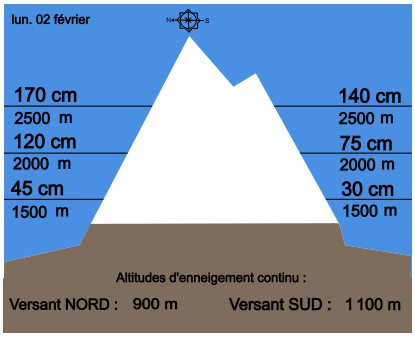

Précipitations à 1800 m

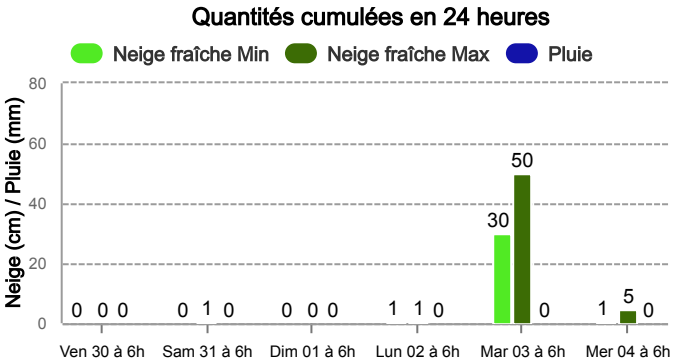

Tendance du mercredi 04 février

Indice de risque fort

Maintien d'un risque accidentel fort avec des plaques encore instables et volumineuses dans la neige fraiche ventée.

Pour consulter la vigilance en cours, veuillez vous rendre sur le site https://vigilance.meteofrance.fr/fr

Météo-France - 73 avenue de Paris, 94165 Saint-Mandé cedex - Contact : contact@meteo.fr

Rédigé par Météo-France avec la contribution des observateurs du réseau nivo-météorologiques. Partenariat : ANMSM (Maires de Stations de Montagne), DSF (Domaines Skiables de France), ADSP (Directeurs de Pistes et de la Sécurité des Stations de Sports d'Hiver) et autres acteurs de la montagne.

Bulletin neige & avalanches par téléphone au
0 892 68 10 20 Service 0,35 € / min + prix appel

RÉPUBLIQUE FRANÇAISE
Liberté Égalité Fraternité

METEO FRANCE
À VOS CÔTÉS, DANS UN CLIMAT QUI CHANGE

Bulletin d'estimation du risque d'avalanche

(valable en dehors des pistes balisées et ouvertes)

MASSIF : Mercantour

Rédigé le lundi 2 février 2026 à 16h

Conditions nivo-météo des 7 derniers jours

	mar. 27/01				mer. 28/01				jeu. 29/01				ven. 30/01				sam. 31/01				dim. 01/02				lun. 02/02			
	03h	09h	15h	21h	03h	09h	15h	21h	03h	09h	15h	21h	03h	09h	15h	21h	03h	09h	15h	21h	03h	09h	15h	21h	03h	09h	15h	21h
Météo																												
Vent (km/h)	35	60	70	70	50	40	10	15	50	45	25	20	35	40	35	20	20	20	30	20	15	15	20	20	25	35	45	60
à 3000m																												
Vent (km/h)	10	20	30	10	10	10	10	15	20	15	15	10	10	15	15	10	10	15	20	10	15	10	10	10	10	10	20	25
à 2000m																												

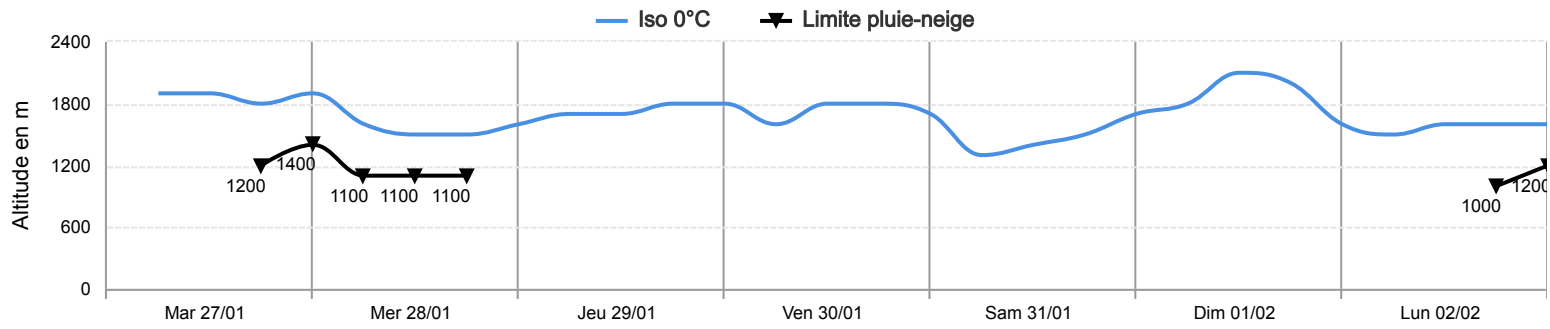

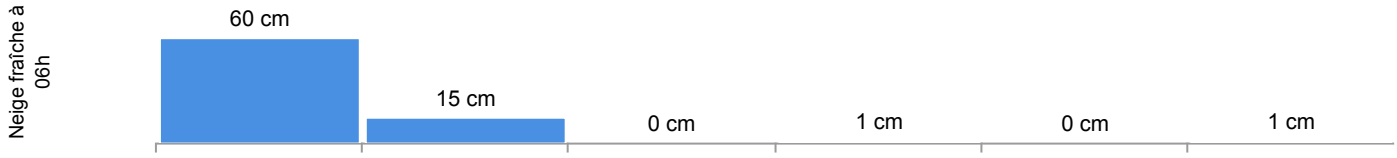

Risque d'avalanche	mar. 27/01	mer. 28/01	jeu. 29/01	ven. 30/01	sam. 31/01	dim. 01/02	lun. 02/02
	4	4	4	3	3	3	3

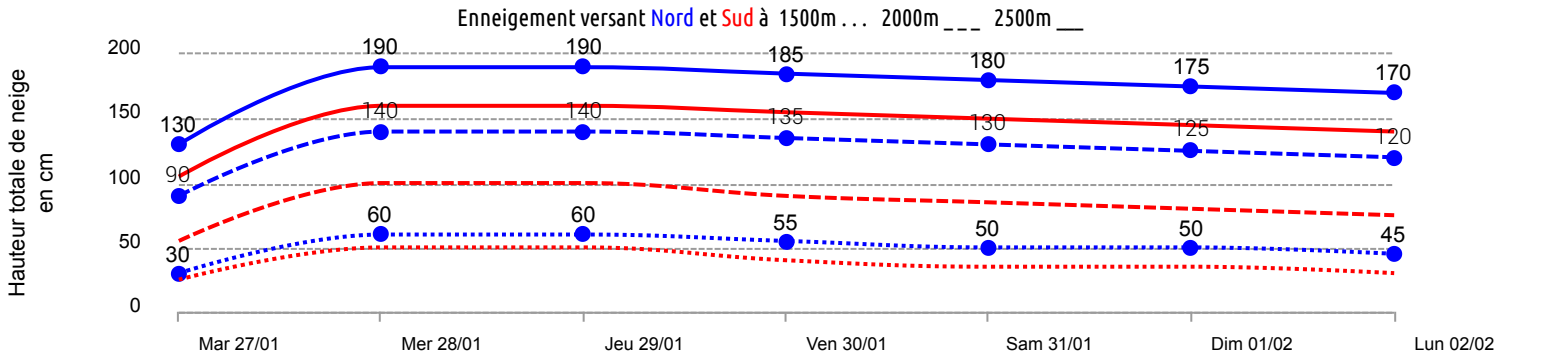

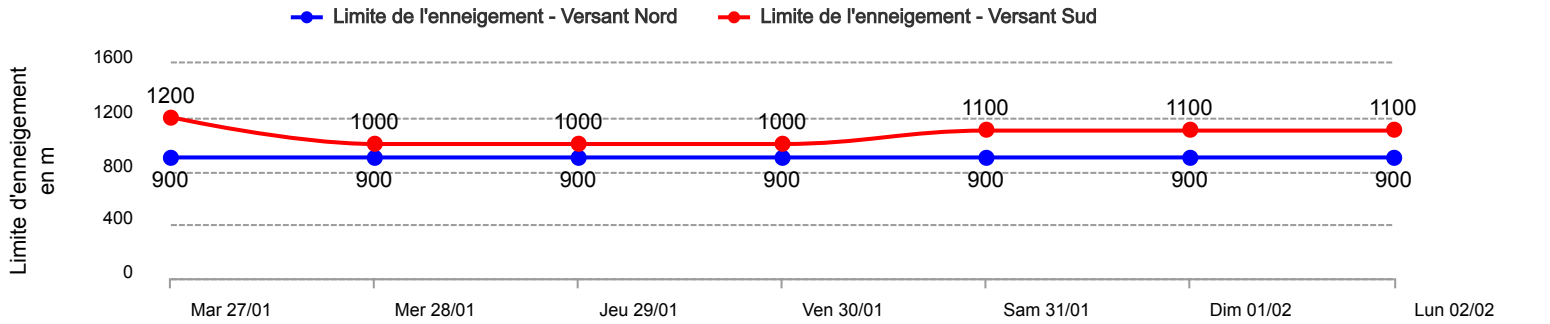

Pour consulter la vigilance en cours, veuillez vous rendre sur le site https://vigilance.meteofrance.fr/fr

Météo-France - 73 avenue de Paris, 94165 Saint-Mandé cedex - Contact : contact@meteo.fr

Rédigé par Météo-France avec la contribution des observateurs du réseau nivo-météorologiques. Partenariat : ANMSM (Maires de Stations de Montagne), DSF (Domaines Skiables de France), ADSP (Directeurs de Pistes et de la Sécurité des Stations de Sports d'Hiver) et autres acteurs de la montagne.

Bulletin neige & avalanches par téléphone au

0 892 68 10 20 Service 0,35 € / min + prix appel