Bulletin d'estimation du risque d'avalanche

(valable en dehors des pistes balisées et ouvertes)

MASSIF : Orlu St-Barthelemy

Rédigé le lundi 2 février 2026 à 16h

Estimation des risques pour le : MARDI 03 FÉVRIER

MANTEAU ENCORE INSTABLE EN ALTITUDE

3

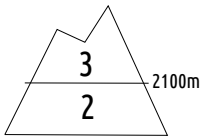

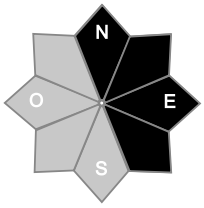

Au-dessus de 2100m indice de risque marqué, plus bas indice limité.

Départs spontanés : Suivant l'altitude, par surcharge due au vent ou par humidification en profondeur

Déclenchements provoqués : Structures de plaques en altitude, plus épaisses dans un large secteur est

Indices de risque : 5 très fort - 4 fort - 3 marqué - 2 limité - 1 faible -- En noir : les pentes les plus dangereuses

Stabilité du manteau neigeux

Situation avalancheuse typique : neige ventée avalanches de fond

Déclenchements provoqués :

* En altitude, au dessus de 2100m, le manteau neigeux reste instable en de nombreuses orientations et des structures de plaques déclenchables parfois par le passage d'un simple randonneur sont en place et continuent de se former. Elles sont plus épaisses dans un large secteur nord à sud-est, où elles peuvent occasionner des avalanches moyennes à grandes plus rarement (tailles 2 à 3). Situées parfois loin des crêtes, leur détection sur le terrain n'est pas toujours aisée.
* En dessous de 2100m, le manteau neigeux s'est bien humidifié lundi, et a souvent regelé dans la nuit, assurant une bonne cohésion en surface. Le risque de déclencher une avalanche y est donc plus faible.

Départs spontanés :

* En altitude, au dessus de 2100m, le transport de neige par le vent de sud-ouest pourra entrainer par surcharge, le départ spontané de structures de plaques décrites ci-dessus (avalanches de taille petite à moyenne, plus rarement grandes).
* Sous 2000/2100 m dans les pentes raides, en toutes orientations, l'humidification en profondeur du manteau neigeux se poursuivra et des avalanches spontanées pourront localement entrainer l'ensemble de la neige récente, parfois même jusqu'au sol en terrain herbeux ou sur des dalles lisses (Taille 1 à 2, rarement 3). Des fissures et des débuts de reptations peuvent être des signes précurseurs à ces départs qui sans être généralisés, pourront se produire à tout moment.

Qualité de la neige

Enneigement :

Enneigement excellent et excédentaire pour la saison, avec des cumuls importants de neige récente en montagne. Mardi matin, on pourra chausser les skis dès 1100 m en nord et plutôt 1200/1300 m au sud.

État de la neige :

Lundi matin, en dessous de 2100m, on trouvera quelques cm de neige fraiche recouvrant une croute plus ou moins portante de neige humide regelée dans la nuit. Plus haut, la neige est restée froide, mais travaillée par le vent proche des crêtes avec des épaisseurs hétérogènes, de la neige parfois dure et des sastrugis. On pourra encore trouver de la neige légère et poudreuse dans les combes d'altitude abritées du vent. En journée, la neige va peu évoluer, mis à part dans les pentes raides ensoleillées en dessous de 1800m où elle va s'humidifier un peu en surface.

Aperçu météo pour le mardi 03 février

	nuit	matin	après-midi	soir
	Refroidissement, arrêt des précipitations et vent plus faible mais toujours présent			
Pluie-Neige	1 500 m			
Iso 0 °C	2 100 m	1 600 m	1 600 m	1 600 m
Vent 2000 m	40 km/h	25 km/h	25 km/h	25 km/h
Vent 3000 m	60 km/h	35 km/h	40 km/h	25 km/h

Épaisseur de neige hors-piste

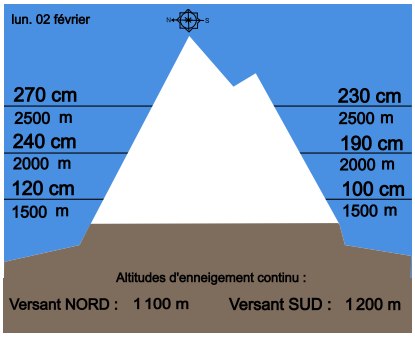

Précipitations à 1800 m

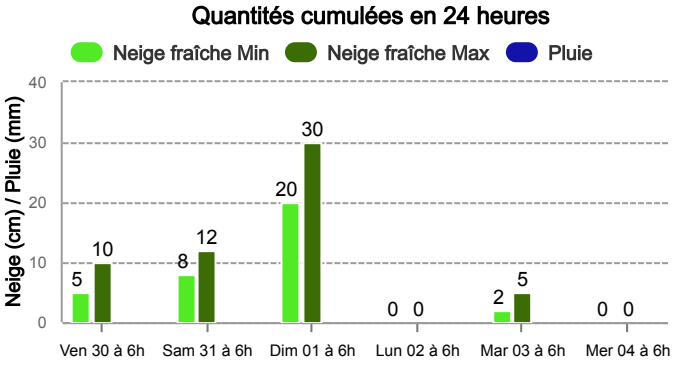

Tendance du mercredi 04 février

3

Indice de risque marqué

Maintien du risque 3 avec nouvel épisode de transport

Pour consulter la vigilance en cours, veuillez vous rendre sur le site https://vigilance.meteofrance.fr/fr

Météo-France - 73 avenue de Paris, 94165 Saint-Mandé cedex - Contact : contact@meteo.fr

Rédigé par Météo-France avec la contribution des observateurs du réseau nivo-météorologiques. Partenariat : ANMSM (Maires de Stations de Montagne), DSF (Domaines Skiables de France), ADSP (Directeurs de Pistes et de la Sécurité des Stations de Sports d'Hiver) et autres acteurs de la montagne.

Bulletin neige & avalanches par téléphone au

0 892 68 10 20 Service 0,35 € / min + prix appel

Bulletin d'estimation du risque d'avalanche

(valable en dehors des pistes balisées et ouvertes)

MASSIF : Orlu St-Barthelemy

Rédigé le lundi 2 février 2026 à 16h

Conditions nivo-météo des 7 derniers jours

	mar. 27/01				mer. 28/01				jeu. 29/01				ven. 30/01				sam. 31/01				dim. 01/02				lun. 02/02			
	03h	09h	15h	21h	03h	09h	15h	21h	03h	09h	15h	21h	03h	09h	15h	21h	03h	09h	15h	21h	03h	09h	15h	21h	03h	09h	15h	21h
Météo																												
Vent (km/h)	60	85	85	60	40	50	50	55	50	50	55	75	80	70	60	40	65	75	80	70	60	40	30	30	45	70	100	70
à 3000m																												
Vent (km/h)	30	55	55	30	25	35	35	35	30	30	40	50	55	45	45	25	35	55	55	50	40	25	20	15	20	45	75	50
à 2000m																												

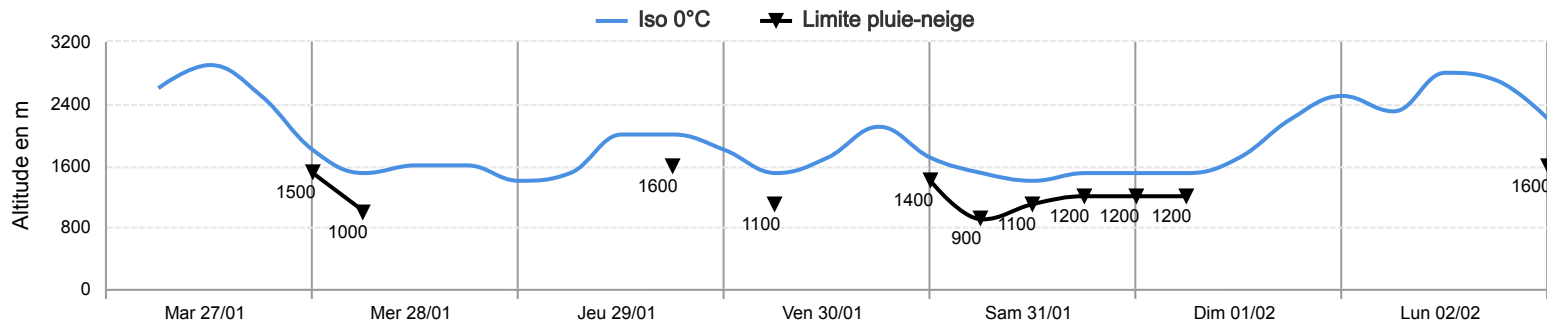

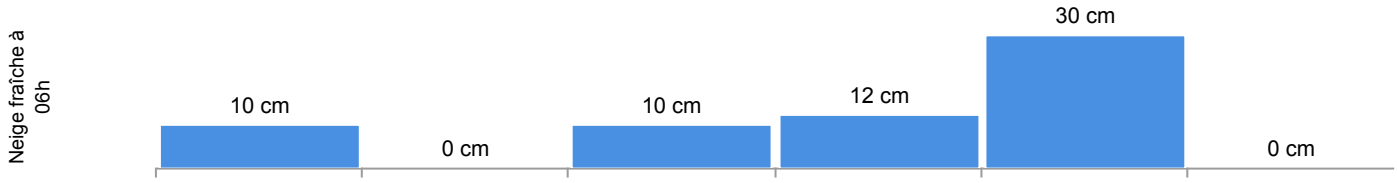

Risque d'avalanche	mar. 27/01	mer. 28/01	jeu. 29/01	ven. 30/01	sam. 31/01	dim. 01/02	lun. 02/02
	4	3	3	3	4	4	3

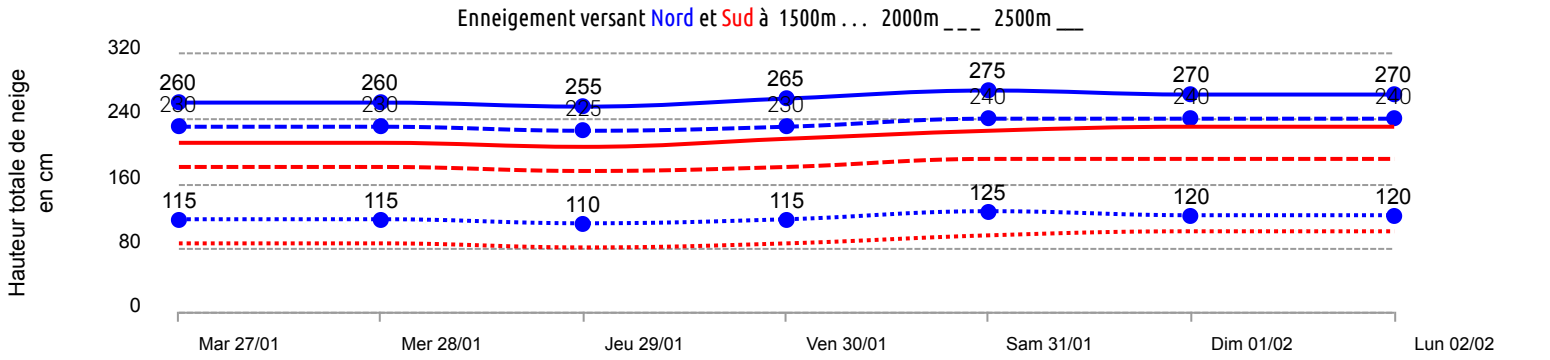

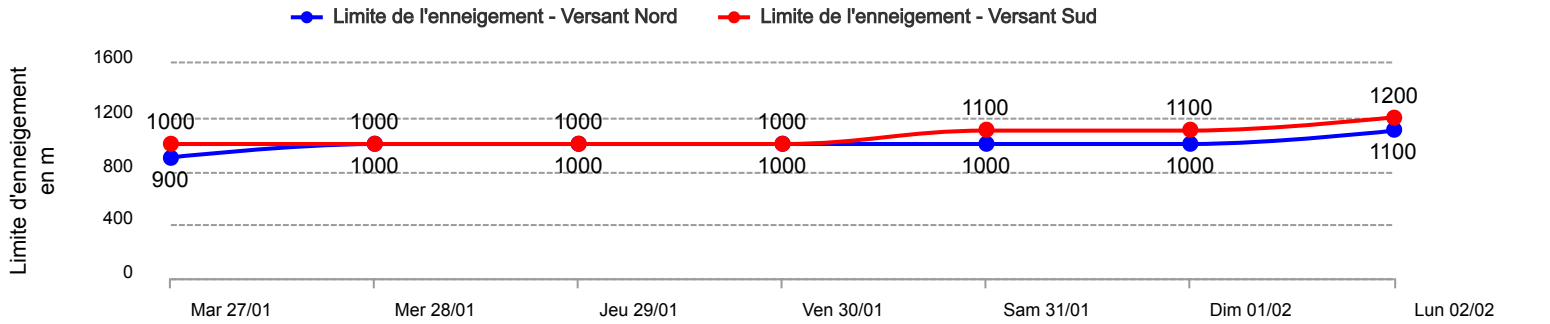

Pour consulter la vigilance en cours, veuillez vous rendre sur le site https://vigilance.meteofrance.fr/fr

Météo-France - 73 avenue de Paris, 94165 Saint-Mandé cedex - Contact : contact@meteo.fr

Rédigé par Météo-France avec la contribution des observateurs du réseau nivo-météorologiques. Partenariat : ANMSM (Maires de Stations de Montagne), DSF (Domaines Skiables de France), ADSP (Directeurs de Pistes et de la Sécurité des Stations de Sports d'Hiver) et autres acteurs de la montagne.

Bulletin neige & avalanches par téléphone au

0 892 68 10 20 Service 0,35 € / min + prix appel