Bulletin d'estimation du risque d'avalanche
(valable en dehors des pistes balisées et ouvertes)

MASSIF : Pays-Basque

Rédigé le lundi 2 février 2026 à 16h

Estimation des risques pour le : MARDI 03 FÉVRIER

NEIGE VENTÉE EN ALTITUDE, HUMIDIFICATION PLUS BAS.

2

2

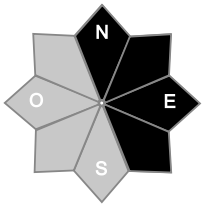

Plaques en altitude.

Indice de risque limité.

Départs spontanés : Départs ponctuels en neige ventée et humide, avalanches de fond possibles.

Déclenchements provoqués : Plaques en altitude.

Indices de risque : 5 très fort - 4 fort - 3 marqué - 2 limité - 1 faible -- En noir : les pentes les plus dangereuses

Stabilité du manteau neigeux

Situation avalancheuse typique : neige ventée — neige humide

Déclenchements provoqués :
Quelques plaques à vent peu épaisses se forment ce mardi, venant se superposer sur des plaques plus épaisses provenant des chutes de neige de la veille. Elles restent facilement déclenchables par un simple skieur et leur rupture peut engendrer des cassures linéaires petites à moyennes (taille 1 à 2), plus rarement des grandes (taille 3) dans les pentes raides des versants allant du Nord au Sud-Est.

Départs spontanés :
Des départs ponctuels de plaques décrites ci-dessus restent possibles, par surcharge par le vent, engendrant ainsi des avalanches petites à moyennes (taille 1 à 2), plus rarement des grandes (taille 3) en particulier dans les pentes raides des versants allant du Nord au Sud-Est.
Avec l'humidification de la veille, des départs ponctuels sont attendus en journée, de taille petite à moyenne (taille 1 à 2) généralement, plus rarement de grande taille (taille 3) dans les versants Nord à Sud-Est. Des avalanches de fond restent aussi possibles lorsque l'humidification atteint le sol, engendrant ainsi des avalanches moyennes (taille 2), à parfois grandes (taille 3) dans les zones d'accumulation les plus importantes.

Qualité de la neige

Enneigement : L'enneigement est assez bon pour la saison, mais les crêtes, cols et sommets sont souvent pelés par le vent en altitude dans les expositions ouest. Le manteau neigeux s'est bien humidifié lundi sous 1800m, se réduisant progressivement. Nouvelles chutes de neige mardi, surtout en secteur frontalier dès 1200m, venant s'ajouter à celles de lundi après-midi.
Limites skiables : Manteau neigeux skiable à partir de 1400/1500m ce mardi, bien humidifié en-dessous.
État de la neige : Neige croûtée sous 1500/1600m ce mardi matin, plus souvent travaillée par le vent de Sud à Sud-Ouest au-dessus.

Aperçu météo pour le mardi 03 février

Sommets frontaliers accrochés dès la matinée, ciel voilé ailleurs. Quelques averses de neige en journée. Vent de Sud à Sud-Ouest modéré à assez fort.

	nuit	matin	après-midi	soir
Pluie-Neige	1 000 m	1 100 m	1 100 m	1 000 m
Iso 0 °C	1 500 m	1 600 m	1 700 m	1 800 m
Vent 1000 m	55 km/h	60 km/h	55 km/h	65 km/h
Vent 2000 m	80 km/h	80 km/h	80 km/h	90 km/h

Épaisseur de neige hors-piste

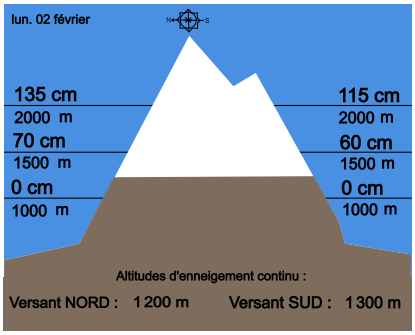

Précipitations à 1800 m

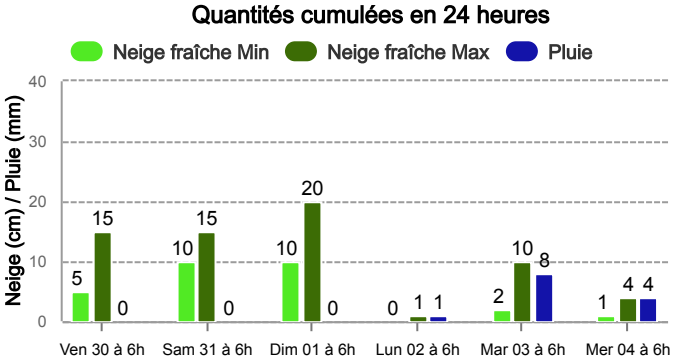

Tendance du mercredi 04 février

2

Indice de risque limité

Maintien d'un risque limité. Quelques averses de neige sous un vent parfois assez fort de Sud-Ouest le matin, basculant Ouest/Nord-Ouest ensuite.

Pour consulter la vigilance en cours, veuillez vous rendre sur le site https://vigilance.meteofrance.fr/fr

Météo-France - 73 avenue de Paris, 94165 Saint-Mandé cedex - Contact : contact@meteo.fr

Rédigé par Météo-France avec la contribution des observateurs du réseau nivo-météorologiques. Partenariat : ANMSM (Maires de Stations de Montagne), DSF (Domaines Skiables de France), ADSP (Directeurs de Pistes et de la Sécurité des Stations de Sports d'Hiver) et autres acteurs de la montagne.

Bulletin neige & avalanches par téléphone au
0 892 68 10 20 Service 0,35 € / min + prix appel

Bulletin d'estimation du risque d'avalanche

(valable en dehors des pistes balisées et ouvertes)

MASSIF : Pays-Basque

Rédigé le lundi 2 février 2026 à 16h

Conditions nivo-météo des 7 derniers jours

	mar. 27/01				mer. 28/01				jeu. 29/01				ven. 30/01				sam. 31/01				dim. 01/02				lun. 02/02			
	03h	09h	15h	21h	03h	09h	15h	21h	03h	09h	15h	21h	03h	09h	15h	21h	03h	09h	15h	21h	03h	09h	15h	21h	03h	09h	15h	21h
Météo																												
Vent (km/h)	110	75	70	55	40	40	55	60	65	80	75	75	80	95	65	80	70	90	90	60	70	45	50	80	95	120	120	80
à 2000m																												
Vent (km/h)	80	50	35	20	15	10	25	35	45	50	50	50	50	65	40	50	50	70	70	35	30	30	40	60	60	90	90	55
à 1000m																												

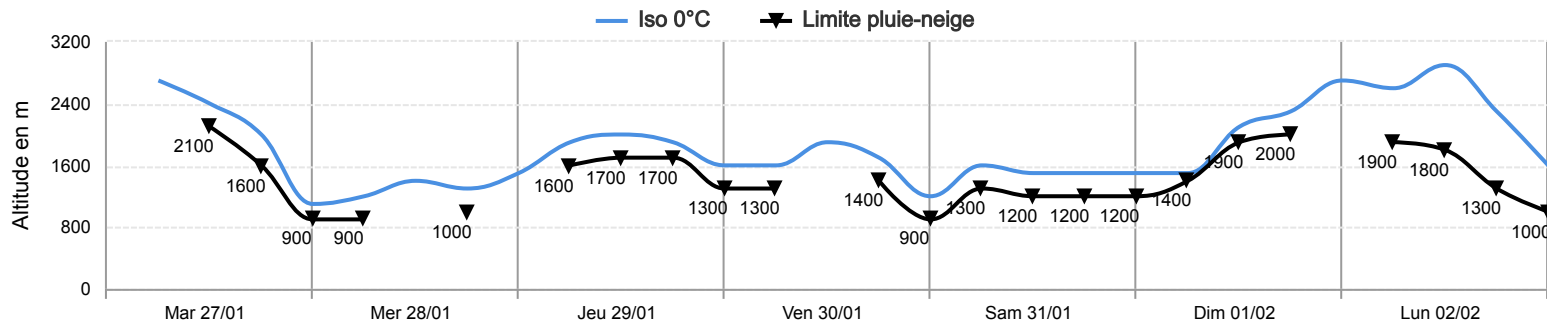

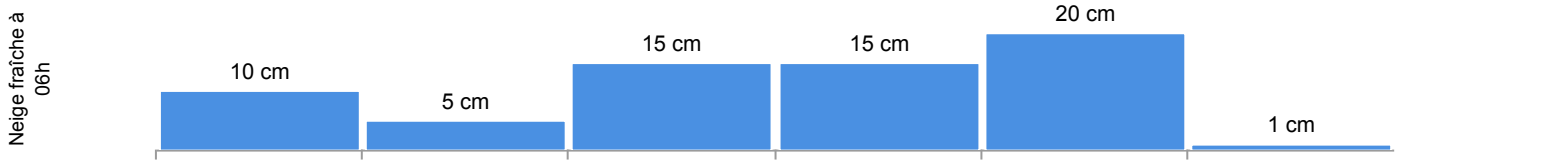

Risque d'avalanche	mar. 27/01	mer. 28/01	jeu. 29/01	ven. 30/01	sam. 31/01	dim. 01/02	lun. 02/02
	3	2	2	3	4	3	3

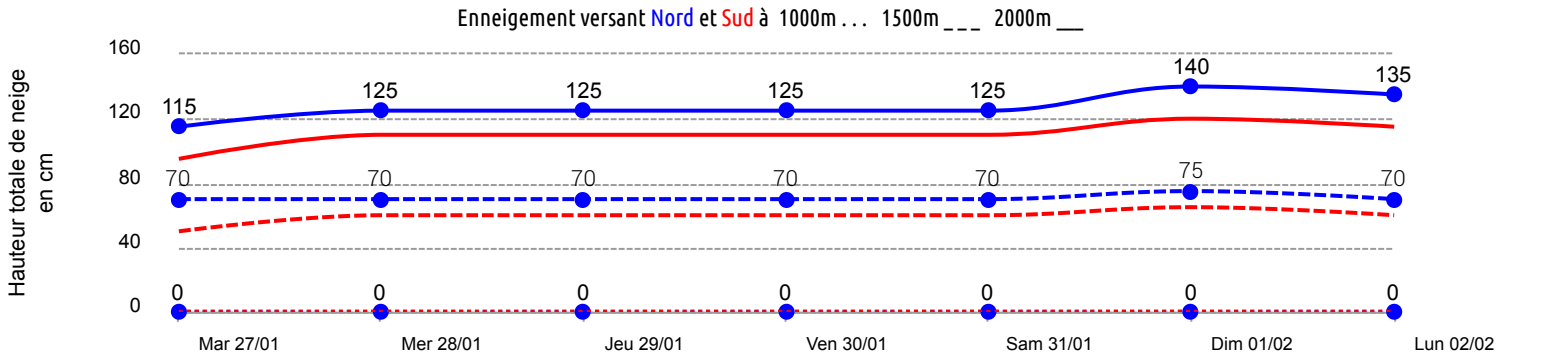

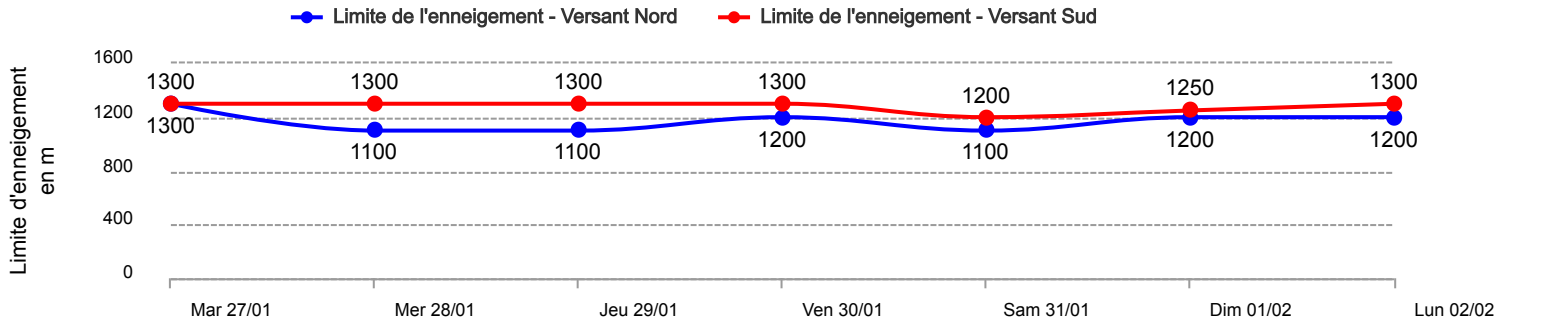

Pour consulter la vigilance en cours, veuillez vous rendre sur le site https://vigilance.meteofrance.fr/fr

Météo-France - 73 avenue de Paris, 94165 Saint-Mandé cedex - Contact : contact@meteo.fr

Bulletin neige & avalanches par téléphone au

0 892 68 10 20 Service 0,35 € / min + prix appel

Rédigé par Météo-France avec la contribution des observateurs du réseau nivo-météorologiques. Partenariat : ANMSM (Maires de Stations de Montagne), DSF (Domaines Skiables de France), ADSP (Directeurs de Pistes et de la Sécurité des Stations de Sports d'Hiver) et autres acteurs de la montagne.