Bulletin d'estimation du risque d'avalanche

(valable en dehors des pistes balisées et ouvertes)

MASSIF : Vercors

Rédigé le lundi 2 février 2026 à 16h

Estimation des risques pour le : MARDI 03 FÉVRIER

FORMATION DE NOUVELLES INSTABILITÉS DANS LES VERSANTS FROIDS, SOUS LE VENT DE SUD QUI SE RENFORCE CE LUNDI.

3

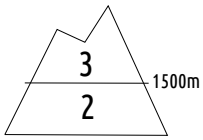

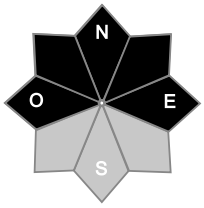

Au-dessus de 1500m indice de risque marqué, plus bas indice limité.

Départs spontanés : quelques ruptures naturelles en plaques sous le vent, vers les sommets. Rares départs humides sous les éclaircies mardi.

Déclenchements provoqués : instabilités récentes sous le vent de sud, en particulier dans les versants froids d'altitude.

Indices de risque : 5 très fort - 4 fort - 3 marqué - 2 limité - 1 faible -- En noir : les pentes les plus dangereuses

Stabilité du manteau neigeux

Situation avalancheuse typique : neige ventée

Déclenchements provoqués : le vent de sud à sud-ouest qui souffle depuis ce lundi et qui se renforce dans la nuit (100 km/h et plus sur les crêtes), favorise et va favoriser la formation de nombreuses plaques, y compris loin des crêtes, surtout dans un large Nord (Ouest, Nord et Est). Ruptures faciles au passage d'un skieur sur de nombreuses pentes, surtout en plaques dures, avec des épaisseurs de cassures non négligeables. De plus, un peu de neige est annoncée (très ventée) d'ici mardi matin, 5 cm vers les sommets peut-être 10 cm au sud du massif, suffisant pour amplifier le phénomène. Ces nouvelles instabilités peuvent être réactives et faciles à déclencher par un seul pratiquant. Sous 1400/1600 m environ, le risque devrait rester plus limité, la neige récente s'étant davantage alourdie/humidifiée.

Départs spontanés : quelques ruptures naturelles possibles sous le vent, taille 1 à 2 en général, plus rarement de taille 3. En journée de mardi, rares avalanches de neige humide de taille 1 à 2 (petites à moyennes) possibles dans les pentes raides qui seront exposées au soleil et près des rochers.

Qualité de la neige

Qualification de l'enneigement : l'enneigement s'est récemment amélioré et est devenu correct voire bon pour la saison, notamment en prairies/pistes forestières mais le vent de Sud attendu va dégrader la situation...

Limites skiables : vers 900/1200 m, hors sapins.

Qualité de la neige mardi : à l'abri du vent encore de la neige récente peu ventée mais humidifiée..parfois croûtée. Vers les crêtes, avec le vent fort en cours la neige est rapidement densifiée/dure voire totalement soufflée, faisant ressortir des cailloux par endroits.

Aperçu météo pour le mardi 03 février

	nuit	matin	après-midi	soir

Tempête de sud et neige jusque mardi matin, puis le soleil revient peu à peu. Encore un peu de vent de sud mardi en journée.

Pluie-Neige	1 600 m	1 300 m		
Iso 0 °C	2 200 m	1 600 m	1 700 m	1 700 m
Vent 1500 m	↑ 110 km/h	↑ 55 km/h	↑ 40 km/h	↑ 40 km/h
Vent 2000 m	↑ 125 km/h	↑ 70 km/h	↑ 55 km/h	↑ 55 km/h

Épaisseur de neige hors-piste

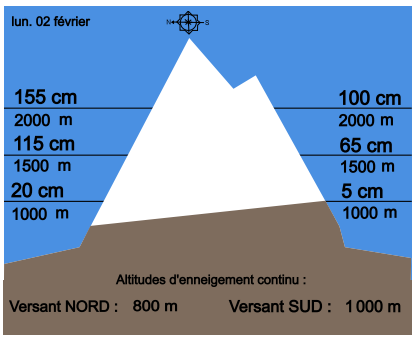

Précipitations à 1800 m

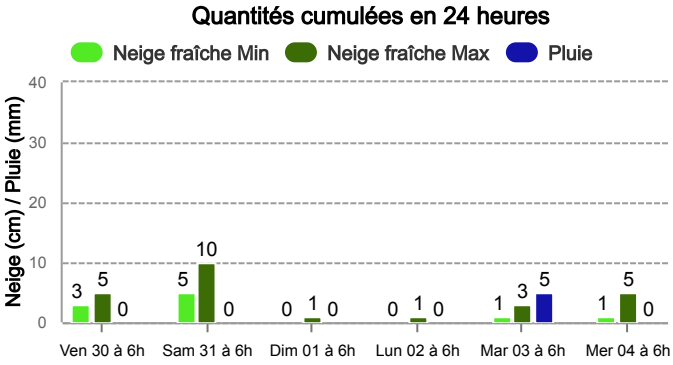

Tendance du mercredi 04 février

3 **Indice de risque marqué**

Plaques en place dans un large nord d'altitude ce mercredi. Vent de sud 40-60 km/h

Pour consulter la vigilance en cours, veuillez vous rendre sur le site https://vigilance.meteofrance.fr/fr

Météo-France - 73 avenue de Paris, 94165 Saint-Mandé cedex - Contact : contact@meteo.fr

Rédigé par Météo-France avec la contribution des observateurs du réseau nivo-météorologiques. Partenariat : ANMSM (Maires de Stations de Montagne), DSF (Domaines Skiables de France), ADSP (Directeurs de Pistes et de la Sécurité des Stations de Sports d'Hiver) et autres acteurs de la montagne.

Bulletin neige & avalanches par téléphone au **0 892 68 10 20** Service 0,35 € / min + prix appel

RÉPUBLIQUE FRANÇAISE
Liberté Égalité Fraternité

METEO FRANCE
À VOS CÔTÉS, DANS UN CLIMAT QUI CHANGE

Bulletin d'estimation du risque d'avalanche
(valable en dehors des pistes balisées et ouvertes)

MASSIF : Vercors

Rédigé le lundi 2 février 2026 à 16h

Conditions nivo-météo des 7 derniers jours

	mar. 27/01				mer. 28/01				jeu. 29/01				ven. 30/01				sam. 31/01				dim. 01/02				lun. 02/02			
	03h	09h	15h	21h	03h	09h	15h	21h	03h	09h	15h	21h	03h	09h	15h	21h	03h	09h	15h	21h	03h	09h	15h	21h	03h	09h	15h	21h
Météo																												
Vent (km/h)	70	90	100	90	20	30	40	45	45	25	15	30	45	35	25	20	20	15	20	20	20	20	20	20	25	55	80	120
à 2000m																												
Vent (km/h)	40	75	90	80	10	15	15	15	20	5	0	15	30	20	15	15	15	10	15	10	15	15	15	15	15	35	65	100
à 1500m																												

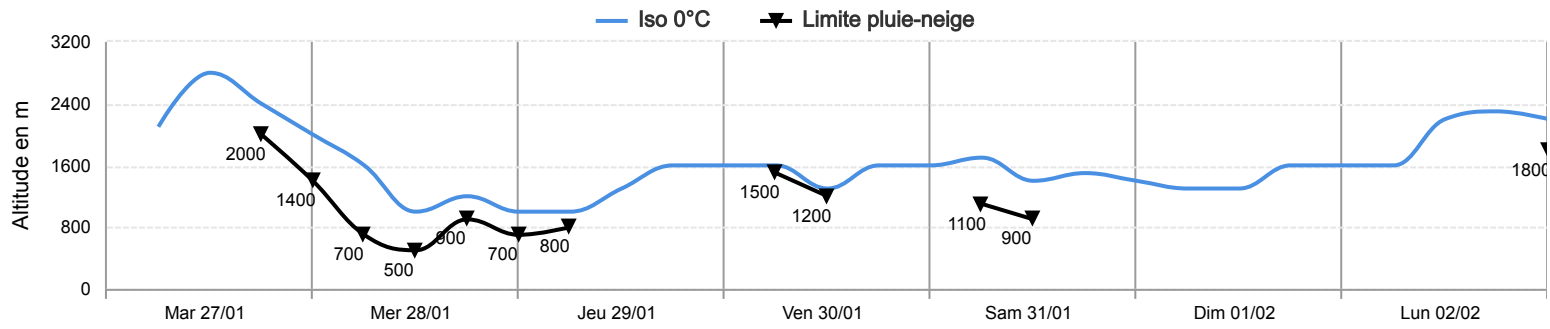

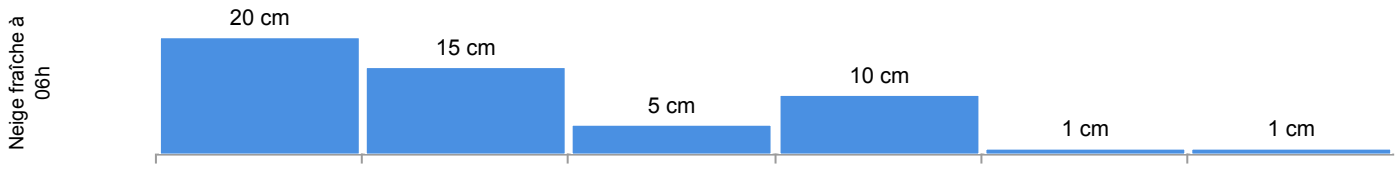

Risque d'avalanche	mar. 27/01	mer. 28/01	jeu. 29/01	ven. 30/01	sam. 31/01	dim. 01/02	lun. 02/02
	3	3	3	3	2	2	3

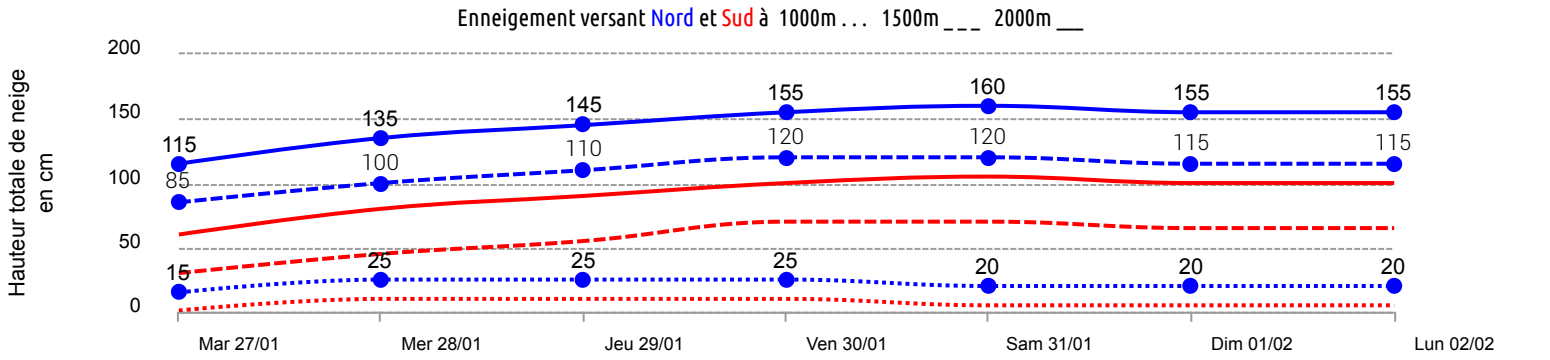

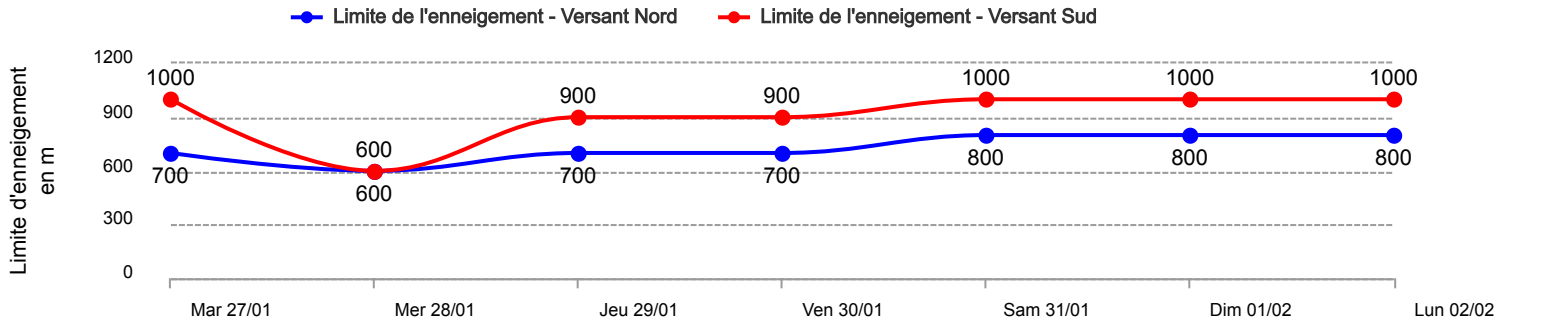

Pour consulter la vigilance en cours, veuillez vous rendre sur le site https://vigilance.meteofrance.fr/fr

Météo-France - 73 avenue de Paris, 94165 Saint-Mandé cedex - Contact : contact@meteo.fr

Rédigé par Météo-France avec la contribution des observateurs du réseau nivo-météorologiques. Partenariat : ANMSM (Maires de Stations de Montagne), DSF (Domaines Skiables de France), ADSP (Directeurs de Pistes et de la Sécurité des Stations de Sports d'Hiver) et autres acteurs de la montagne.

Bulletin neige & avalanches par téléphone au
0 892 68 10 20 Service 0,35 € / min + prix appel