GOBIERNO DE ESPAÑA
VICEPRESIDENCIA TERCERA DEL GOBIERNO
MINISTERIO PARA LA TRANSICIÓN ECOLÓGICA Y EL RETO DEMOGRÁFICO

Boletín de información nivológica y de peligro de aludes

Pirineo Catalán

aemet Agencia Estatal de Meteorología

martes, 3 de febrero de 2026

Pronóstico hasta las 24 horas del miércoles, día 4 de febrero

(Válido fuera de pistas de esquí balizadas y abiertas)

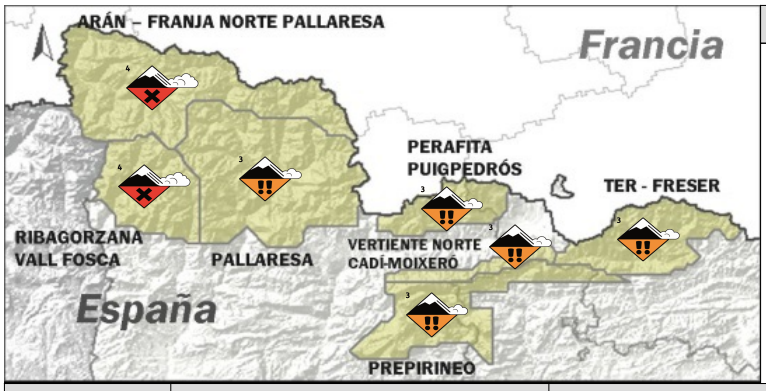

Problemas de aludes

Placas de viento

Macizo	Peligro	Problemas de aludes, cota, orientación, tamaño	Innivación observada (m)
Arán - Franja norte Pallaresa	4 Fuerte; 4 / 3 a 2100	Placas de viento; a 2100; N O E S; 3	2026-02-03; N S; Cotas bajas
Ribagorzana - Vall Fosca	4 Fuerte; 4 / 3 a 2100	Placas de viento; a 2100; N O E S; 3	2026-02-03; N S; Cotas bajas
Pallaresa	3 Notable; 3	Placas de viento; a 2100; N O E S; 2	2026-02-03; N S; Cotas bajas
Perafita - Puigpedrós	3 Notable; 3 / 2 a 2100	Placas de viento; a 2100; N O E S; 2	2026-02-03; N S; Cotas bajas
Ter - Freser	3 Notable; 3 / 2 a 2100	Placas de viento; a 2100; N O E S; 2	2026-02-03; N S; Cotas bajas
Vertiente norte Cadí - Moixeró	3 Notable; 3 / 2 a 2100	Placas de viento; a 2100; N O E S; 2	2026-02-03; N S; Cotas bajas

AEMET. Se autoriza la reproducción de su contenido citando la fuente.

Boletín de información nivológica y de peligro de aludes

Pirineo Catalán

Prepirineo	**Notable**	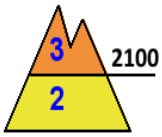	**Placas de viento**					2026-02-03 **Cotas bajas**

Estado del manto y observaciones recientes

A las 8 UTC del día de hoy se habían registrado abundantes precipitaciones, generalmente en torno a 5-15 l/m2, localmente más significativas en la Ribagorzana-Vall Fosca y la Pallaresa, donde se han podido superar los 20 l/m2. Estas han sido en todos los casos en forma de nieve por encima de los 2000 metros, con una cota que fue descendiendo a lo largo del día de ayer, alcanzando los 1000-1100 metros esta madrugada. Así, se han podido añadir en torno a 10-20 cm de nieve nueva por encima de los 2000-2100 metros, aunque los fuertes vientos de componentes oeste y sur que han acompañado las nevadas han venteado y distribuido de manera muy desigual la nieve recién caída. Así mismo, el descenso de las temperaturas y las cotas de nieve han dado lugar a una estabilización del manto, muy humidificado, de cotas medias y bajas. Durante el día de hoy se espera que las precipitaciones continúen, aunque de manera más bien débil, en forma de nieve desde cotas bajas.

La cubierta de nieve comienza en cotas bajas y los espesores de gran parte de la red de observación están en máximos para la época. Estos se sitúan en torno a 120-150 cm por encima de 2100 metros, valores que pueden ser muy superiores conforme ganamos altitud, así como en ventisqueros u otras áreas de acumulación.

En cotas altas, la nieve presenta muy grandes acumulaciones, manteniéndose seca y muy venteada en superficie, al tiempo que, en umbrías, se observan estratos débiles internos así como una antigua capa débil persistente en la base del manto. En cotas inferiores, la nieve está más humedecida y estable, presentando generalmente una costra de rehielo, debido al reciente descenso de las temperaturas.

En las últimas 24 horas no se han reportado avalanchas significativas, tan solo algunas purgas pequeñas de nieve reciente.

Evolución del manto y peligro de aludes para el miércoles, día 4

Problemas de placas de viento y capas débiles persistentes en cotas altas. Problema de nieve húmeda y deslizamientos basales en cotas bajas, al final del día. Situación de nieve reciente.

A lo largo de los días de hoy y mañana se espera que las nevadas continúen desde cotas bajas, aunque de manera poco significativa, pudiendo acumular tan solo algunos centímetros nuevos de nieve reciente, que localmente podrían alcanzar los 5 cm en la Ribagorzana-Vall Fosca. En este contexto, no se descarta alguna colada o purga de nieve reciente pequeña en zonas con suficiente inclinación. Tampoco se descarta que todavía puedan suceder aludes de mayor tamaño, generalmente 1 (pequeño) ó 2 (mediano), debido a la nieve reciente que se acumuló durante la jornada de ayer.

AEMET. Se autoriza la reproducción de su contenido citando la fuente.

El mayor peligro tendrá lugar en cotas altas, donde continuarán los fuertes vientos de componentes oeste y sur, que siguen venteando la nieve recién caída y favoreciendo la formación de placas de viento en todas las orientaciones, aunque con preferencia en las vertientes norte y este. Estas nuevas estructuras se añadirán a otras ya existentes de formación antigua, todavía activas. También pueden aparecer en cotas medias, aunque con tamaños más bien pequeños. Todas estas placas se mantendrán inestables, y bastará el paso de un solo esquiador para colapsarlas. En las umbrías, no se descarta que las capas débiles persistentes antiguas sigan activas, siendo susceptibles de colapsar en zonas de manto delgado. Ambos tipos de problemas podrán dar lugar a aludes de tamaño 2 ó 3 (grande, capaz de destruir un vehículo), incluso en zonas ya transitadas.

En cotas bajas y medias, las temperaturas frías y las recientes nevadas han contribuido a la estabilización de un manto humidificado, con la consecuente formación de costras de rehielo. Sin embargo, durante la segunda mitad del día de mañana, se espera un ascenso de las isoceros (a unos 2000-2200 metros) y de las cotas de nieve (pudiendo dejar algunas precipitaciones en forma de lluvia en cotas bajas), de manera que el manto de estas cotas volverá a desestabilizarse de manera progresiva, desapareciendo las costras y reapareciendo el problema de nieve húmeda al final del día. Este tipo de aludes podrán ser generalmente de tamaño 1 (pequeño) ó 2 (mediano). También serán posibles los deslizamientos basales en aquellas zonas herbosas de manto delgado donde las lluvias de jornadas anteriores hayan sido más copiosas.

Predicción meteorológica para el miércoles, día 4

Predominio de cielos muy nubosos o cubiertos, aunque con posible apertura de grandes claros. Periodos de visibilidad localmente reducida. Precipitaciones débiles y ocasionales en los macizos occidentales. Cota de nieve en torno a unos 800-1000 metros durante la primera mitad del día y en ascenso durante la segunda mitad, alcanzando los 1400-1600 metros aproximadamente. Temperaturas mínimas en ligero descenso. Ligeros ascensos en las máximas del norte y sin cambios en el resto. Heladas débiles o moderadas, localmente fuertes y persistentes en la alta montaña. Viento flojo o moderado de componentes sur y oeste. Más intenso en cotas altas y zonas expuestas, donde soplará moderado o fuerte con rachas muy fuertes.

Datos en la atmósfera libre:

Altitud de la isoterma de 0 ºC: 1500 m
Altitud de la isoterma de -10 ºC: 3500 m

Viento a 1500 m: SW 20 km/h
Viento a 3000 m: NW 40 km/h

Evolución para el jueves día 5

Nivel de peligro con pocos cambios.

Escala europea de peligro de aludes

Débil | Limitado | Notable | Fuerte | Muy Fuerte

Problemas de aludes

Nieve reciente | Placas de viento | Capas débiles persistentes | Nieve húmeda | Deslizamientos basales | Sin problema evidente

AEMET. Se autoriza la reproducción de su contenido citando la fuente.

Nota1: Se recuerda que, siempre que haya nieve, la ausencia total de peligro no existe. Hay que tener presente que en circunstancias desfavorables, con aludes de tamaño 1 (alud pequeño o colada) y tamaño 2 (alud mediano), se pueden sufrir severos daños personales.

Nota2: Los BPA se elaboran en base a información meteorológica así como al estado del manto nivoso a través de sondeos puntuales. Se advierte a los usuarios de la variabilidad de esta información al extrapolarla a zonas extensas de montaña. Por ello, AEMET no se hace responsable de su uso para la toma de decisiones que conciernen a la seguridad personal, ni de los riesgos físicos o materiales de ellas derivadas.

AEMET. Se autoriza la reproducción de su contenido citando la fuente.