GOBIERNO DE ESPAÑA
VICEPRESIDENCIA TERCERA DEL GOBIERNO
MINISTERIO PARA LA TRANSICIÓN ECOLÓGICA Y EL RETO DEMOGRÁFICO

Boletín de información nivológica y de peligro de aludes

Pirineo Navarro y Aragonés

aemet Agencia Estatal de Meteorología

martes, 3 de febrero de 2026

Pronóstico hasta las 24 horas del miércoles, día 4 de febrero

(Válido fuera de pistas de esquí balizadas y abiertas)

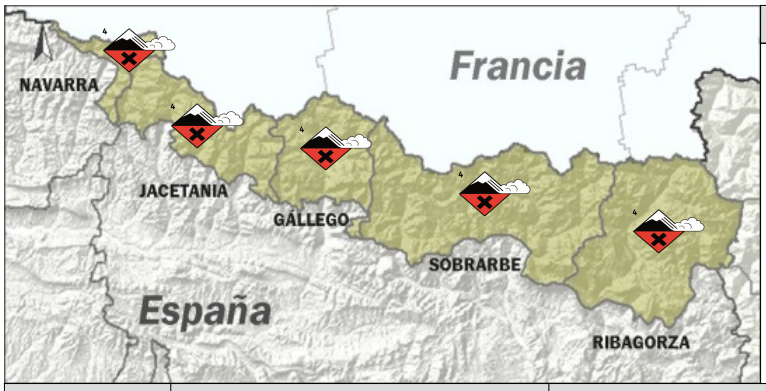

Problemas de aludes

Placas de viento

Nieve reciente

Macizo	Peligro	Problemas de aludes, cota, orientación, tamaño	Innivación observada (m)
Navarra	4 4 / 3 2100 Fuerte	Placas de viento 2100 N O E S 3	2026-02-03 N S Cotas bajas
		Nieve reciente N O E S 2	
Jacetania	4 4 / 3 2100 Fuerte	Placas de viento 2100 N O E S 3	2026-02-03 N S Cotas bajas
		Nieve reciente N O E S 2	
Gállego	4 4 / 3 2100 Fuerte	Placas de viento 2100 N O E S 3	2026-02-03 N S Cotas bajas
		Nieve reciente N O E S 2	

AEMET. Se autoriza la reproducción de su contenido citando la fuente.

Sobrarbe	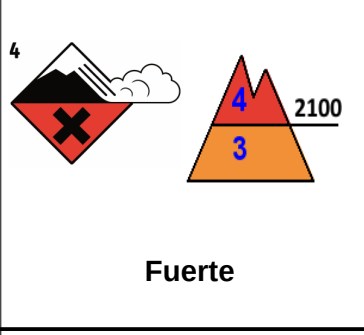 **Fuerte**	**Placas de viento** 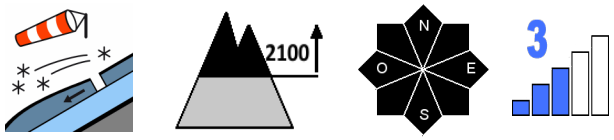 **Nieve reciente** 	2026-02-03 Cotas bajas
Ribagorza	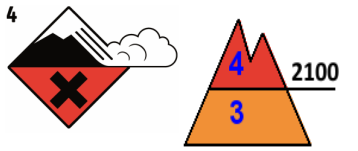 **Fuerte**	**Placas de viento** **Nieve reciente** 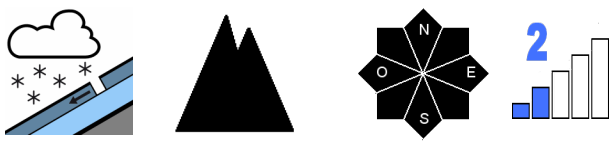	2026-02-03 Cotas bajas

Estado del manto y observaciones recientes

A las 8 UTC del día de hoy se habían registrado abundantes precipitaciones, generalmente en torno a 10-20 l/m2, aunque localmente han sido más significativas, alcanzando 30-40 l/m2 en algunos enclaves. Estas han sido en todos los casos en forma de nieve por encima de los 2000 metros, con una cota que fue descendiendo a lo largo del día de ayer, alcanzando los 1000-1100 metros esta madrugada. Así, se han podido añadir en torno a 20-30 cm de nieve nueva por encima de los 2000-2100 metros, aunque los fuertes vientos de componentes oeste y sur que han acompañado las nevadas han venteado y distribuido de manera muy desigual la nieve recién caída. Así mismo, el descenso de las temperaturas y las cotas de nieve han dado lugar a una estabilización del manto, muy humidificado, de cotas medias y bajas. Durante el día de hoy se espera que las precipitaciones continúen, aunque débilmente, en forma de nieve desde cotas bajas.

El manto comienza en cotas bajas, con espesores muy variables a causa del efecto del viento, pero que superan los 120-140 cm en torno a 1800 metros y los 170-220 cm por encima de 2100, notablemente más en ventisqueros y otras zonas de acumulación. Los espesores superan el percentil 80 de la serie histórica en la mayor parte de la red de observación.

En cotas altas, la nieve presenta muy grandes acumulaciones, manteniéndose seca y muy venteada en superficie, formando estructuras de placa que rompen y se propagan con facilidad ante esfuerzos pequeños, mientras que, internamente y principalmente en umbrías, se observan niveles débiles de facetas, además de las antiguas capas débiles persistentes que siguen mostrando reactividad, como así confirman algunos de los últimos sondeos y aludes. Cabe destacar que se han observado numerosas cornisas en crestas que pueden romper, desencadenando así avalanchas.

AEMET. Se autoriza la reproducción de su contenido citando la fuente.

En cotas inferiores la nieve se encuentra muy humedecida debido a las recientes lluvias, que han resultado muy copiosas, presentando generalmente una costra de rehielo, debido al reciente descenso de las temperaturas.

En las últimas 24 horas no se han reportado nuevos aludes, tan solo algunas purgas superficiales de nieve reciente en zonas empinadas.

Evolución del manto y peligro de aludes para el miércoles, día 4

Problemas de placas de viento y capas débiles persistentes en cotas altas. Problema de nieve reciente. Problema de nieve húmeda y deslizamientos basales en cotas bajas.

A lo largo de los días de hoy y mañana se espera que las nevadas continúen, débilmente durante el día de hoy y de manera más copiosa durante el día de mañana. Con todo esto, se espera que al final del día de mañana se hayan acumulado unos 10-20 cm de nieve nueva desde cotas bajas, sin descartar que localmente se puedan alcanzar los 30 cm, añadiéndose a los caídos en jornadas anteriores. Estos nuevos espesores se prevén en todos los macizos salvo en la Ribagorza, donde no se espera que se superen los 5-10 cm. En este contexto, son probables las purgas espontáneas de nieve reciente, de tamaño 1 (pequeño, capaz de desestabilizar a una persona) ó 2 (mediano, capaz de enterrar a una persona), en zonas con suficiente inclinación.

El mayor peligro tendrá lugar en cotas altas, donde continuarán los fuertes vientos de componentes oeste y sur, que siguen venteando la nieve recién caída y favoreciendo la formación de placas de viento en todas las orientaciones, aunque con preferencia en las vertientes norte y este. Estas nuevas estructuras se añadirán a otras ya existentes de formación antigua, todavía activas. También pueden aparecer en cotas medias, aunque con tamaños más bien pequeños. Todas estas placas se mantendrán inestables, y bastará el paso de un solo esquiador para colapsarlas. En las umbrías, las capas débiles persistentes antiguas siguen dando muestras de reactividad, siendo susceptibles de colapsar en zonas de manto delgado. Ambos tipos de problemas podrán dar lugar a aludes de tamaño 2 ó 3 (grande, capaz de destruir un vehículo), incluso en zonas ya transitadas, y no se descarta que localmente alcancen el tamaño 4 (muy grande, capaz de destruir un camión o vagón de tren). Por último, cabe recordar la proliferación de cornisas y la posibilidad de desencadenamiento de aludes bajo estas en caso de ruptura.

En cotas bajas y medias, las temperaturas frías y las recientes nevadas han contribuido a la estabilización de un manto muy humidificado, con la consecuente formación de costras de rehielo. Sin embargo, durante la segunda mitad del día de mañana, se espera un ascenso de las isoceros (a unos 2000-2200 metros) y de las cotas de nieve (dejando precipitaciones en forma de lluvia en cotas bajas), de manera que el manto de estas cotas volverá a desestabilizarse de manera progresiva, desapareciendo las costras y reapareciendo el problema de nieve húmeda. Este tipo de aludes podrán ser generalmente de tamaño 1 (pequeño) ó 2 (mediano), sin descartar alguno 3 (grande), en el caso de que el agua haya podido percolar a niveles inferiores. También serán posibles los deslizamientos basales en aquellas zonas de manto delgado donde las lluvias hayan sido muy copiosas, con preferencia en cotas bajas y zonas herbosas.

AEMET. Se autoriza la reproducción de su contenido citando la fuente.

Predicción meteorológica para el miércoles, día 4

Pirineo navarro:
Predominio de cielos muy nubosos o cubiertos. Periodos de visibilidad localmente reducida. Precipitaciones débiles o moderadas. Cota de nieve en torno a unos 900-1000 metros durante la primera mitad del día y en ascenso durante la segunda mitad, alcanzando los 1500-1700 metros. Algunos ligeros ascensos en las temperaturas. Heladas débiles, moderadas en cotas altas. Viento moderado o fuerte de componentes sur y oeste, con rachas muy fuertes en cotas altas y zonas expuestas.

Pirineo aragonés:
Predominio de cielos muy nubosos o cubiertos, aunque con posible apertura de algunos claros ocasionales. Periodos de visibilidad localmente reducida. Precipitaciones débiles o moderadas, sin descartar que puedan ser localmente persistentes en el área occidental. Cota de nieve en torno a unos 900-1100 metros durante la primera mitad del día y en ascenso durante la segunda mitad, alcanzando los 1500-1700 metros. Temperaturas mínimas con pocos cambios. Máximas en ligero o moderado ascenso. Heladas débiles o moderadas, localmente fuertes y persistentes en la alta montaña. Viento flojo o moderado de componentes sur y oeste. Más intenso en cotas altas y zonas expuestas, donde soplará generalmente fuerte con rachas muy fuertes.

Datos en la atmósfera libre:

Altitud de la isoterma de 0 ºC: 1300 m
Altitud de la isoterma de -10 ºC: 3500 m

Viento a 1500 m: SW 20 km/h
Viento a 3000 m: NW 65 km/h

Evolución para el jueves día 5

Nivel de peligro con pocos cambios.

(Información elaborada a partir de los datos recibidos de los refugios de Linza, Lizara, Panticosa, Bachimaña, Góriz, Pineta, Estós, Angel Orús, La Renclusa, Cap de Llauset y Belagua, de las estaciones de esquí de Formigal y Panticosa (lagos), de la estación de esquí de fondo de Llanos del Hospital y de Ordesa Pradera)

Escala europea de peligro de aludes

Débil | Limitado | Notable | Fuerte | Muy Fuerte

Problemas de aludes

Nieve reciente | Placas de viento | Capas débiles persistentes | Nieve húmeda | Deslizamientos basales | Sin problema evidente

Nota1: Se recuerda que, siempre que haya nieve, la ausencia total de peligro no existe. Hay que tener presente que en circunstancias desfavorables, con aludes de tamaño 1 (alud pequeño o colada) y tamaño 2 (alud mediano), se pueden sufrir severos daños personales.

Nota2: Los BPA se elaboran en base a información meteorológica así como al estado del manto nivoso a través de sondeos puntuales. Se advierte a los usuarios de la variabilidad de esta información al extrapolarla a zonas extensas de montaña. Por ello, AEMET no se hace responsable de su uso para la toma de decisiones que conciernen a la seguridad personal, ni de los riesgos físicos o materiales de ellas derivadas.

AEMET. Se autoriza la reproducción de su contenido citando la fuente.