Mittwoch 04.02.2026

Veröffentlicht am 03.02.2026 um 17:00

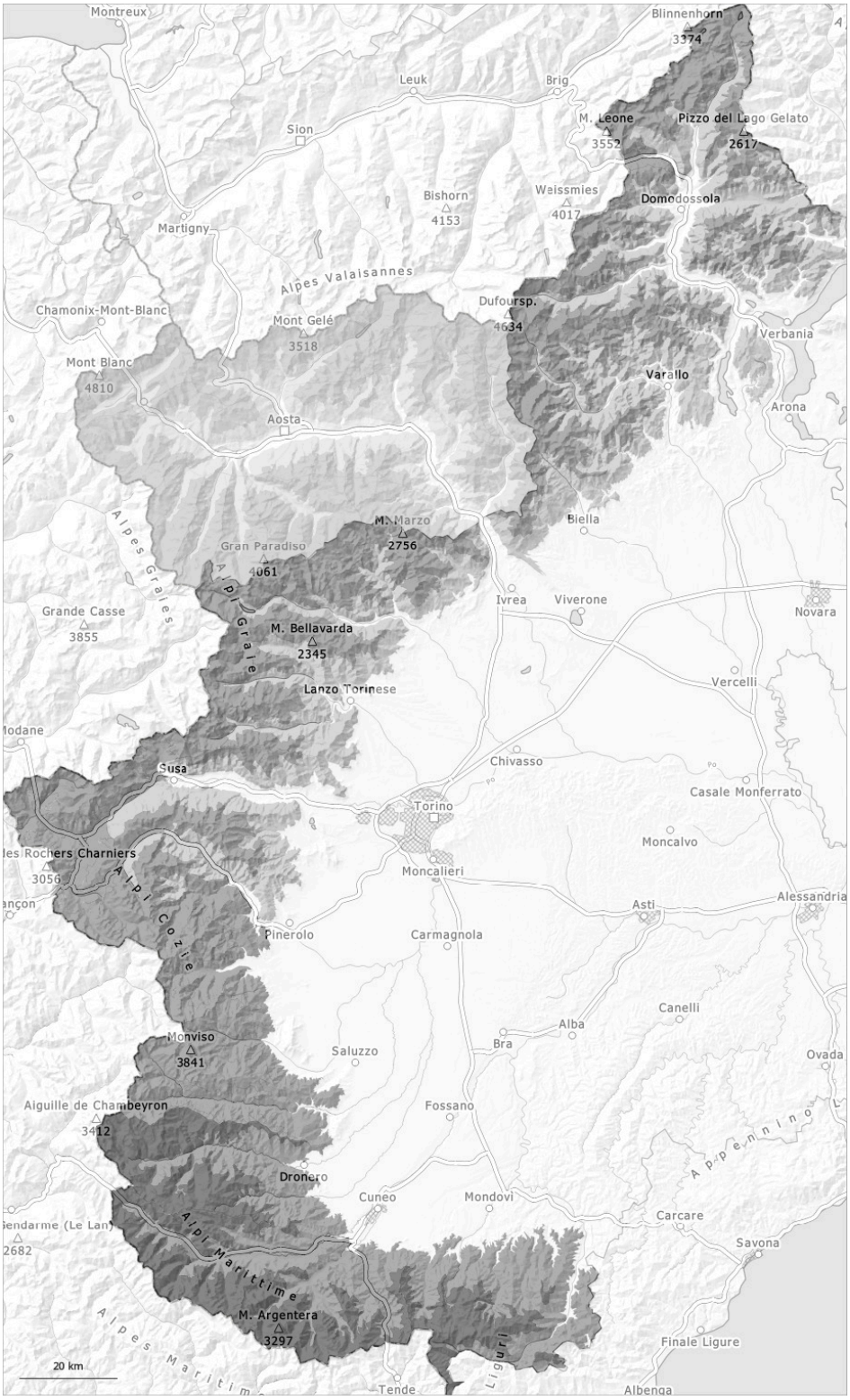

1	2	3	4	5
gering	mäßig	erheblich	groß	sehr groß

Gefahrenstufe 4 - Groß

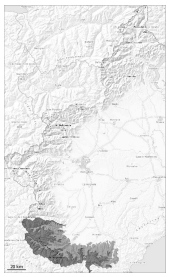

Waldgrenze

Tendenz: Lawinengefahr nimmt ab
am Donnerstag, den 05.02.2026

Triebschnee

Waldgrenze

Neuschnee

In mittleren und hohen Lagen verbreitet kritische Lawinensituation. Neu- und Triebschnee sind die Hauptgefahr.

Mit Neuschnee und starkem Südwestwind entstanden störanfällige Triebschneeansammlungen. Sie können leicht ausgelöst werden und sehr groß werden. Dies vor allem an steilen Hängen oberhalb der Waldgrenze sowie in Rinnen, Mulden und hinter Geländekanten. Lawinen können oft in den verschiedenen Triebschneeschichten ausgelöst werden.
Die Gefahrenstellen sind bei der schlechten Sicht kaum zu erkennen.
Wummgeräusche und Risse beim Betreten der Schneedecke sowie spontane Lawinenabgänge sind deutliche Zeichen eines schwachen Schneedeckenaufbaus.
Von Touren abseits gesicherter Pisten wird abgeraten.

Schneedecke

Gefahrenmuster gm.6: lockerer schnee und wind

Gestern fielen verbreitet 30 bis 40 cm Schnee, lokal auch mehr. Mit starkem Südwestwind entstanden frische Triebschneeansammlungen.
Neu- und Triebschnee liegen verbreitet auf einer schwachen Altschneedecke.

Gefahrenstufe 3 - Erheblich

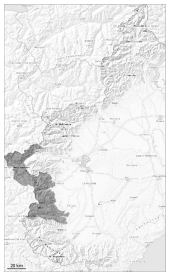

Tendenz: Lawinengefahr bleibt gleich
am Donnerstag, den 05.02.2026

Triebschnee

Erhebliche Lawinengefahr. Neu- und Triebschnee bilden die Hauptgefahr.

Mit Neuschnee und mäßigem Wind entstanden teils große Triebschneeansammlungen.
Triebschneeansammlungen können schon von einzelnen Wintersportlern ausgelöst werden. Dies vor allem an steilen Hängen sowie in Rinnen, Mulden und hinter Geländekanten auch in mittleren Lagen.
Die Gefahrenstellen sind bei der schlechten Sicht kaum zu erkennen. Wummgeräusche und Risse beim Betreten der Schneedecke sowie spontane Lawinenabgänge sind deutliche Zeichen eines schwachen Schneedeckenaufbaus.
Lawinen können v.a. an steilen Schattenhängen in tieferen Schichten ausgelöst werden.
Eine vorsichtige Routenwahl und Entlastungsabstände werden empfohlen.

Schneedecke

Gefahrenmuster gm.6: lockerer schnee und wind | gm.1: bodennahe schwachschicht

Gestern fielen verbreitet 15 bis 20 cm Schnee, lokal auch mehr. Mit Neuschnee und mäßigem bis starkem Wind aus südlichen Richtungen entstanden vor allem oberhalb der Waldgrenze heikle Triebschneeansammlungen. Neu- und Triebschnee liegen vor allem an windgeschützten Schattenhängen auf weichen Schichten.

Mittlere und hohe Lagen: Im unteren Teil der Schneedecke sind vor allem an sehr steilen Schattenhängen vereinzelt störanfällige Schwachschichten vorhanden.

Gefahrenstufe 3 - Erheblich

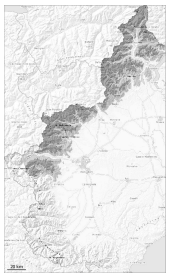

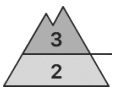

Waldgrenze

Tendenz: Lawinengefahr bleibt gleich
am Donnerstag, den 05.02.2026

Triebschnee

Waldgrenze

Neuschnee

In mittleren und hohen Lagen erhebliche Lawinengefahr.

Mit Neuschnee und Wind aus südlichen Richtungen entstanden störanfällige Triebschneeansammlungen. Dies vor allem an steilen Hängen sowie in Rinnen, Mulden und hinter Geländekanten auch in mittleren Lagen. Die frischen Triebschneeansammlungen können mit geringer Belastung ausgelöst werden.
Die Gefahrenstellen sind bei der schlechten Sicht kaum zu erkennen.
Lawinen können v.a. an steilen Schattenhängen in tieferen Schichten ausgelöst werden.
Entlastungsabstände und Einzelabfahrten werden empfohlen.

Schneedecke

Gefahrenmuster gm.6: lockerer schnee und wind | gm.1: bodennahe schwachschicht

Gestern fielen bis zu 10 cm Schnee. Mit Neuschnee und mäßigem Wind entstanden am Dienstag weitere Triebschneeansammlungen. Neu- und Triebschnee liegen vor allem an windgeschützten Schattenhängen auf weichen Schichten.

Mittlere und hohe Lagen: Im unteren Teil der Schneedecke sind vor allem an sehr steilen Schattenhängen vereinzelt störanfällige Schwachschichten vorhanden.