Mittwoch 04.02.2026

Veröffentlicht am 03.02.2026 um 17:00

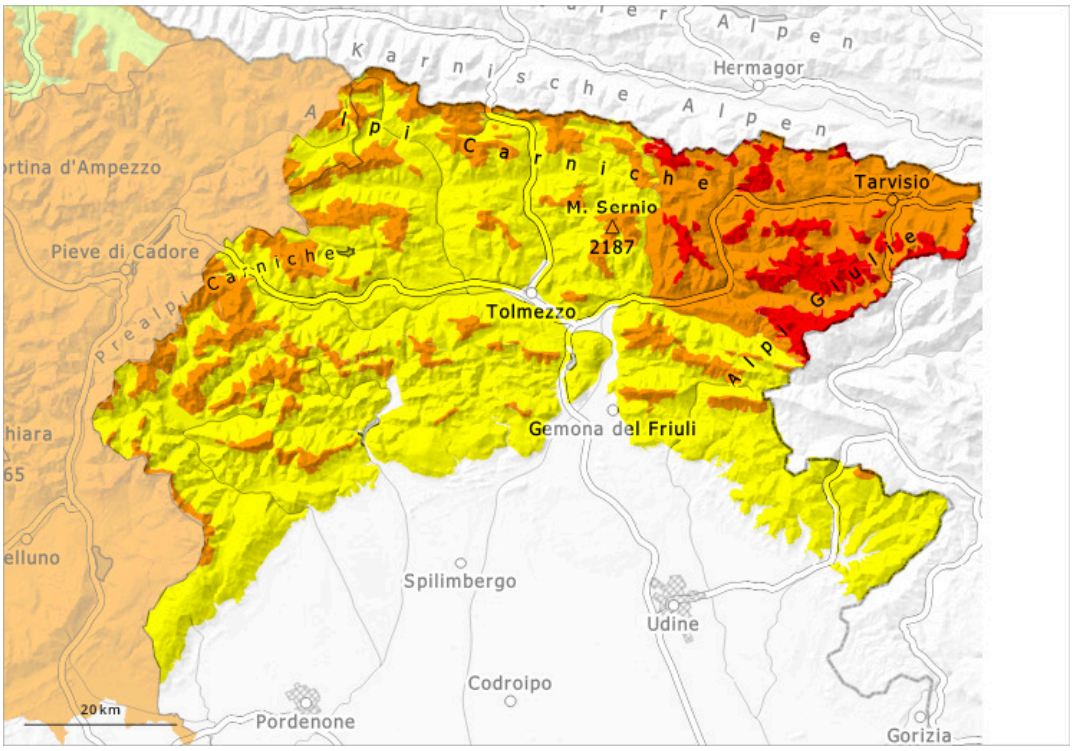

1	2	3	4	5
gering	mäßig	erheblich	groß	sehr groß

Gefahrenstufe 4 - Groß

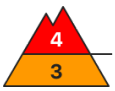

Waldgrenze

Tendenz: Lawinengefahr bleibt gleich
am Donnerstag, den 05.02.2026

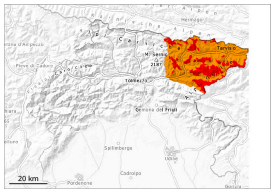

Neuschnee

Waldgrenze

Triebschnee

Waldgrenze

Altschnee

Waldgrenze

Neuschnee

Waldgrenze

In diesen Gebieten ist die Lawinengefahr "groß" (Stufe 4).

Ergiebiger Schneefall. Der Wind bläst mäßig bis stark.
Die Schneedecke bleibt meist instabil. Verbreitet sind spontane Lawinen möglich. Lawinen können in tiefe Schichten durchreißen sehr groß werden.
Von Touren wird dringend abgeraten.

Schneedecke

Schon etwas ältere Triebschneeansammlungen bleiben bis auf weiteres störanfällig. Mit Neuschnee und Wind entstehen weitere Triebschneeansammlungen.
In der Altschneedecke sind vor allem an Schattenhängen viele Schwachschichten vorhanden.

Tendenz

Leichter Schneefall.

Gefahrenstufe 3 - Erheblich

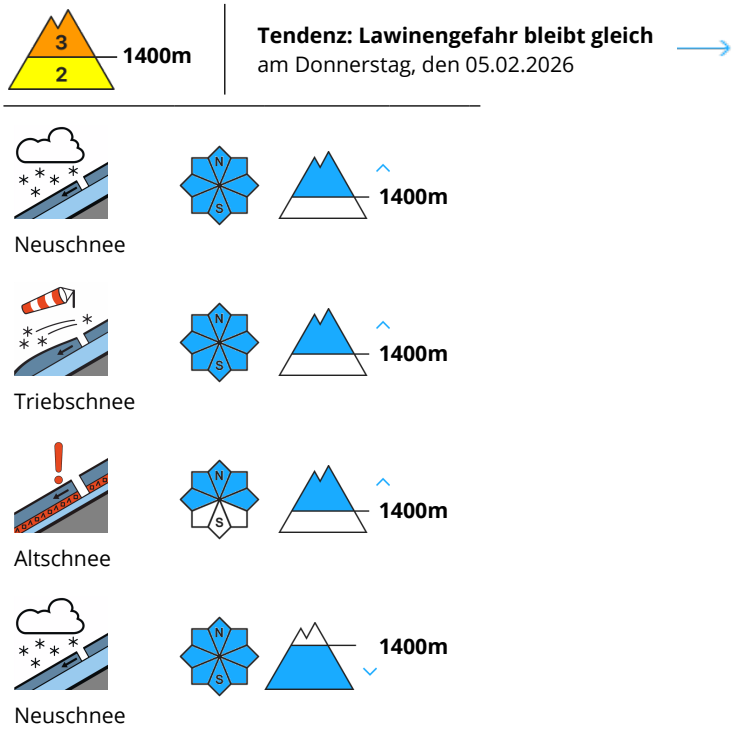

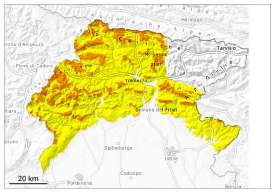

Erhebliche Lawinengefahr.
Mit Neuschnee und Wind nimmt die Anzahl der Gefahrenstellen im Tagesverlauf zu.

Die Gefahrenstellen liegen vor allem an Felswandfüßen sowie in Kammlagen, Rinnen und Mulden. Die Lawinen können in tiefen Schichten anreißen. Sie können an vielen Stellen schon von einzelnen Wintersportlern ausgelöst werden. Risse beim Betreten der Schneedecke sowie Wummgeräusche können auf die Gefahr hinweisen. Große Vorsicht und Zurückhaltung sind nötig.

Schneedecke

Die Schneedecke bleibt verbreitet instabil. Mit Neuschnee und Wind entstehen weitere Triebschneeansammlungen.
In der Altschneedecke sind vor allem an Schattenhängen viele Schwachschichten vorhanden.

Tendenz

Leichter Schneefall.