ICGC Institut Cartogràfic i Geològic de Catalunya

Servei Meteorològic de Catalunya meteo.cat

Boletín de peligro de aludes para el Pirineo de Catalunya
Del 03/02/2026 al 04/02/2026

(Válido fuera pistas de esquí y zonas no controladas)

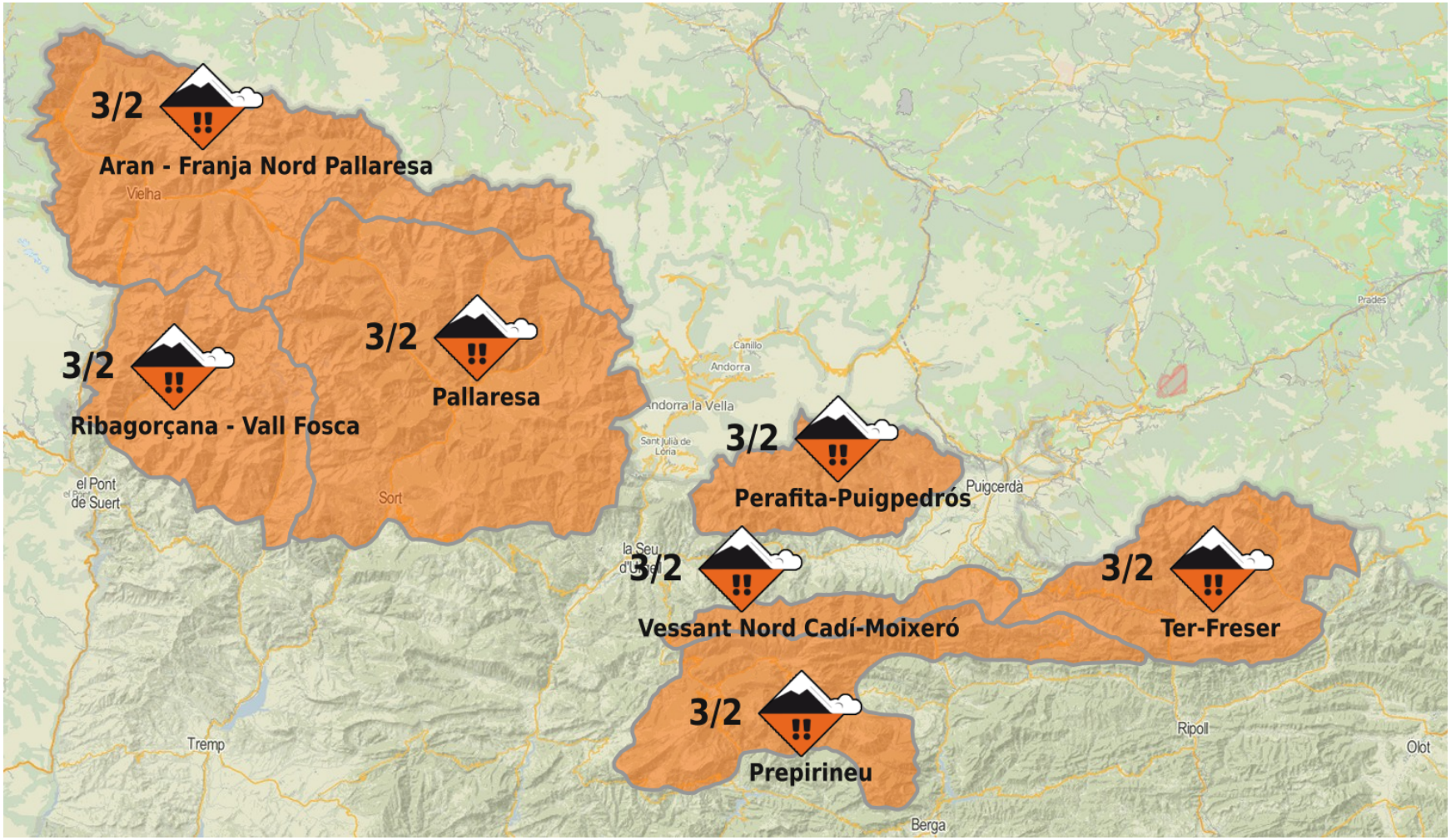

5 MUY FUERTE	4 FUERTE	3 NOTABLE	2 LIMITADO	1 DÉBIL

ICGC Institut Cartogràfic i Geològic de Catalunya

Servei Meteorològic de Catalunya

Boletín de peligro de aludes Aran - Franja Nord Pallaresa Del 03/02/2026 al 04/02/2026

(Válido fuera pistas de esquí y zonas no controladas)

Notable (3) por encima de 2.000 m Limitado (2) por debajo

Situación primaria

Nieve venteada

Distribución

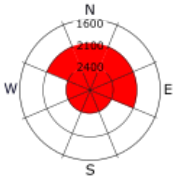

Tamaño

Origen

Tendencia

Situación secundaria

Deslizamientos basales

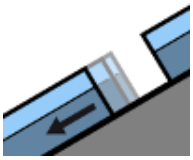

Distribución

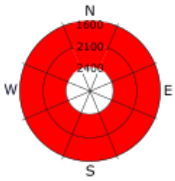

Tamaño

Origen

Tendencia

Estado del manto nivoso

La nevada que se inició con lluvia ha dejado una base de costra no portante sobre la que hay nieve reciente en la Franja Norte de la Pallaresa y placas de viento blanda en el Aran, donde el viento ha trabajado. Las placas recientemente formadas, ya sean de viento o nieve reciente son frágiles y también las hay antiguas, igualmente frágiles. Pueden caer al solo paso de una persona en orientaciones NW, N, NE y E, por encima de los 2000 m. Serán por lo general de tamaño 2, mediano (pueden enterrar a una persona) y puntualmente de hasta tamaño 3, grande, (capacidad para cubrir un grupo de personas). Perdura el problema de deslizamientos basales, por lo general de tamaño 2. En la Franja norte de la Pallaresa pueden caer aludes de nieve reciente especialmente de tamaño 2, en vertientes de fuerte inclinación.

Distribución del manto nivoso

Hay nieve en el suelo a 1.000 m. El manto es esquiable por encima de unos 1.500 m. Los espesores a unos 2.200 m rondan los 100-135 cm en el norte de Arán y 130-180 cm en la Franja Norte Pallaresa y en el sur de Aran, y son superiores a los normales por estas fechas.

Tendencia para las próximas 48-72h

A partir del jueves el manto puede humedecerse hasta los 2000 m por el ascenso térmico y las precipitaciones previstas. Peligro ESTACIONARIO

El próximo boletín será emitido el día 2026-02-04

5 MUY FUERTE	4 FUERTE	3 NOTABLE	2 LIMITADO	1 DÉBIL

EAWS EUROPEAN AVALANCHE WARNING SERVICES

ICGC Institut Cartogràfic i Geològic de Catalunya

meteo.cat Servei Meteorològic de Catalunya

Boletín de peligro de aludes Ribagorçana - Vall Fosca Del 03/02/2026 al 04/02/2026

(Válido fuera pistas de esquí y zonas no controladas)

Notable (3) por encima de 2.200 m. Limitado (2) por debajo.

Situación primaria

Nieve venteada

Distribución

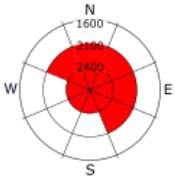

Tamaño

Origen

Tendencia

Estado del manto nivoso

La nieve humedecida por lluvia del lunes se ha encostrado superficialmente. Encima se han formado placas de viento blandas por la nevada que se dio después con el descenso de la cota de nieve. Estas placas son blandas y se prevé que con el transcurso de las horas, se vaya debilitando su contacto con la nieve subyacente. Pueden presentarse frágiles por encima de los 2200 m. Pueden caer al solo paso de una persona con facilidad, especialmente en orientaciones NW, N, NE y E, por lo general serán de tamaño 2, mediano, suficiente para cubrir una persona. Localmente, pueden ser algo mayores hasta alcanzar tamaño para enterrar a un grupo de personas. Por debajo de los 2200 m, encontramos un manto más encostrado en superficie formado por costras no portantes. En lugares muy resguardados, como dentro de canales y zonas deprimidas, hay nieve reciente que puede caer de forma natural en forma de purgas o pequeños aludes, sobre todo en los lugares más inclinados.

Distribución del manto nivoso

Hay nieve en el suelo a 1.500 m. El manto es esquiable por encima de unos 1500-1600 m. Los grosores alcanzan los 120-150 cm. Estos valores son muy superiores a los normales en la época.

Tendencia para las próximas 48-72h

A partir del jueves el manto puede humedecerse hasta los 2000 m por el ascenso térmico y las precipitaciones previstas. Peligro ESTACIONARIO

El próximo boletín será emitido el día 2026-02-04

5 MUY FUERTE	4 FUERTE	3 NOTABLE	2 LIMITADO	1 DÉBIL

EAWS EUROPEAN AVALANCHE WARNING SERVICES

ICGC Institut Cartogràfic i Geològic de Catalunya

meteo.cat Servei Meteorològic de Catalunya

Boletín de peligro de aludes Pallaresa
Del 03/02/2026 al 04/02/2026

(Válido fuera pistas de esquí y zonas no controladas)

Notable (3) por encima de 2.200 m. Limitado (2) por debajo.

Situación primaria

Nieve venteada

Distribución

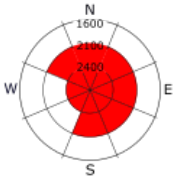

Tamaño

Origen

Tendencia

Estado del manto nivoso

La nieve humedecida por lluvia del lunes se ha encostrado superficialmente. Encima se han formado placas de viento blandas por la nevada que se dio después con el descenso de la cota de nieve. Estas placas son blandas y se prevé que con el transcurso de las horas, se vaya debilitando su contacto con la nieve subyacente. Pueden presentarse frágiles por encima de los 2200 m. Pueden caer al solo paso de una persona con facilidad, especialmente en orientaciones NW, N, NE y E, por lo general serán de tamaño 2, mediano, suficiente para cubrir una persona. Localmente, pueden ser algo mayores hasta alcanzar tamaño para enterrar a un grupo de personas. Por debajo de los 2200 m, encontramos un manto más encostrado en superficie formado por costras no portantes. En lugares muy resguardados, como dentro de canales y zonas deprimidas, hay nieve reciente que puede caer de forma natural en forma de purgas o pequeños aludes, sobre todo en los lugares más inclinados.

Distribución del manto nivoso

Hay nieve desde 1500 m, esquiable a 1500-1600 m. Los espesores en cotas altas y medias superan los 140 cm. Estos valores son superiores a los normales para la época.

Tendencia para las próximas 48-72h

A partir del jueves el manto puede humedecerse hasta los 2000 m por el ascenso térmico y las precipitaciones previstas. Peligro ESTACIONARIO

El próximo boletín será emitido el día 2026-02-04

5 MUY FUERTE	4 FUERTE	3 NOTABLE	2 LIMITADO	1 DÉBIL

EAWS EUROPEAN AVALANCHE WARNING SERVICES

ICGC Institut Cartogràfic i Geològic de Catalunya

Servei Meteorològic de Catalunya meteo.cat

Boletín de peligro de aludes Perafita-Puigpedrós Del 03/02/2026 al 04/02/2026

(Válido fuera pistas de esquí y zonas no controladas)

Notable (3) por encima de 2.400 m. Limitado (2) por debajo.

Situación primaria

Nieve venteada

Distribución

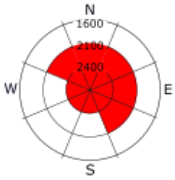

Tamaño

Origen

Tendencia

Estado del manto nivoso

La nieve humedecida por lluvia del lunes se ha encostrado. Encima se han formado placas de viento blandas por la nevada que se dio después con el descenso de la cota de nieve. Estas placas son blandas y se prevé que con el transcurso de las horas, se vaya debilitando su contacto con la nieve subyacente. Se pueden presentar frágiles por encima de los 2300-2400 m. Pueden caer al solo paso de una persona con facilidad, especialmente en orientaciones NW, N, NE y E, por lo general serán de tamaño 2, mediano, suficiente para cubrir una persona. Por debajo de los 2300 m, encontramos un manto más encostrado en superficie formado por costras no portantes. En sitios muy resguardados hay nieve reciente que puede caer de forma natural en forma de purgas en lugares muy inclinados.

Distribución del manto nivoso

Hay nieve en el suelo por encima de 1.400- 1.500 m. Sin embargo, el manto es esquiable por encima de 1.500-1.600 m. Con la nevada de ayer lunes los grosores alcanzan los 120-140 cm a 2.200 m. Son grosores muy por encima de los habituales por la época.

Tendencia para las próximas 48-72h

A partir del jueves el manto puede humedecerse hasta los 2000 m por el ascenso térmico y las precipitaciones previstas. Peligro ESTACIONARIO

El próximo boletín será emitido el día 2026-02-04

5 MUY FUERTE	4 FUERTE	3 NOTABLE	2 LIMITADO	1 DÉBIL

EAWS EUROPEAN AVALANCHE WARNING SERVICES

ICGC Institut Cartogràfic i Geològic de Catalunya

meteo.cat Servei Meteorològic de Catalunya

Boletín de peligro de aludes
Vessant Nord Cadí-Moixeró
Del 03/02/2026 al 04/02/2026

(Válido fuera pistas de esquí y zonas no controladas)

Notable (3) por encima de 2.200 m. Limitado (2) por debajo.

Situación primaria

Nieve venteada

Distribución

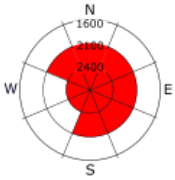

Tamaño

Origen

Tendencia

Estado del manto nivoso

La nieve humedecida por lluvia del lunes se ha encostrado superficialmente. Encima se han formado placas de viento blandas por la nevada que se dio después con el descenso de la cota de nieve. Estas placas son blandas y se prevé que con el transcurso de las horas, se vaya debilitando su contacto con la nieve subyacente. Pueden presentarse frágiles por encima de los 2200 m. Pueden caer al solo paso de una persona con facilidad, especialmente en orientaciones NW, N, NE y E, por lo general serán de tamaño 2, mediano, suficiente para cubrir una persona. Puntualmente, pueden algo mayores hasta alcanzar tamaño para enterrar a un grupo de personas. Por debajo de los 2200 m, encontramos un manto más encostrado en superficie formado por costras no portantes. En lugares muy resguardados, como dentro de las canales, hay nieve reciente que puede caer de forma natural en forma de purgas o pequeños aludes, sobre todo en los lugares más inclinados.

Distribución del manto nivoso

Hay nieve desde 1.400 -1.500 m, esquiable por encima de unos 1.500-1.600 m. Los grosores están alrededor de 110-150 cm a 2.200 m después de la nevada de lunes a martes. Estos valores muy excedentarios por la época del año.

Tendencia para las próximas 48-72h

A partir del jueves el manto puede humedecerse hasta los 2000 m por el ascenso térmico y las precipitaciones previstas. Peligro ESTACIONARIO

El próximo boletín será emitido el día 2026-02-04

5 MUY FUERTE	4 FUERTE	3 NOTABLE	2 LIMITADO	1 DÉBIL

EAWS EUROPEAN AVALANCHE WARNING SERVICES

ICGC Institut Cartogràfic i Geològic de Catalunya

Servei Meteorològic de Catalunya

Boletín de peligro de aludes Prepirineu
Del 03/02/2026 al 04/02/2026

(Válido fuera pistas de esquí y zonas no controladas)

Notable (3) por encima de 2.200 m. Limitado (2) por debajo.

Situación primaria

Nieve venteada

Distribución

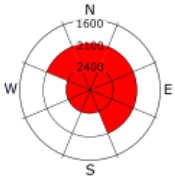

Tamaño

Origen

Tendencia

Estado del manto nivoso

La nieve humedecida por lluvia del lunes se ha encostrado superficialmente. Encima se han formado placas de viento blandas por la nevada que se dio después con el descenso de la cota de nieve. Estas placas son blandas y se prevé que con el transcurso de las horas, se vaya debilitando su contacto con la nieve subyacente. Pueden presentarse frágiles por encima de los 2200 m. Pueden caer al solo paso de una persona con facilidad, especialmente en orientaciones NW, N, NE y E, por lo general serán de tamaño 2, mediano, suficiente para cubrir una persona. Puntualmente, pueden algo mayores hasta alcanzar tamaño para enterrar a un grupo de personas. Por debajo de los 2200 m, encontramos un manto más encostrado en superficie formado por costras no portantes. En lugares muy resguardados, hay nieve reciente que puede caer de forma natural en forma de purgas o pequeños aludes, sobre todo en los lugares más inclinados.

Distribución del manto nivoso

Hay nieve desde 1400-1500 m. El manto es esquiable a partir de 1600 m. Los grosores están alrededor de 100-120 cm a unos 2.200 m; son superiores a los habituales.

Tendencia para las próximas 48-72h

A partir del jueves el manto puede humedecerse hasta los 2000 m por el ascenso térmico y las precipitaciones previstas. Peligro ESTACIONARIO

El próximo boletín será emitido el día 2026-02-04

5 MUY FUERTE	4 FUERTE	3 NOTABLE	2 LIMITADO	1 DÉBIL

EAWS EUROPEAN AVALANCHE WARNING SERVICES

ICGC Institut Cartogràfic i Geològic de Catalunya

meteo.cat Servei Meteorològic de Catalunya

Boletín de peligro de aludes Ter-Freser
Del 03/02/2026 al 04/02/2026

(Válido fuera pistas de esquí y zonas no controladas)

Notable (3) por encima de 2.400 m. Limitado (2) por debajo.

Situación primaria

Nieve venteada

Distribución

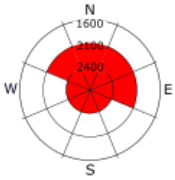

Tamaño

Origen

Tendencia

Estado del manto nivoso

La nieve humedecida por lluvia del lunes se ha encostrado. Encima se han formado placas de viento blandas por la nevada que se dio después con el descenso de la cota de nieve. Estas placas son blandas y se prevé que con el transcurso de las horas, se vaya debilitando su contacto con la nieve subyacente. Se pueden presentar frágiles por encima de los 2300-2400 m. Pueden caer al solo paso de una persona con facilidad, especialmente en orientaciones NW, N, NE y E, por lo general serán de tamaño 2, mediano, suficiente para cubrir una persona. Por debajo de los 2300 m, encontramos un manto más encostrado en superficie formado por costras no portantes. En sitios muy resguardados hay nieve reciente que puede caer de forma natural en forma de purgas en lugares muy inclinados.

Distribución del manto nivoso

Hay nieve desde 1.400-1.500 m, esquiable por encima de 1.500 a 1.600 m. Los espesores, con la reciente nieve de ayer lunes pasan a ser de entre 100-140 cm a unos 2.200 my son muy excedentarios para la época del año.

Tendencia para las próximas 48-72h

A partir del jueves el manto puede humedecerse hasta los 2000 m por el ascenso térmico y las precipitaciones previstas. Peligro ESTACIONARIO

El próximo boletín será emitido el día 2026-02-04

5 MUY FUERTE	4 FUERTE	3 NOTABLE	2 LIMITADO	1 DÉBIL

EAWS EUROPEAN AVALANCHE WARNING SERVICES