MINISTERO DELLA DIFESA

meteomont
Servizio Nazionale di previsione neve e valanghe

EAWS EUROPEAN AVALANCHE WARNING SERVICES

CARABINIERI

# ALPI CARNICHE ORIENTALI

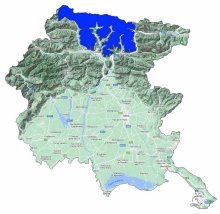

Bollettino Valanghe N. 332/2026 del 02/02/2026 ore 14.00
Validità 48 ore prossima emissione 03/02/2026

**A cura del Servizio METEOMONT dell'ARMA dei CARABINIERI**
**In collaborazione con Servizio Meteorologico dell'Aeronautica militare**

## SITUAZIONE alle 14:00 del 02/02/2026

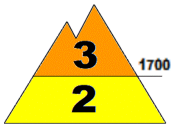


**SITUAZIONE TIPO: nevicata dopo un lungo periodo di freddo.**

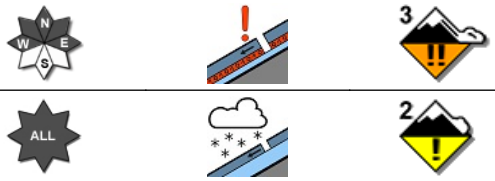


**SITUAZIONE TIPO: nessuna situazione tipo evidente.**

| Quota neve (mslm) | Nord | Sud |
|---|---|---|
| | 700 - 800 | 800 - 1200 |

| Altezza Neve (cm) | Neve al suolo | Neve Fresca | Quota (mslm) |
|---|---|---|---|
| | 70 | 00 | 1760 |
| | 35 | 00 | 1327 |

**VALANGHE OSSERVATE: -.**

## PREVISIONI 03/02/2026

# GRADO DI PERICOLO: MARCATO 3

## SITUAZIONE TIPO: neve a debole coesione e vento.




## SITUAZIONE TIPO: neve a debole coesione e vento.

**MANTO NEVOSO: La stabilità del manto nevoso è scarsa su molti punti (aree) per tutte le esposizioni al di sopra di 1700 mslm, possibili valanghe di dimensioni medie.**
**La stabilità del manto nevoso è scarsa su alcuni punti (aree) per tutte le esposizioni al di sotto di 1700 mslm, possibili valanghe di dimensioni medie.**

## AVVERTENZE

In considerazione dei recenti apporti di neve fresca, è richiesta un'ottima valutazione locale della stabilità ed individuazione dell'itinerario.

## SCALA EUROPEA DEL GRADO DI PERICOLO VALANGHE

5 - MOLTO FORTE | 4 - FORTE | 3 - MARCATO | 2 - MODERATO | 1 - DEBOLE | NO NEVE | NO INFO

## LEGENDA PROBLEMA

NEVE FRESCA | LASTRONI DA VENTO | STRATI DEBOLI PERSISTENTI | NEVE BAGNATA | SLITTAMENTO | CORNICI | NESSUN PROBLEMA VALANGHIVO EVIDENTE | NO_INFO

**Bollettino realizzato su scala sinottica-regionale (standard EAWS). La sua valutazione non può escludere in alcun modo la necessità di una seria e capace valutazione locale del pericolo (singolo pendio) che può essere anche sensibilmente diverso. Le previsioni meteorologiche sono relative all'orario UTC (per l'Italia +1 in inverno e +2 in estate).**

MINISTERO DELLA DIFESA

meteomont
Servizio Nazionale di previsione neve e valanghe

EAWS EUROPEAN AVALANCHE WARNING SERVICES

CARABINIERI

# ALPI CARNICHE ORIENTALI

## PREVISIONE METEO

| Quota | | 03/02/2026 h6:00 | 03/02/2026 h12:00 | 03/02/2026 h18:00 |
|---|---|---|---|---|
| 1000 | Venti | 01 Nodi da Sud | 02 Nodi da Sud | 01 Nodi da Sud |
| | Temperature | -03 °C | +02 °C | +02 °C |
| | Temp.percepita | -3 °C | 2 °C | 2 °C |
| 2000 | Venti | 05 Nodi da Sud | 07 Nodi da Sud | 05 Nodi da Sud |
| | Temperature | -04 °C | -02 °C | -02 °C |
| | Temp.percepita | -8 °C | -6 °C | -5 °C |
| 3000 | Venti | 22 Nodi da S-Ovest | 15 Nodi da S-Ovest | 10 Nodi da S-Ovest |
| | Temperature | -07 °C | -08 °C | -09 °C |
| | Temp.percepita | -17 °C | -17 °C | -16 °C |
| Zero termico | | 0700-0900 m. | 1600-1800 m. | 1600-1800 m. |
| Fenomeno | | | | — |
| Stato del cielo | | | | |

## LEGENDA FENOMENI

— Assenza Fenomeni
Nebbia
Foschia
Pioggia debole
Pioggia moderata
Pioggia forte
Temporali
Nevicata debole
Nevicata moderata
Nevicata forte

## STATO DEL CIELO

Sereno
Poco nuvoloso
Nuvoloso
Molto nuvoloso
Coperto

## Parametri meteonivometrici registrati presso i campi di rilevamento il 02/02/2026.

| Località | Comune | Quota (m.s.l.m.) | Altezza neve (cm) | Neve caduta nelle 24 ore (cm) | Temp. Min (°C) | Temp. Max (°C) | Condizioni del tempo |
|---|---|---|---|---|---|---|---|
| COLLINA | Forni Avoltri (UD) | 1327 | 35 | 0 | -4 | +1 | Assenza di precipitazioni |
| ALPI CARNICHE ORIENTALI * | Ravascletto (UD) | 1760 | 70 | 0 | N.P. | N.P. | Assenza di precipitazioni |

(*) Rilievi fuori campo

**L'INFORMAZIONE E' PREVENZIONE - LEGGI L'ATTUALE GRADO DI PERICOLO VALANGHE!**

**IL CAPO DEL CENTRO NAZIONALE METEOMONT**
**(Ten. Col. RFI Emanuela Gini)**
**FIRMA AUTOGRAFA OMESSA AI SENSI**
**DELL'ART.3 DEL D.LGS N.39/1993**

Bollettino realizzato su scala sinottica-regionale (standard EAWS). La sua valutazione non può escludere in alcun modo la necessità di una seria e capace valutazione locale del pericolo (singolo pendio) che può essere anche sensibilmente diverso. Le previsioni meteorologiche sono relative all'orario UTC (per l'Italia +1 in inverno e +2 in estate).