MINISTERO DELLA DIFESA

meteomont Servizio Nazionale di previsione neve e valanghe

EAWS EUROPEAN AVALANCHE WARNING SERVICES

CARABINIERI

In collaborazione con: arpav

DOLOMITI MERIDIONALI

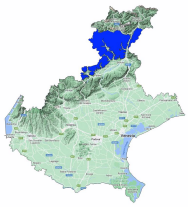

Bollettino Valanghe N. 336/2026 del 03/02/2026 ore 14.00
Validità 48 ore prossima emissione 04/02/2026

A cura del Servizio METEOMONT dell'ARMA dei CARABINIERI
In collaborazione con Servizio Meteorologico dell'Aeronautica militare

SITUAZIONE alle 14:00 del 03/02/2026

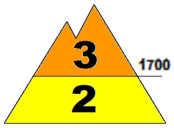

SITUAZIONE TIPO: neve a debole coesione e vento.



SITUAZIONE TIPO: neve a debole coesione e vento.

Quota neve (mslm)	Nord	Sud
	700	700

Altezza Neve (cm)	Neve al suolo	Neve Fresca	Quota (mslm)
	95	05	1920
	56	04	1820

VALANGHE OSSERVATE: -.

PREVISIONI 04/02/2026

GRADO DI PERICOLO: MARCATO 3

SITUAZIONE TIPO: neve a debole coesione e vento.

SITUAZIONE TIPO: neve a debole coesione e vento.

MANTO NEVOSO: La stabilità del manto nevoso è molto scarsa su molti punti (aree) per tutte le esposizioni al di sopra di 1600 mslm, possibili valanghe di dimensioni medie.
La stabilità del manto nevoso è scarsa su alcuni punti (aree) per tutte le esposizioni al di sotto di 1600 mslm, possibili valanghe di dimensioni medie.

AVVERTENZE

In considerazione dei recenti apporti di neve fresca, è richiesta un'ottima valutazione locale della stabilità ed individuazione dell'itinerario.

SCALA EUROPEA DEL GRADO DI PERICOLO VALANGHE

LEGENDA PROBLEMA

Bollettino realizzato su scala sinottica-regionale (standard EAWS). La sua valutazione non può escludere in alcun modo la necessità di una seria e capace valutazione locale del pericolo (singolo pendio) che può essere anche sensibilmente diverso. Le previsioni meteorologiche sono relative all'orario UTC (per l'Italia +1 in inverno e +2 in estate).

MINISTERO DELLA DIFESA

meteomont
Servizio Nazionale di previsione neve e valanghe

EAWS EUROPEAN AVALANCHE WARNING SERVICES

CARABINIERI

In collaborazione con: arpav

DOLOMITI MERIDIONALI

PREVISIONE METEO

Quota		04/02/2026 h6:00	04/02/2026 h12:00	04/02/2026 h18:00
1000	Venti	03 Nodi da Nord	03 Nodi da Sud	02 Nodi da Est
	Temperature	+01 °C	+02 °C	+02 °C
	Temp.percepita	-1 °C	0 °C	2 °C
2000	Venti	06 Nodi da S-Est	11 Nodi da Sud	04 Nodi da S-Est
	Temperature	-02 °C	-01 °C	-02 °C
	Temp.percepita	-6 °C	-7 °C	-5 °C
3000	Venti	12 Nodi da Sud	17 Nodi da Sud	07 Nodi da Sud
	Temperature	-07 °C	-07 °C	-07 °C
	Temp.percepita	-14 °C	-16 °C	-13 °C
Zero termico		1400-1600 m.	1700-1900 m.	1600-1800 m.
Fenomeno				
Stato del cielo				

LEGENDA FENOMENI

Assenza Fenomeni · Nebbia · Foschia · Pioggia debole · Pioggia moderata · Pioggia forte · Temporali

Nevicata debole · Nevicata moderata · Nevicata forte

STATO DEL CIELO

Sereno · Poco nuvoloso · Nuvoloso · Molto nuvoloso · Coperto

Parametri meteonivometrici registrati presso i campi di rilevamento il 03/02/2026.

Località	Comune	Quota (m.s.l.m.)	Altezza neve (cm)	Neve caduta nelle 24 ore (cm)	Temp. Min (°C)	Temp. Max (°C)	Condizioni del tempo
LE BUSE	Falcade (BL)	1820	56	4	-8	+8	Nevicata debole continua
COL. DEI BALDI *	Selva di Cadore (BL)	1920	95	5	-8	+4	Nevicata moderata
P.SO PADON	Livinallongo del Col di Lana (BL)	2369	66	10	N.P.	N.P.	Nevicata moderata
CRODA DEGLI ZINGARI *	Falcade (BL)	2300	64	4	N.P.	N.P.	Nevicata moderata

(*) Rilievi fuori campo

L'INFORMAZIONE E' PREVENZIONE - LEGGI L'ATTUALE GRADO DI PERICOLO VALANGHE!

IL CAPO DEL CENTRO NAZIONALE METEOMONT
(Ten. Col. RFI Emanuela Gini)
FIRMA AUTOGRAFA OMESSA AI SENSI
DELL'ART.3 DEL D.LGS N.39/1993

Bollettino realizzato su scala sinottica-regionale (standard EAWS). La sua valutazione non può escludere in alcun modo la necessità di una seria e capace valutazione locale del pericolo (singolo pendio) che può essere anche sensibilmente diverso. Le previsioni meteorologiche sono relative all'orario UTC (per l'Italia +1 in inverno e +2 in estate).