MINISTERO DELLA DIFESA

meteomont Servizio Nazionale di previsione neve e valanghe

EAWS EUROPEAN AVALANCHE WARNING SERVICES

CARABINIERI

## ALPI RETICHE

Bollettino Valanghe N. 335/2026 del 02/02/2026 ore 14.00
Validità 48 ore prossima emissione 03/02/2026

**A cura del Servizio METEOMONT dell'ARMA dei CARABINIERI**
**In collaborazione con Servizio Meteorologico dell'Aeronautica militare**

## SITUAZIONE alle 14:00 del 02/02/2026

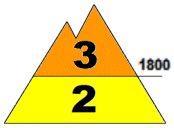


**SITUAZIONE TIPO: brina di superficie sepolta.**

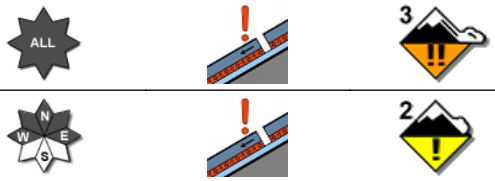


**SITUAZIONE TIPO: passaggio da poca a molta neve.**

| Quota neve (mslm) | Nord | Sud |
|---|---|---|
| | 1000 | 1400 - 1600 |

| Altezza Neve (cm) | Neve al suolo | Neve Fresca | Quota (mslm) |
|---|---|---|---|
| | 60-100 | 0 | 2500 |
| | 30-60 | 0 | 1600 |

**VALANGHE OSSERVATE: Alcune valanghe di grandi dimensioni, Valanghe di neve a debole coesione di fondo.**

## PREVISIONI 03/02/2026

# GRADO DI PERICOLO: FORTE 4

## SITUAZIONE TIPO: brina di superficie sepolta.

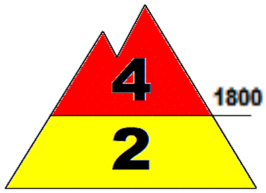


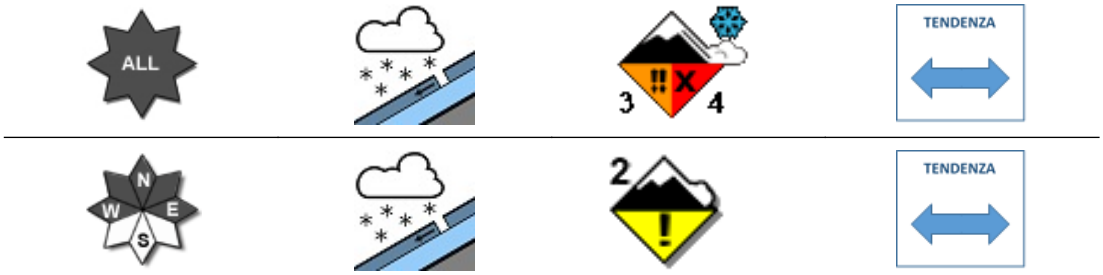


## SITUAZIONE TIPO: brina di superficie sepolta.

**MANTO NEVOSO: La stabilità del manto nevoso è molto scarsa su molti punti (aree) per tutte le esposizioni al di sopra di 1800 mslm, possibili valanghe di dimensioni grandi.**
**La stabilità del manto nevoso è scarsa su alcuni punti (aree) per versanti da ovest a est al di sotto di 1800 mslm, possibili valanghe di dimensioni medie.**

## AVVERTENZE

In considerazione delle avverse condizioni meteorologiche previste, le attività al di fuori delle piste battute e segnalate sono limitate. Se effettuate, richiedono ottime capacità di valutazione del pericolo locale.

## SCALA EUROPEA DEL GRADO DI PERICOLO VALANGHE

## LEGENDA PROBLEMA

**Bollettino realizzato su scala sinottica-regionale (standard EAWS). La sua valutazione non può escludere in alcun modo la necessità di una seria e capace valutazione locale del pericolo (singolo pendio) che può essere anche sensibilmente diverso. Le previsioni meteorologiche sono relative all'orario UTC (per l'Italia +1 in inverno e +2 in estate).**

MINISTERO DELLA DIFESA

meteomont
Servizio Nazionale di previsione neve e valanghe

EAWS EUROPEAN AVALANCHE WARNING SERVICES

CARABINIERI

# ALPI RETICHE

## PREVISIONE METEO

| Quota | | 03/02/2026 h6:00 | 03/02/2026 h12:00 | 03/02/2026 h18:00 |
|---|---|---|---|---|
| 1000 | Venti | 02 Nodi da S-Est | 01 Nodi da S-Est | 01 Nodi da S-Est |
| | Temperature | -04 °C | -03 °C | -03 °C |
| | Temp.percepita | -4 °C | -3 °C | -3 °C |
| 2000 | Venti | 02 Nodi da S-Est | 01 Nodi da S-Est | 01 Nodi da S-Est |
| | Temperature | -04 °C | -03 °C | -03 °C |
| | Temp.percepita | -4 °C | -3 °C | -3 °C |
| 3000 | Venti | 18 Nodi da Sud | 08 Nodi da S-Ovest | 05 Nodi da S-Ovest |
| | Temperature | -07 °C | -10 °C | -10 °C |
| | Temp.percepita | -16 °C | -17 °C | -15 °C |
| Zero termico | | 1200-1400 m. | 1400-1600 m. | 1400-1600 m. |
| Fenomeno | | | | |
| Stato del cielo | | | | |

## LEGENDA FENOMENI

Assenza Fenomeni · Nebbia · Foschia · Pioggia debole · Pioggia moderata · Pioggia forte · Temporali

Nevicata debole · Nevicata moderata · Nevicata forte

## STATO DEL CIELO

Sereno · Poco nuvoloso · Nuvoloso · Molto nuvoloso · Coperto

## Parametri meteonivometrici registrati presso i campi di rilevamento il 02/02/2026.

| Località | Comune | Quota (m.s.l.m.) | Altezza neve (cm) | Neve caduta nelle 24 ore (cm) | Temp. Min (°C) | Temp. Max (°C) | Condizioni del tempo |
|---|---|---|---|---|---|---|---|
| VALAR | Valdidentro (SO) | 1930 | 59 | 0 | -13 | +2 | Assenza di precipitazioni |
| DOSSO DEL VALLONE | Valfurva (SO) | 2582 | 60 | 0 | -14 | -3 | Assenza di precipitazioni |
| STODEGARDA * | Vione (BS) | 1568 | 17 | 0 | N.P. | N.P. | Assenza di precipitazioni |
| ALPE PALU' | Chiesa in Valmalenco (SO) | 2010 | 69 | 0 | -10 | 0 | Assenza di precipitazioni |
| COLONIA VIGILI | Ponte di Legno (BS) | 1640 | 58 | 0 | -10 | +3 | Assenza di precipitazioni |
| DOSSO LE PONE * | Valdisotto (SO) | 2522 | 101 | 0 | N.P. | N.P. | Assenza di precipitazioni |

(*) Rilievi fuori campo

**L'INFORMAZIONE E' PREVENZIONE - LEGGI L'ATTUALE GRADO DI PERICOLO VALANGHE!**

IL CAPO DEL CENTRO NAZIONALE METEOMONT
(Ten. Col. RFI Emanuela Gini)
FIRMA AUTOGRAFA OMESSA AI SENSI
DELL'ART.3 DEL D.LGS N.39/1993

Bollettino realizzato su scala sinottica-regionale (standard EAWS). La sua valutazione non può escludere in alcun modo la necessità di una seria e capace valutazione locale del pericolo (singolo pendio) che può essere anche sensibilmente diverso. Le previsioni meteorologiche sono relative all'orario UTC (per l'Italia +1 in inverno e +2 in estate).