MINISTERO DELLA DIFESA

meteomont
Servizio Nazionale di previsione neve e valanghe

EAWS EUROPEAN AVALANCHE WARNING SERVICES

CARABINIERI

AERONAUTICA MILITARE SERVIZIO METEOROLOGICO

ALPI RETICHE

Bollettino Valanghe N. 336/2026 del 03/02/2026 ore 14.00
Validità 48 ore prossima emissione 04/02/2026

A cura del Servizio METEOMONT dell'ARMA dei CARABINIERI
In collaborazione con Servizio Meteorologico dell'Aeronautica militare

SITUAZIONE alle 14:00 del 03/02/2026

SITUAZIONE TIPO: brina di superficie sepolta.

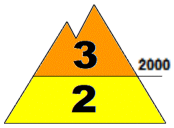



SITUAZIONE TIPO: brina di superficie sepolta.

Quota neve (mslm)	Nord	Sud
	600	600

Altezza Neve (cm)	Neve al suolo	Neve Fresca	Quota (mslm)
	60-100	10-20	2500
	35-60	5-10	1600

VALANGHE OSSERVATE: -.

PREVISIONI 04/02/2026

GRADO DI PERICOLO: MARCATO 3

SITUAZIONE TIPO: brina di superficie sepolta.

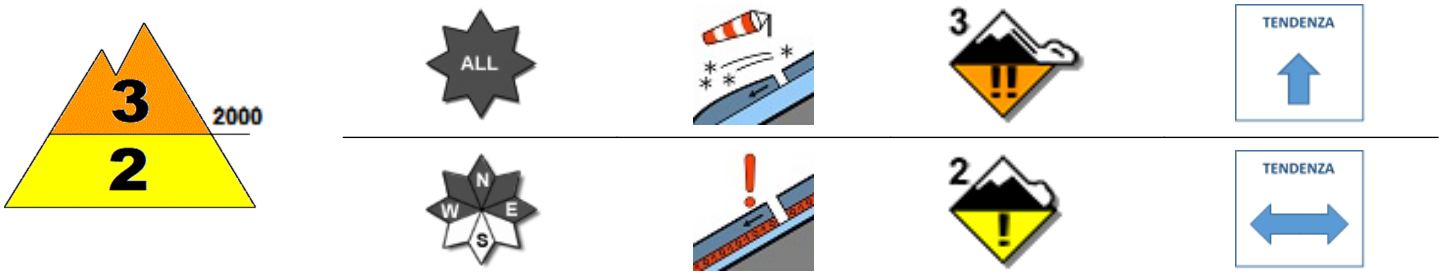

SITUAZIONE TIPO: brina di superficie sepolta.

MANTO NEVOSO: La stabilità del manto nevoso è molto scarsa su alcuni punti (aree) per tutte le esposizioni al di sopra di 2000 mslm, possibili valanghe di dimensioni grandi.
La stabilità del manto nevoso è scarsa su alcuni punti (aree) per versanti da ovest a est al di sotto di 2000 mslm, possibili valanghe di dimensioni medie.

AVVERTENZE

Viste le condizioni del manto nevoso, le attività al di fuori delle piste battute e segnalate richiedono ottime capacità di valutazione del pericolo locale.

SCALA EUROPEA DEL GRADO DI PERICOLO VALANGHE

5 - MOLTO FORTE | 4 - FORTE | 3 - MARCATO | 2 - MODERATO | 1 - DEBOLE | NO NEVE | NO INFO

LEGENDA PROBLEMA

NEVE FRESCA | LASTRONI DA VENTO | STRATI DEBOLI PERSISTENTI | NEVE BAGNATA | SLITTAMENTO | CORNICI | NESSUN PROBLEMA VALANGHIVO EVIDENTE | NO_INFO

Bollettino realizzato su scala sinottica-regionale (standard EAWS). La sua valutazione non può escludere in alcun modo la necessità di una seria e capace valutazione locale del pericolo (singolo pendio) che può essere anche sensibilmente diverso. Le previsioni meteorologiche sono relative all'orario UTC (per l'Italia +1 in inverno e +2 in estate).

MINISTERO DELLA DIFESA

meteomont
Servizio Nazionale di previsione neve e valanghe

EAWS EUROPEAN AVALANCHE WARNING SERVICES

CARABINIERI

ALPI RETICHE

PREVISIONE METEO

Quota		04/02/2026 h6:00	04/02/2026 h12:00	04/02/2026 h18:00
1000	Venti	01 Nodi da Nord	01 Nodi da Nord	00 Calma
	Temperature	-04 °C	-04 °C	-01 °C
	Temp.percepita	-4 °C	-4 °C	-1 °C
2000	Venti	01 Nodi da Nord	01 Nodi da Nord	00 Calma
	Temperature	-04 °C	-04 °C	-01 °C
	Temp.percepita	-4 °C	-4 °C	-1 °C
3000	Venti	03 Nodi da S-Est	04 Nodi da S-Est	05 Nodi da S-Est
	Temperature	-09 °C	-08 °C	-08 °C
	Temp.percepita	-12 °C	-12 °C	-13 °C
Zero termico		1300-1500 m.	1400-1600 m.	1600-1800 m.
Fenomeno		—		—
Stato del cielo				

LEGENDA FENOMENI

— Assenza Fenomeni · Nebbia · Foschia · Pioggia debole · Pioggia moderata · Pioggia forte · Temporali

Nevicata debole · Nevicata moderata · Nevicata forte

STATO DEL CIELO

Sereno · Poco nuvoloso · Nuvoloso · Molto nuvoloso · Coperto

Parametri meteonivometrici registrati presso i campi di rilevamento il 03/02/2026.

Località	Comune	Quota (m.s.l.m.)	Altezza neve (cm)	Neve caduta nelle 24 ore (cm)	Temp. Min (°C)	Temp. Max (°C)	Condizioni del tempo
SPONDA	Livigno (SO)	2150	49	2	-13	+2	Nevicata debole continua
BORMIO2000-LECCIONA	Valdisotto (SO)	2050	63	11	N.P.	N.P.	Nevicata forte
VALAR	Valdidentro (SO)	1930	65	9	-7	+1	Nevicata forte
DOSSO DEL VALLONE	Valfurva (SO)	2582	64	5	-7	-4	Nevicata moderata
SANTA APOLLONIA	Vezza d'Oglio (BS)	1599	33	6	N.P.	N.P.	Nevicata moderata
ALPE PALU'	Chiesa in Valmalenco (SO)	2010	79	18	-8	-2	Nevicata forte
PREDA	Edolo (BS)	1580	40	10	-5	+1	Nevicata moderata
VALLACCIA *	Livigno (SO)	2180	61	4	N.P.	N.P.	Nevicata moderata
CAPANNA PRESENA *	Vermiglio (TN)	2745	205	8	N.P.	N.P.	Nevicata moderata

(*) Rilievi fuori campo

L'INFORMAZIONE E' PREVENZIONE - LEGGI L'ATTUALE GRADO DI PERICOLO VALANGHE!

IL CAPO DEL CENTRO NAZIONALE METEOMONT
(Ten. Col. RFI Emanuela Gini)
FIRMA AUTOGRAFA OMESSA AI SENSI
DELL'ART.3 DEL D.LGS N.39/1993

Bollettino realizzato su scala sinottica-regionale (standard EAWS). La sua valutazione non può escludere in alcun modo la necessità di una seria e capace valutazione locale del pericolo (singolo pendio) che può essere anche sensibilmente diverso. Le previsioni meteorologiche sono relative all'orario UTC (per l'Italia +1 in inverno e +2 in estate).