MINISTERO DELLA DIFESA

meteomont Servizio Nazionale di previsione neve e valanghe

EAWS EUROPEAN AVALANCHE WARNING SERVICES

CARABINIERI

ALPI OROBICHE

Bollettino Valanghe N. 333/2026 del 02/02/2026 ore 14.00
Validità 48 ore prossima emissione 03/02/2026

A cura del Servizio METEOMONT dell'ARMA dei CARABINIERI
In collaborazione con Servizio Meteorologico dell'Aeronautica militare

SITUAZIONE alle 14:00 del 02/02/2026

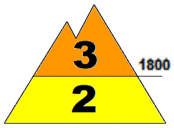

SITUAZIONE TIPO: freddo su caldo / caldo su freddo.

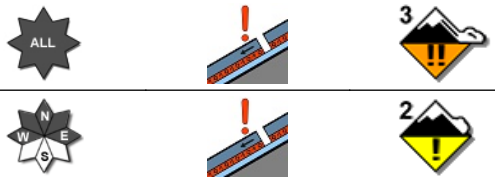

SITUAZIONE TIPO: passaggio da poca a molta neve.

Quota neve (mslm)	Nord	Sud
	900 - 1200	1200 - 1600

Altezza Neve (cm)	Neve al suolo	Neve Fresca	Quota (mslm)
	100	0	2280
	56	0	1635

VALANGHE OSSERVATE: Nessuna valanga.

PREVISIONI 03/02/2026

GRADO DI PERICOLO: FORTE 4

SITUAZIONE TIPO: brina di superficie sepolta.

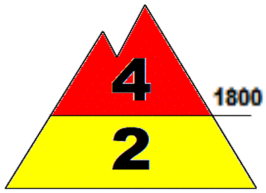

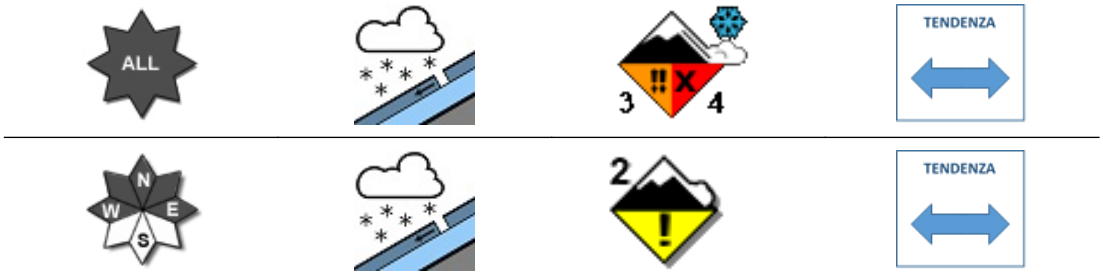

SITUAZIONE TIPO: brina di superficie sepolta.

MANTO NEVOSO: La stabilità del manto nevoso è molto scarsa su molti punti (aree) per tutte le esposizioni al di sopra di 1800 mslm, possibili valanghe di dimensioni grandi.
La stabilità del manto nevoso è scarsa su alcuni punti (aree) per versanti da ovest a est al di sotto di 1800 mslm, possibili valanghe di dimensioni medie.

AVVERTENZE

In considerazione delle avverse condizioni meteorologiche previste, le attività al di fuori delle piste battute e segnalate sono limitate. Se effettuate, richiedono ottime capacità di valutazione del pericolo locale.

SCALA EUROPEA DEL GRADO DI PERICOLO VALANGHE

LEGENDA PROBLEMA

Bollettino realizzato su scala sinottica-regionale (standard EAWS). La sua valutazione non può escludere in alcun modo la necessità di una seria e capace valutazione locale del pericolo (singolo pendio) che può essere anche sensibilmente diverso. Le previsioni meteorologiche sono relative all'orario UTC (per l'Italia +1 in inverno e +2 in estate).

MINISTERO DELLA DIFESA

meteomont
Servizio Nazionale di previsione neve e valanghe

EAWS EUROPEAN AVALANCHE WARNING SERVICES

CARABINIERI

ALPI OROBICHE

PREVISIONE METEO

Quota		03/02/2026 h6:00	03/02/2026 h12:00	03/02/2026 h18:00
1000	Venti	03 Nodi da Sud	01 Nodi da S-Ovest	01 Nodi da S-Est
	Temperature	-01 °C	-02 °C	-02 °C
	Temp.percepita	-3 °C	-2 °C	-2 °C
2000	Venti	07 Nodi da Sud	02 Nodi da S-Ovest	02 Nodi da Sud
	Temperature	-02 °C	-04 °C	-04 °C
	Temp.percepita	-6 °C	-4 °C	-4 °C
3000	Venti	23 Nodi da Sud	11 Nodi da S-Ovest	09 Nodi da S-Ovest
	Temperature	-06 °C	-10 °C	-11 °C
	Temp.percepita	-16 °C	-18 °C	-18 °C
Zero termico		1600-1800 m.	1500-1700 m.	1400-1600 m.
Fenomeno				
Stato del cielo				

LEGENDA FENOMENI

Assenza Fenomeni — Nebbia — Foschia — Pioggia debole — Pioggia moderata — Pioggia forte — Temporali

Nevicata debole — Nevicata moderata — Nevicata forte

STATO DEL CIELO

Sereno — Poco nuvoloso — Nuvoloso — Molto nuvoloso — Coperto

Parametri meteonivometrici registrati presso i campi di rilevamento il 02/02/2026.

Località	Comune	Quota (m.s.l.m.)	Altezza neve (cm)	Neve caduta nelle 24 ore (cm)	Temp. Min (°C)	Temp. Max (°C)	Condizioni del tempo
VODALA	Gromo (BG)	1635	58	0	-7	+2	Assenza di precipitazioni
QUARTA BAITA	Foppolo (BG)	1760	55	0	-8	+2	Assenza di precipitazioni
CIMA BIANCA	Colere (BG)	2080	105	0	-8	+3	Assenza di precipitazioni
LAGO BRANCHINO *	Ardesio (BG)	1672	60	0	N.P.	N.P.	Assenza di precipitazioni
PIZZO MERIGGIO *	Albosaggia (SO)	2282	101	0	N.P.	N.P.	Assenza di precipitazioni

(*) Rilievi fuori campo

L'INFORMAZIONE E' PREVENZIONE - LEGGI L'ATTUALE GRADO DI PERICOLO VALANGHE!

IL CAPO DEL CENTRO NAZIONALE METEOMONT
(Ten. Col. RFI Emanuela Gini)
FIRMA AUTOGRAFA OMESSA AI SENSI
DELL'ART.3 DEL D.LGS N.39/1993

Bollettino realizzato su scala sinottica-regionale (standard EAWS). La sua valutazione non può escludere in alcun modo la necessità di una seria e capace valutazione locale del pericolo (singolo pendio) che può essere anche sensibilmente diverso. Le previsioni meteorologiche sono relative all'orario UTC (per l'Italia +1 in inverno e +2 in estate).