MINISTERO DELLA DIFESA

meteomont
Servizio Nazionale di previsione neve e valanghe

EAWS EUROPEAN AVALANCHE WARNING SERVICES

CARABINIERI

AERONAUTICA MILITARE SERVIZIO METEOROLOGICO

ALPI OROBICHE

Bollettino Valanghe N. 334/2026 del 03/02/2026 ore 14.00
Validità 48 ore prossima emissione 04/02/2026

A cura del Servizio METEOMONT dell'ARMA dei CARABINIERI
In collaborazione con Servizio Meteorologico dell'Aeronautica militare

SITUAZIONE alle 14:00 del 03/02/2026

SITUAZIONE TIPO: brina di superficie sepolta.

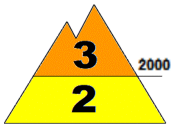



SITUAZIONE TIPO: brina di superficie sepolta.

Quota neve (mslm)	Nord	Sud
	700	700

Altezza Neve (cm)	Neve al suolo	Neve Fresca	Quota (mslm)
	80-120	15-20	2280
	67	20	1635

VALANGHE OSSERVATE: -.

PREVISIONI 04/02/2026

GRADO DI PERICOLO: MARCATO 3

SITUAZIONE TIPO: brina di superficie sepolta.

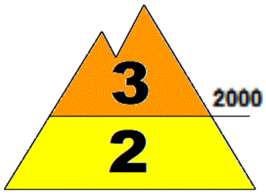

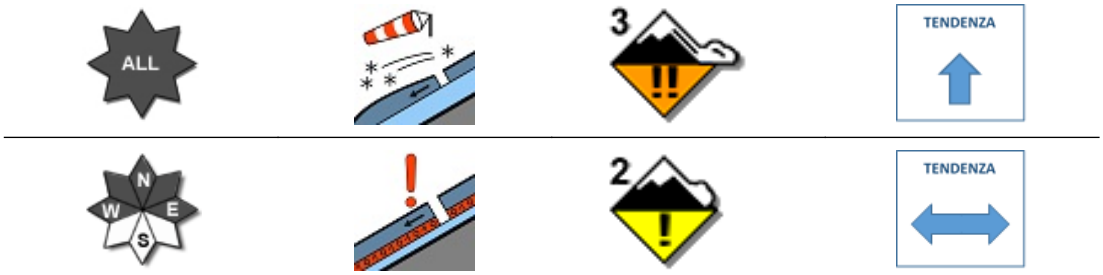

SITUAZIONE TIPO: brina di superficie sepolta.

MANTO NEVOSO: La stabilità del manto nevoso è molto scarsa su alcuni punti (aree) per tutte le esposizioni al di sopra di 2000 mslm, possibili valanghe di dimensioni grandi.
La stabilità del manto nevoso è scarsa su alcuni punti (aree) per versanti da ovest a est al di sotto di 2000 mslm, possibili valanghe di dimensioni medie.

AVVERTENZE

Viste le condizioni del manto nevoso, le attività al di fuori delle piste battute e segnalate richiedono ottime capacità di valutazione del pericolo locale.

SCALA EUROPEA DEL GRADO DI PERICOLO VALANGHE

LEGENDA PROBLEMA

Bollettino realizzato su scala sinottica-regionale (standard EAWS). La sua valutazione non può escludere in alcun modo la necessità di una seria e capace valutazione locale del pericolo (singolo pendio) che può essere anche sensibilmente diverso. Le previsioni meteorologiche sono relative all'orario UTC (per l'Italia +1 in inverno e +2 in estate).

MINISTERO DELLA DIFESA

meteomont
Servizio Nazionale di previsione neve e valanghe

EAWS EUROPEAN AVALANCHE WARNING SERVICES

CARABINIERI

ALPI OROBICHE

PREVISIONE METEO

Quota		04/02/2026 h6:00	04/02/2026 h12:00	04/02/2026 h18:00
1000	Venti	01 Nodi da N-Est	01 Nodi da Est	00 Calma
	Temperature	-02 °C	-01 °C	+00 °C
	Temp.percepita	-2 °C	-1 °C	0 °C
2000	Venti	02 Nodi da Est	03 Nodi da Est	02 Nodi da S-Est
	Temperature	-03 °C	-02 °C	-02 °C
	Temp.percepita	-3 °C	-4 °C	-2 °C
3000	Venti	05 Nodi da S-Est	15 Nodi da S-Est	08 Nodi da S-Est
	Temperature	-09 °C	-08 °C	-08 °C
	Temp.percepita	-14 °C	-17 °C	-14 °C
Zero termico		1300-1500 m.	1700-1900 m.	1700-1900 m.
Fenomeno		—		—
Stato del cielo				

LEGENDA FENOMENI

— Assenza Fenomeni · Nebbia · Foschia · Pioggia debole · Pioggia moderata · Pioggia forte · Temporali

Nevicata debole · Nevicata moderata · Nevicata forte

STATO DEL CIELO

Sereno · Poco nuvoloso · Nuvoloso · Molto nuvoloso · Coperto

Parametri meteonivometrici registrati presso i campi di rilevamento il 03/02/2026.

Località	Comune	Quota (m.s.l.m.)	Altezza neve (cm)	Neve caduta nelle 24 ore (cm)	Temp. Min (°C)	Temp. Max (°C)	Condizioni del tempo
VODALA	Gromo (BG)	1635	67	20	-5	-1	Nevicata forte
QUARTA BAITA	Foppolo (BG)	1760	65	10	-7	-1	Nevicata debole continua
PASSO DELLA PRESOLANA *	Angolo Terme (BS)	1325	20	5	N.P.	N.P.	Nevicata moderata
VAL CONCHETTA *	Vilminore di Scalve (BG)	1910	75	15	N.P.	N.P.	Nevicata debole continua
CIMA BIANCA *	Colere (BG)	2140	119	15	-4	-2	Nevicata moderata

(*) Rilievi fuori campo

L'INFORMAZIONE E' PREVENZIONE - LEGGI L'ATTUALE GRADO DI PERICOLO VALANGHE!

IL CAPO DEL CENTRO NAZIONALE METEOMONT
(Ten. Col. RFI Emanuela Gini)
FIRMA AUTOGRAFA OMESSA AI SENSI
DELL'ART.3 DEL D.LGS N.39/1993

Bollettino realizzato su scala sinottica-regionale (standard EAWS). La sua valutazione non può escludere in alcun modo la necessità di una seria e capace valutazione locale del pericolo (singolo pendio) che può essere anche sensibilmente diverso. Le previsioni meteorologiche sono relative all'orario UTC (per l'Italia +1 in inverno e +2 in estate).