MINISTERO DELLA DIFESA

meteomont
Servizio Nazionale di previsione neve e valanghe

EAWS EUROPEAN AVALANCHE WARNING SERVICES

CARABINIERI

ALPI LEPONTINE

Bollettino Valanghe N. 341/2026 del 03/02/2026 ore 14.00
Validità 48 ore prossima emissione 04/02/2026

A cura del Servizio METEOMONT dell'ARMA dei CARABINIERI
In collaborazione con Servizio Meteorologico dell'Aeronautica militare

SITUAZIONE alle 14:00 del 03/02/2026

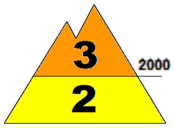

SITUAZIONE TIPO: neve a debole coesione e vento.

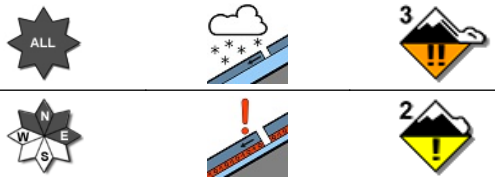

SITUAZIONE TIPO: nessuna situazione tipo evidente.

Quota neve (mslm)	Nord	Sud
	500	500

Altezza Neve (cm)	Neve al suolo	Neve Fresca	Quota (mslm)
	133	012	2453
	075	012	1634

VALANGHE OSSERVATE: -.

PREVISIONI 04/02/2026

GRADO DI PERICOLO: MARCATO 3

SITUAZIONE TIPO: nessuna situazione tipo evidente.

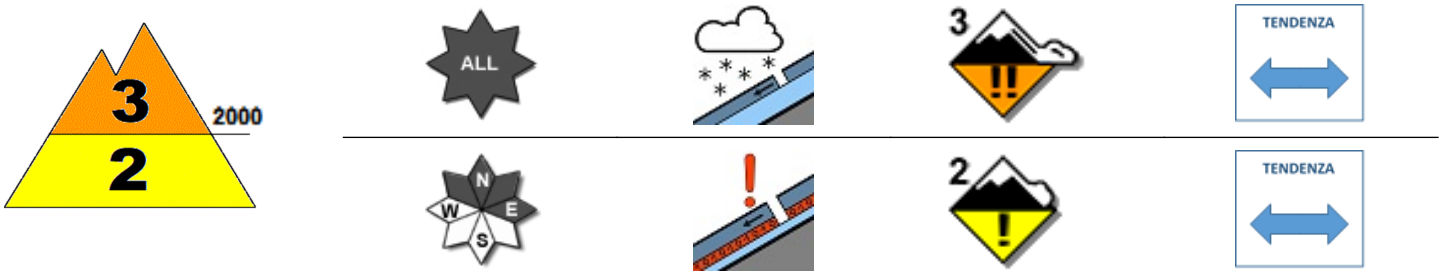

SITUAZIONE TIPO: nessuna situazione tipo evidente.

MANTO NEVOSO: La stabilità del manto nevoso è scarsa su molti punti (aree) per tutte le esposizioni al di sopra di 2000 mslm, possibili valanghe di dimensioni medie.
La stabilità del manto nevoso è scarsa su alcuni punti (aree) per versanti in ombra al di sotto di 2000 mslm, possibili valanghe di dimensioni medie.

AVVERTENZE

In considerazione delle avverse condizioni meteorologiche in atto, e della scarsa visibilità, risulterà difficoltosa l'individuazione dell'itinerario e della valutazione del singolo pendio.

SCALA EUROPEA DEL GRADO DI PERICOLO VALANGHE

5 - MOLTO FORTE | 4 - FORTE | 3 - MARCATO | 2 - MODERATO | 1 - DEBOLE | NO NEVE | NO INFO

LEGENDA PROBLEMA

NEVE FRESCA | LASTRONI DA VENTO | STRATI DEBOLI PERSISTENTI | NEVE BAGNATA | SLITTAMENTO | CORNICI | NESSUN PROBLEMA VALANGHIVO EVIDENTE | NO_INFO

Bollettino realizzato su scala sinottica-regionale (standard EAWS). La sua valutazione non può escludere in alcun modo la necessità di una seria e capace valutazione locale del pericolo (singolo pendio) che può essere anche sensibilmente diverso. Le previsioni meteorologiche sono relative all'orario UTC (per l'Italia +1 in inverno e +2 in estate).

MINISTERO DELLA DIFESA

meteomont
Servizio Nazionale di previsione neve e valanghe

EAWS EUROPEAN AVALANCHE WARNING SERVICES

CARABINIERI

ALPI LEPONTINE

PREVISIONE METEO

Quota		04/02/2026 h6:00	04/02/2026 h12:00	04/02/2026 h18:00
1000	Venti	01 nodi da N-Ovest	00 Calma	01 Nodi da Nord
	Temperature	-03 °C	-01 °C	-01 °C
	Temp.percepita	-3 °C	-1 °C	-1 °C
2000	Venti	01 Nodi da S-Ovest	01 Nodi da Ovest	03 Nodi da Nord
	Temperature	-04 °C	-03 °C	-02 °C
	Temp.percepita	-4 °C	-3 °C	-4 °C
3000	Venti	04 Nodi da Sud	03 Nodi da Sud	04 Nodi da Nord
	Temperature	-11 °C	-09 °C	-09 °C
	Temp.percepita	-15 °C	-12 °C	-13 °C
Zero termico		1100-1300 m.	1100-1300 m.	1100-1300 m.
Fenomeno		—	—	—
Stato del cielo				

LEGENDA FENOMENI

— Assenza Fenomeni · Nebbia · Foschia · Pioggia debole · Pioggia moderata · Pioggia forte · Temporali

Nevicata debole · Nevicata moderata · Nevicata forte

STATO DEL CIELO

Sereno · Poco nuvoloso · Nuvoloso · Molto nuvoloso · Coperto

Parametri meteonivometrici registrati presso i campi di rilevamento il 03/02/2026.

Località	Comune	Quota (m.s.l.m.)	Altezza neve (cm)	Neve caduta nelle 24 ore (cm)	Temp. Min (°C)	Temp. Max (°C)	Condizioni del tempo
PRAUDINA. *	Santa Maria Maggiore (VB)	863	26	9	N.P.	N.P.	Nevicata moderata
CANZA *	Formazza (VB)	1419	55	8	N.P.	N.P.	Nevicata forte
MARIA LUISA *	Formazza (VB)	2173	110	10	N.P.	N.P.	Nevicata debole continua

(*) Rilievi fuori campo

L'INFORMAZIONE E' PREVENZIONE - LEGGI L'ATTUALE GRADO DI PERICOLO VALANGHE!

IL CAPO DEL CENTRO NAZIONALE METEOMONT
(Ten. Col. RFI Emanuela Gini)
FIRMA AUTOGRAFA OMESSA AI SENSI
DELL'ART.3 DEL D.LGS N.39/1993

Bollettino realizzato su scala sinottica-regionale (standard EAWS). La sua valutazione non può escludere in alcun modo la necessità di una seria e capace valutazione locale del pericolo (singolo pendio) che può essere anche sensibilmente diverso. Le previsioni meteorologiche sono relative all'orario UTC (per l'Italia +1 in inverno e +2 in estate).