MINISTERO DELLA DIFESA

meteomont
Servizio Nazionale di previsione neve e valanghe

EAWS EUROPEAN AVALANCHE WARNING SERVICES

CARABINIERI

ALPI COZIE NORD

Bollettino Valanghe N. 333/2026 del 02/02/2026 ore 14.00
Validità 48 ore prossima emissione 03/02/2026
A cura del Servizio METEOMONT dell'ARMA dei CARABINIERI
In collaborazione con Servizio Meteorologico dell'Aeronautica militare

SITUAZIONE alle 14:00 del 02/02/2026

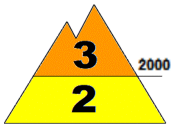

SITUAZIONE TIPO: neve a debole coesione e vento.

SITUAZIONE TIPO: nessuna situazione tipo evidente.

	Nord	Sud
Quota neve (mslm)	*1000*	*1200*

	Neve al suolo	Neve Fresca	Quota (mslm)
Altezza Neve (cm)	*119*	*000*	*2280*
	075	*000*	*1840*

VALANGHE OSSERVATE: Nessuna valanga.

PREVISIONI 03/02/2026

GRADO DI PERICOLO: MARCATO 3

SITUAZIONE TIPO: nessuna situazione tipo evidente.

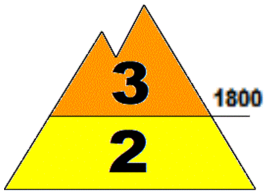

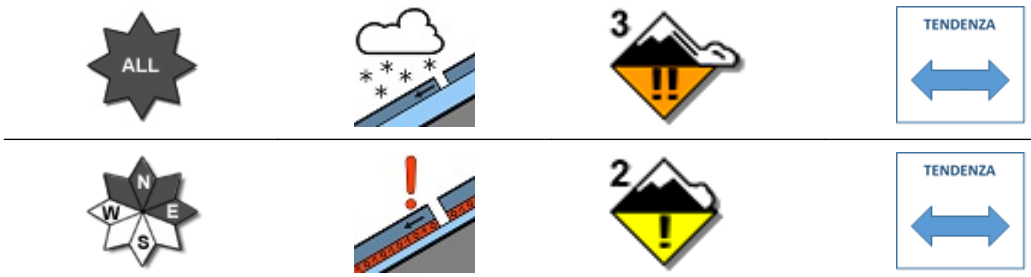

SITUAZIONE TIPO: nessuna situazione tipo evidente.

MANTO NEVOSO: La stabilità del manto nevoso è scarsa su molti punti (aree) per tutte le esposizioni al di sopra di 1800 mslm, possibili valanghe di dimensioni medie.
La stabilità del manto nevoso è scarsa su alcuni punti (aree) per versanti in ombra al di sotto di 1800 mslm, possibili valanghe di dimensioni medie.

AVVERTENZE

In considerazione delle avverse condizioni meteorologiche previste, e della scarsa visibilità, risulterà difficoltosa l'individuazione dell'itinerario e della valutazione del singolo pendio.

SCALA EUROPEA DEL GRADO DI PERICOLO VALANGHE

5 - MOLTO FORTE · *4 - FORTE* · *3 - MARCATO* · *2 - MODERATO* · *1 - DEBOLE* · NO NEVE *NO NEVE* · *NO INFO*

LEGENDA PROBLEMA

NEVE FRESCA · *LASTRONI DA VENTO* · *STRATI DEBOLI PERSISTENTI* · *NEVE BAGNATA* · *SLITTAMENTO* · *CORNICI* · *NESSUN PROBLEMA VALANGHIVO EVIDENTE* · *NO_INFO*

Bollettino realizzato su scala sinottica-regionale (standard EAWS). La sua valutazione non può escludere in alcun modo la necessità di una seria e capace valutazione locale del pericolo (singolo pendio) che può essere anche sensibilmente diverso. Le previsioni meteorologiche sono relative all'orario UTC (per l'Italia +1 in inverno e +2 in estate).

MINISTERO DELLA DIFESA

meteomont
Servizio Nazionale di previsione neve e valanghe

EAWS EUROPEAN AVALANCHE WARNING SERVICES

CARABINIERI

ALPI COZIE NORD

PREVISIONE METEO

Quota		03/02/2026 h6:00	03/02/2026 h12:00	03/02/2026 h18:00
1000	Venti	01 Nodi da Ovest	02 Nodi da S-Est	01 Nodi da S-Est
	Temperature	-04 °C	-04 °C	-04 °C
	Temp.percepita	-4 °C	-4 °C	-4 °C
2000	Venti	01 Nodi da Sud	02 Nodi da Sud	02 Nodi da S-Est
	Temperature	-06 °C	-05 °C	-07 °C
	Temp.percepita	-6 °C	-5 °C	-7 °C
3000	Venti	13 Nodi da S-Ovest	11 Nodi da S-Ovest	08 Nodi da S-Ovest
	Temperature	-09 °C	-09 °C	-09 °C
	Temp.percepita	-17 °C	-17 °C	-15 °C
Zero termico		0900-1100 m.	0900-1100 m.	0900-1100 m.
Fenomeno			—	—
Stato del cielo				

LEGENDA FENOMENI

Assenza Fenomeni — Nebbia — Foschia — Pioggia debole — Pioggia moderata — Pioggia forte — Temporali

Nevicata debole — Nevicata moderata — Nevicata forte

STATO DEL CIELO

Sereno — Poco nuvoloso — Nuvoloso — Molto nuvoloso — Coperto

Parametri meteonivometrici registrati presso i campi di rilevamento il 02/02/2026.

Località	Comune	Quota (m.s.l.m.)	Altezza neve (cm)	Neve caduta nelle 24 ore (cm)	Temp. Min (°C)	Temp. Max (°C)	Condizioni del tempo
PRINCIPI	Sestriere (TO)	2000	90	0	-11	-2	Assenza di precipitazioni
PRAGELATO	Pragelato (TO)	1550	70	0	-12	+4	Assenza di precipitazioni
MONTE BANCHETTA *	Pragelato (TO)	2610	93	0	N.P.	N.P.	Assenza di precipitazioni

(*) Rilievi fuori campo

L'INFORMAZIONE E' PREVENZIONE - LEGGI L'ATTUALE GRADO DI PERICOLO VALANGHE!

IL CAPO DEL CENTRO NAZIONALE METEOMONT
(Ten. Col. RFI Emanuela Gini)
FIRMA AUTOGRAFA OMESSA AI SENSI
DELL'ART.3 DEL D.LGS N.39/1993