MINISTERO DELLA DIFESA

meteomont
Servizio Nazionale di previsione neve e valanghe

EAWS EUROPEAN AVALANCHE WARNING SERVICES

CARABINIERI

ALPI COZIE SUD

Bollettino Valanghe N. 333/2026 del 02/02/2026 ore 14.00
Validità 48 ore prossima emissione 03/02/2026

A cura del Servizio METEOMONT dell'ARMA dei CARABINIERI
In collaborazione con Servizio Meteorologico dell'Aeronautica militare

SITUAZIONE alle 14:00 del 02/02/2026

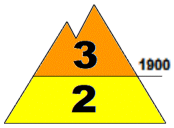

SITUAZIONE TIPO: neve a debole coesione e vento.

SITUAZIONE TIPO: neve da slittamento.

Quota neve (mslm)	Nord	Sud
	700	800

Altezza Neve (cm)	Neve al suolo	Neve Fresca	Quota (mslm)
	112	000	2135
	109	000	1750

VALANGHE OSSERVATE: -.

PREVISIONI 03/02/2026

GRADO DI PERICOLO: MARCATO 3

SITUAZIONE TIPO: nessuna situazione tipo evidente.

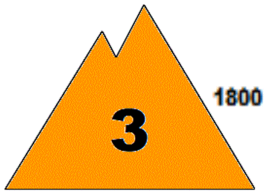

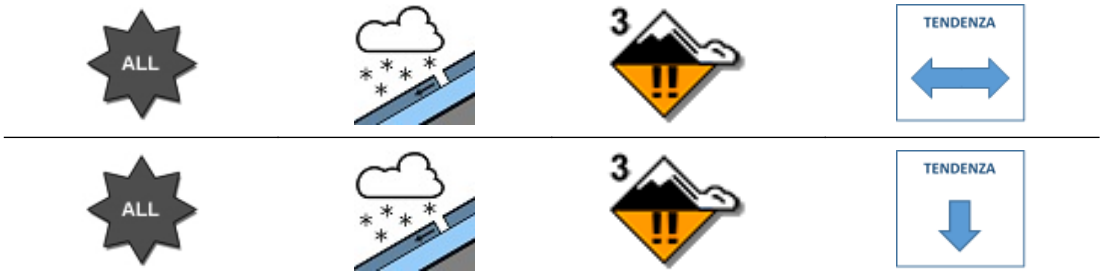

SITUAZIONE TIPO: nessuna situazione tipo evidente.

MANTO NEVOSO: La stabilità del manto nevoso è scarsa su molti punti (aree) per tutte le esposizioni al di sopra di 1800 mslm, possibili valanghe di dimensioni medie.
La stabilità del manto nevoso è scarsa su molti punti (aree) per tutte le esposizioni al di sotto di 1800 mslm, possibili valanghe di dimensioni medie.

AVVERTENZE

In considerazione delle avverse condizioni meteorologiche previste, e della scarsa visibilità, risulterà difficoltosa l'individuazione dell'itinerario e della valutazione del singolo pendio.

SCALA EUROPEA DEL GRADO DI PERICOLO VALANGHE

5 - MOLTO FORTE | *4 - FORTE* | *3 - MARCATO* | *2 - MODERATO* | *1 - DEBOLE* | NO NEVE *NO NEVE* | *NO INFO*

LEGENDA PROBLEMA

NEVE FRESCA | *LASTRONI DA VENTO* | *STRATI DEBOLI PERSISTENTI* | *NEVE BAGNATA* | *SLITTAMENTO* | *CORNICI* | *NESSUN PROBLEMA VALANGHIVO EVIDENTE* | *NO_INFO*

Bollettino realizzato su scala sinottica-regionale (standard EAWS). La sua valutazione non può escludere in alcun modo la necessità di una seria e capace valutazione locale del pericolo (singolo pendio) che può essere anche sensibilmente diverso. Le previsioni meteorologiche sono relative all'orario UTC (per l'Italia +1 in inverno e +2 in estate).

MINISTERO DELLA DIFESA

meteomont
Servizio Nazionale di previsione neve e valanghe

EAWS EUROPEAN AVALANCHE WARNING SERVICES

CARABINIERI

ALPI COZIE SUD

PREVISIONE METEO

Quota		03/02/2026 h6:00	03/02/2026 h12:00	03/02/2026 h18:00
1000	Venti	01 nodi da N-Ovest	01 Nodi da Sud	01 Nodi da N-Est
	Temperature	-06 °C	+00 °C	-06 °C
	Temp.percepita	-6 °C	0 °C	-6 °C
2000	Venti	03 Nodi da S-Ovest	05 Nodi da S-Ovest	00 Calma
	Temperature	-04 °C	-01 °C	-06 °C
	Temp.percepita	-6 °C	-4 °C	-6 °C
3000	Venti	15 Nodi da S-Ovest	13 Nodi da S-Ovest	10 Nodi da S-Ovest
	Temperature	-10 °C	-10 °C	-10 °C
	Temp.percepita	-19 °C	-19 °C	-18 °C
Zero termico		0800-1000 m.	1100-1300 m.	0900-1100 m.
Fenomeno		—	—	—
Stato del cielo				

LEGENDA FENOMENI

Assenza Fenomeni — Nebbia — Foschia — Pioggia debole — Pioggia moderata — Pioggia forte — Temporali

Nevicata debole — Nevicata moderata — Nevicata forte

STATO DEL CIELO

Sereno — Poco nuvoloso — Nuvoloso — Molto nuvoloso — Coperto

Parametri meteonivometrici registrati presso i campi di rilevamento il 02/02/2026.

Località	Comune	Quota (m.s.l.m.)	Altezza neve (cm)	Neve caduta nelle 24 ore (cm)	Temp. Min (°C)	Temp. Max (°C)	Condizioni del tempo
BORGATA CHIESA	Bellino (CN)	1480	77	0	N.P.	N.P.	Assenza di precipitazioni

(*) Rilievi fuori campo

L'INFORMAZIONE E' PREVENZIONE - LEGGI L'ATTUALE GRADO DI PERICOLO VALANGHE!

IL CAPO DEL CENTRO NAZIONALE METEOMONT
(Ten. Col. RFI Emanuela Gini)
FIRMA AUTOGRAFA OMESSA AI SENSI
DELL'ART.3 DEL D.LGS N.39/1993