MINISTERO DELLA DIFESA

meteomont
Servizio Nazionale di previsione neve e valanghe

EAWS EUROPEAN AVALANCHE WARNING SERVICES

CARABINIERI

APPENNINO EMILIANO CENTRALE

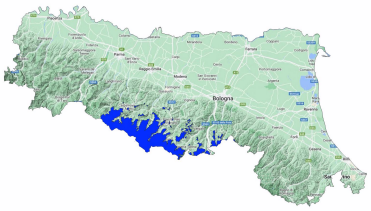

Bollettino Valanghe N. 306/2026 del 02/02/2026 ore 14.00
Validità 48 ore prossima emissione 03/02/2026

A cura del Servizio METEOMONT dell'ARMA dei CARABINIERI
In collaborazione con Servizio Meteorologico dell'Aeronautica militare

SITUAZIONE alle 14:00 del 02/02/2026

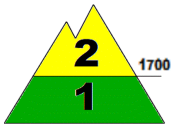

SITUAZIONE TIPO: passaggio da poca a molta neve.

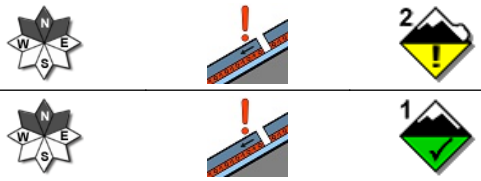

SITUAZIONE TIPO: passaggio da poca a molta neve.

Quota neve (mslm)	Nord	Sud
	1200 - 1300	1300

Altezza Neve (cm)	Neve al suolo	Neve Fresca	Quota (mslm)
	088	000	1840
	028	000	1550

VALANGHE OSSERVATE: Nessuna valanga.

PREVISIONI 03/02/2026

GRADO DI PERICOLO: MODERATO 2

SITUAZIONE TIPO: neve a debole coesione e vento.

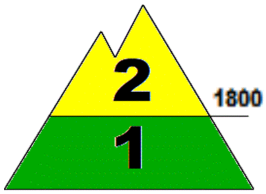

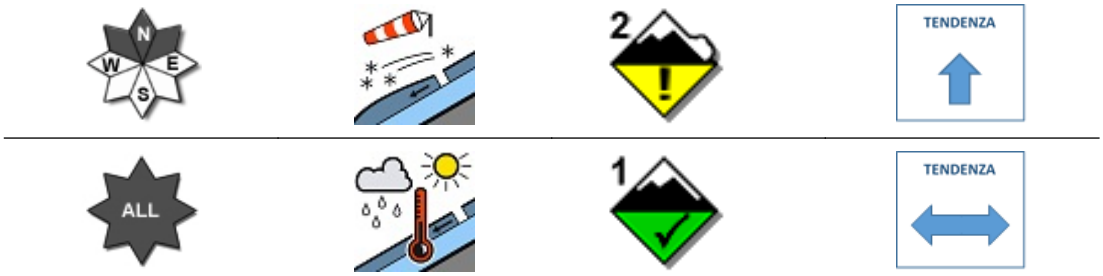

SITUAZIONE TIPO: pioggia su neve.

MANTO NEVOSO: La stabilità del manto nevoso è scarsa su alcuni punti (aree) per versanti settentrionali al di sopra di 1800 mslm, possibili valanghe di dimensioni medie.
La stabilità del manto nevoso è discreta su pochi punti (aree) per tutte le esposizioni al di sotto di 1800 mslm, possibili valanghe di dimensioni piccole.

AVVERTENZE

In considerazione delle avverse condizioni meteorologiche previste , le attività al di fuori delle piste battute e segnalate sono sconsigliate.

SCALA EUROPEA DEL GRADO DI PERICOLO VALANGHE

LEGENDA PROBLEMA

Bollettino realizzato su scala sinottica-regionale (standard EAWS). La sua valutazione non può escludere in alcun modo la necessità di una seria e capace valutazione locale del pericolo (singolo pendio) che può essere anche sensibilmente diverso. Le previsioni meteorologiche sono relative all'orario UTC (per l'Italia +1 in inverno e +2 in estate).

MINISTERO DELLA DIFESA

meteomont
Servizio Nazionale di previsione neve e valanghe

EAWS EUROPEAN AVALANCHE WARNING SERVICES

CARABINIERI

APPENNINO EMILIANO CENTRALE

PREVISIONE METEO

Quota		03/02/2026 h6:00	03/02/2026 h12:00	03/02/2026 h18:00
1000	Venti	07 Nodi da Sud	04 Nodi da S-Ovest	02 Nodi da Sud
	Temperature	+04 °C	+05 °C	+03 °C
	Temp.percepita	1 °C	3 °C	3 °C
2000	Venti	28 Nodi da Sud	18 Nodi da S-Ovest	07 Nodi da Sud
	Temperature	+01 °C	-01 °C	-02 °C
	Temp.percepita	-7 °C	-8 °C	-6 °C
3000	Venti	26 Nodi da S-Ovest	19 Nodi da S-Ovest	09 Nodi da S-Ovest
	Temperature	-04 °C	-06 °C	-08 °C
	Temp.percepita	-13 °C	-15 °C	-15 °C
Zero termico		2200-2400 m.	1700-1900 m.	1700-1900 m.
Fenomeno			—	—
Stato del cielo				

LEGENDA FENOMENI

— Assenza Fenomeni
Nebbia
Foschia
Pioggia debole
Pioggia moderata
Pioggia forte
Temporali
Nevicata debole
Nevicata moderata
Nevicata forte

STATO DEL CIELO

Sereno
Poco nuvoloso
Nuvoloso
Molto nuvoloso
Coperto

Parametri meteonivometrici registrati presso i campi di rilevamento il 02/02/2026.

Località	Comune	Quota (m.s.l.m.)	Altezza neve (cm)	Neve caduta nelle 24 ore (cm)	Temp. Min (°C)	Temp. Max (°C)	Condizioni del tempo
MONTE CUSNA	Villa Minozzo (RE)	1164	0	0	N.P.	N.P.	Assenza di precipitazioni
RIFUGIO CAVONE	Lizzano in Belvedere (BO)	1416	37	0	-5	-2	Assenza di precipitazioni
LAGO DELLA NINFA	Sestola (MO)	1550	29	0	-3	+1	Assenza di precipitazioni
PIANCAVALLARO	Riolunato (MO)	1840	88	0	N.P.	N.P.	Precipitazioni all'orizzonte (pioggia, neve, grandine, temporali) ma non sulla stazione

(*) Rilievi fuori campo

L'INFORMAZIONE E' PREVENZIONE - LEGGI L'ATTUALE GRADO DI PERICOLO VALANGHE!

IL CAPO DEL CENTRO NAZIONALE METEOMONT
(Ten. Col. RFI Emanuela Gini)
FIRMA AUTOGRAFA OMESSA AI SENSI
DELL'ART.3 DEL D.LGS N.39/1993

Bollettino realizzato su scala sinottica-regionale (standard EAWS). La sua valutazione non può escludere in alcun modo la necessità di una seria e capace valutazione locale del pericolo (singolo pendio) che può essere anche sensibilmente diverso. Le previsioni meteorologiche sono relative all'orario UTC (per l'Italia +1 in inverno e +2 in estate).