APPENNINO UMBRO-MARCHIGIANO SETTENTRIONALE

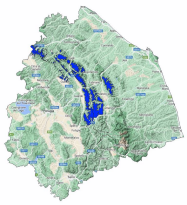

Bollettino Valanghe N. 145/2026 del 03/02/2026 ore 14.00
Validità 48 ore prossima emissione 04/02/2026

A cura del Servizio METEOMONT dell'ARMA dei CARABINIERI
In collaborazione con Servizio Meteorologico dell'Aeronautica militare

SITUAZIONE alle 14:00 del 03/02/2026

SITUAZIONE TIPO: nessuna situazione tipo evidente.

Quota neve (mslm)	Nord	Sud
	1400 - 1500	1500

Altezza Neve (cm)	Neve al suolo	Neve Fresca	Quota (mslm)
	00 -16	000	1450

VALANGHE OSSERVATE: Nessuna valanga.

PREVISIONI 04/02/2026

GRADO DI PERICOLO: DEBOLE 1

SITUAZIONE TIPO: nessuna situazione tipo evidente.



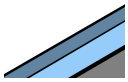

MANTO NEVOSO: La stabilità del manto nevoso è discreta su pochi punti (aree) per isolati pendii, possibili valanghe di dimensioni piccole.

AVVERTENZE

Meteomont ricorda ARTVA, pala e sonda sempre al seguito.

SCALA EUROPEA DEL GRADO DI PERICOLO VALANGHE

LEGENDA PROBLEMA

Bollettino realizzato su scala sinottica-regionale (standard EAWS). La sua valutazione non può escludere in alcun modo la necessità di una seria e capace valutazione locale del pericolo (singolo pendio) che può essere anche sensibilmente diverso. Le previsioni meteorologiche sono relative all'orario UTC (per l'Italia +1 in inverno e +2 in estate).

MINISTERO DELLA DIFESA

meteomont
Servizio Nazionale di previsione neve e valanghe

EAWS EUROPEAN AVALANCHE WARNING SERVICES

CARABINIERI

In collaborazione con: MARCHE

APPENNINO UMBRO-MARCHIGIANO SETTENTRIONALE

PREVISIONE METEO

Quota		04/02/2026 h6:00	04/02/2026 h12:00	04/02/2026 h18:00
1000	Venti	08 Nodi da S-Est	15 Nodi da Sud	08 Nodi da S-Ovest
	Temperature	+06 °C	+06 °C	+04 °C
	Temp.percepita	3 °C	2 °C	1 °C
2000	Venti	21 Nodi da Sud	15 Nodi da Sud	12 Nodi da S-Ovest
	Temperature	-01 °C	-01 °C	-02 °C
	Temp.percepita	-9 °C	-8 °C	-8 °C
3000	Venti	23 Nodi da Sud	16 Nodi da Sud	08 Nodi da S-Ovest
	Temperature	-05 °C	-07 °C	-04 °C
	Temp.percepita	-14 °C	-16 °C	-9 °C
Zero termico		1700-1900 m.	1800-2000 m.	1600-1800 m.
Fenomeno				—
Stato del cielo				

LEGENDA FENOMENI

— Assenza Fenomeni · Nebbia · Foschia · Pioggia debole · Pioggia moderata · Pioggia forte · Temporali

Nevicata debole · Nevicata moderata · Nevicata forte

STATO DEL CIELO

Sereno · Poco nuvoloso · Nuvoloso · Molto nuvoloso · Coperto

Parametri meteonivometrici registrati presso i campi di rilevamento il 03/02/2026.

Località	Comune	Quota (m.s.l.m.)	Altezza neve (cm)	Neve caduta nelle 24 ore (cm)	Temp. Min (°C)	Temp. Max (°C)	Condizioni del tempo
MONTE NERONE	Apecchio (PU)	1400	0	0	-4	+2	Nebbia con cielo non visibile
VALSORDA	Gualdo Tadino (PG)	1005	0	0	+4	+6	Assenza di precipitazioni
MONTE ACUTO	Frontone (PU)	1450	16	0	-1	+2	Pioggia debole intermittente

(*) Rilievi fuori campo

L'INFORMAZIONE E' PREVENZIONE - LEGGI L'ATTUALE GRADO DI PERICOLO VALANGHE!

IL CAPO DEL CENTRO NAZIONALE METEOMONT
(Ten. Col. RFI Emanuela Gini)
FIRMA AUTOGRAFA OMESSA AI SENSI
DELL'ART.3 DEL D.LGS N.39/1993