MINISTERO DELLA DIFESA

meteomont Servizio Nazionale di previsione neve e valanghe

EAWS EUROPEAN AVALANCHE WARNING SERVICES

CARABINIERI

In collaborazione con: MARCHE

APPENNINO UMBRO-MARCHIG. MERID. - MONTI SIBILLINI

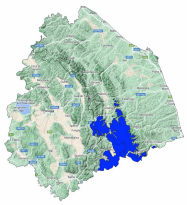

Bollettino Valanghe N. 288/2026 del 03/02/2026 ore 14.00
Validità 48 ore prossima emissione 04/02/2026

A cura del Servizio METEOMONT dell'ARMA dei CARABINIERI
In collaborazione con Servizio Meteorologico dell'Aeronautica militare

SITUAZIONE alle 14:00 del 03/02/2026

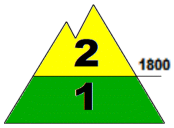

SITUAZIONE TIPO: passaggio da poca a molta neve.



SITUAZIONE TIPO: situazione primaverile.

Quota neve (mslm)	Nord	Sud
	1400 - 1500	1500 - 1600

Altezza Neve (cm)	Neve al suolo	Neve Fresca	Quota (mslm)
	80-120	000	2100
	20 -30	000	1700

VALANGHE OSSERVATE: Nessuna valanga.

PREVISIONI 04/02/2026

GRADO DI PERICOLO: MODERATO 2

SITUAZIONE TIPO: passaggio da poca a molta neve.

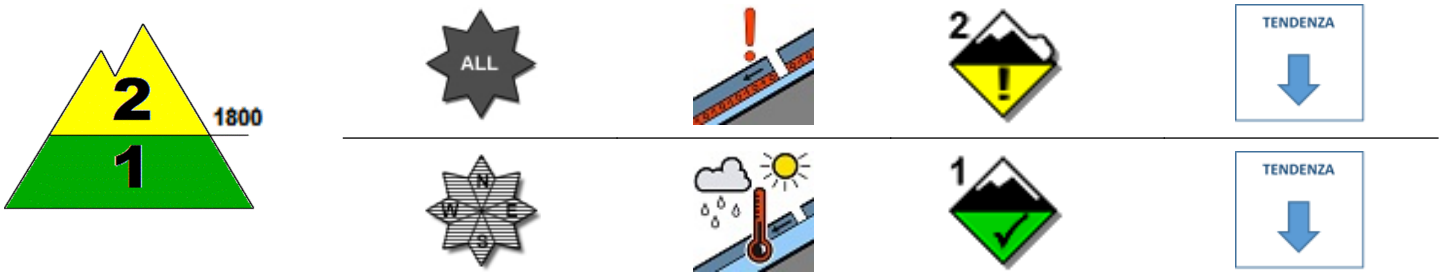

SITUAZIONE TIPO: situazione primaverile.

MANTO NEVOSO: La stabilità del manto nevoso è discreta su alcuni punti (aree) per tutte le esposizioni al di sopra di 1800 mslm, possibili valanghe di dimensioni medie.
La stabilità del manto nevoso è discreta su pochi punti (aree) per isolati pendii al di sotto di 1800 mslm, possibili valanghe di dimensioni piccole.

AVVERTENZE

Meteomont ricorda ARTVA, pala e sonda sempre al seguito.

SCALA EUROPEA DEL GRADO DI PERICOLO VALANGHE

LEGENDA PROBLEMA

Bollettino realizzato su scala sinottica-regionale (standard EAWS). La sua valutazione non può escludere in alcun modo la necessità di una seria e capace valutazione locale del pericolo (singolo pendio) che può essere anche sensibilmente diverso. Le previsioni meteorologiche sono relative all'orario UTC (per l'Italia +1 in inverno e +2 in estate).

MINISTERO DELLA DIFESA

meteomont Servizio Nazionale di previsione neve e valanghe

EAWS EUROPEAN AVALANCHE WARNING SERVICES

CARABINIERI

In collaborazione con: MARCHE

APPENNINO UMBRO-MARCHIG. MERID. - MONTI SIBILLINI

PREVISIONE METEO

Quota		04/02/2026 h6:00	04/02/2026 h12:00	04/02/2026 h18:00
1000	Venti	04 Nodi da Sud	03 Nodi da Sud	04 Nodi da Ovest
	Temperature	+03 °C	+04 °C	+02 °C
	Temp.percepita	1 °C	3 °C	-0 °C
2000	Venti	15 Nodi da Sud	09 Nodi da Sud	10 Nodi da Ovest
	Temperature	+00 °C	+00 °C	-02 °C
	Temp.percepita	-6 °C	-5 °C	-8 °C
3000	Venti	25 Nodi da Sud	10 Nodi da Sud	10 Nodi da Ovest
	Temperature	-04 °C	-06 °C	-05 °C
	Temp.percepita	-13 °C	-13 °C	-11 °C
Zero termico		1900-2100 m.	1900-2100 m.	1600-1800 m.
Fenomeno		—		
Stato del cielo				

LEGENDA FENOMENI

Assenza Fenomeni — Nebbia — Foschia — Pioggia debole — Pioggia moderata — Pioggia forte — Temporali

Nevicata debole — Nevicata moderata — Nevicata forte

STATO DEL CIELO

Sereno — Poco nuvoloso — Nuvoloso — Molto nuvoloso — Coperto

Parametri meteonivometrici registrati presso i campi di rilevamento il 03/02/2026.

Località	Comune	Quota (m.s.l.m.)	Altezza neve (cm)	Neve caduta nelle 24 ore (cm)	Temp. Min (°C)	Temp. Max (°C)	Condizioni del tempo
FORCA DI GUALDO	Castelsantangelo sul Nera (MC)	1496	30	0	+1	+5	Assenza di precipitazioni
LA VALLETTA	Bolognola (MC)	1352	2	0	+2	+7	Assenza di precipitazioni
PARCO GUARNIERI	Montemonaco (AP)	980	0	0	-1	+9	Assenza di precipitazioni
FRONTIGNANO *	Ussita (MC)	1696	20	0	-2	+7	Assenza di precipitazioni
MONTE PRATA *	Castelsantangelo sul Nera (MC)	1708	46	0	N.P.	N.P.	Assenza di precipitazioni

(*) Rilievi fuori campo

L'INFORMAZIONE E' PREVENZIONE - LEGGI L'ATTUALE GRADO DI PERICOLO VALANGHE!

IL CAPO DEL CENTRO NAZIONALE METEOMONT
(Ten. Col. RFI Emanuela Gini)
FIRMA AUTOGRAFA OMESSA AI SENSI
DELL'ART.3 DEL D.LGS N.39/1993

Bollettino realizzato su scala sinottica-regionale (standard EAWS). La sua valutazione non può escludere in alcun modo la necessità di una seria e capace valutazione locale del pericolo (singolo pendio) che può essere anche sensibilmente diverso. Le previsioni meteorologiche sono relative all'orario UTC (per l'Italia +1 in inverno e +2 in estate).