MINISTERO DELLA DIFESA

meteomont
Servizio Nazionale di previsione neve e valanghe

EAWS EUROPEAN AVALANCHE WARNING SERVICES

CARABINIERI

GRAN SASSO EST - LAGA EST

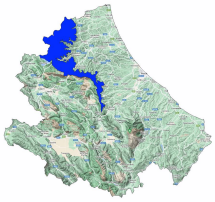

Bollettino Valanghe N. 322/2026 del 02/02/2026 ore 14.00
Validità 48 ore prossima emissione 03/02/2026

A cura del Servizio METEOMONT dell'ARMA dei CARABINIERI
In collaborazione con Servizio Meteorologico dell'Aeronautica militare

SITUAZIONE alle 14:00 del 02/02/2026

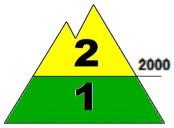

SITUAZIONE TIPO: neve a debole coesione e vento.



SITUAZIONE TIPO: situazione primaverile.

Quota neve (mslm)	Nord	Sud
	1100 - 1400	1100 - 1500

Altezza Neve (cm)	Neve al suolo	Neve Fresca	Quota (mslm)
	034	000	1380
	007	000	1349

VALANGHE OSSERVATE: Nessuna valanga.

PREVISIONI 03/02/2026

GRADO DI PERICOLO: MODERATO 2

SITUAZIONE TIPO: passaggio da poca a molta neve.

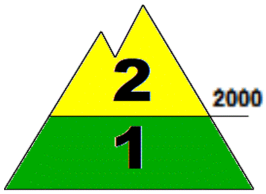

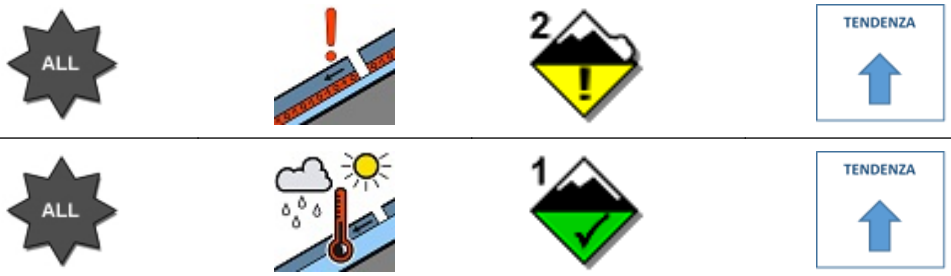

SITUAZIONE TIPO: situazione primaverile.

MANTO NEVOSO: La stabilità del manto nevoso è scarsa su pochi punti (aree) per tutte le esposizioni al di sopra di 2000 mslm, possibili valanghe di dimensioni grandi.
La stabilità del manto nevoso è discreta su pochi punti (aree) per tutte le esposizioni al di sotto di 2000 mslm, possibili valanghe di dimensioni medie.

AVVERTENZE

Attenzione alla presenza di accumuli eolici di difficile individuazione.

SCALA EUROPEA DEL GRADO DI PERICOLO VALANGHE

5 - MOLTO FORTE | 4 - FORTE | 3 - MARCATO | 2 - MODERATO | 1 - DEBOLE | NO NEVE | NO INFO

LEGENDA PROBLEMA

NEVE FRESCA | LASTRONI DA VENTO | STRATI DEBOLI PERSISTENTI | NEVE BAGNATA | SLITTAMENTO | CORNICI | NESSUN PROBLEMA VALANGHIVO EVIDENTE | NO_INFO

Bollettino realizzato su scala sinottica-regionale (standard EAWS). La sua valutazione non può escludere in alcun modo la necessità di una seria e capace valutazione locale del pericolo (singolo pendio) che può essere anche sensibilmente diverso. Le previsioni meteorologiche sono relative all'orario UTC (per l'Italia +1 in inverno e +2 in estate).

MINISTERO DELLA DIFESA

meteomont
Servizio Nazionale di previsione neve e valanghe

EAWS EUROPEAN AVALANCHE WARNING SERVICES

CARABINIERI

GRAN SASSO EST - LAGA EST

PREVISIONE METEO

Quota		03/02/2026 h6:00	03/02/2026 h12:00	03/02/2026 h18:00
1000	Venti	05 Nodi da S-Ovest	05 Nodi da S-Ovest	06 Nodi da Sud
	Temperature	+03 °C	+05 °C	+04 °C
	Temp.percepita	0 °C	3 °C	1 °C
2000	Venti	18 Nodi da S-Ovest	18 Nodi da Sud	21 Nodi da S-Ovest
	Temperature	+01 °C	+01 °C	+01 °C
	Temp.percepita	-5 °C	-5 °C	-6 °C
3000	Venti	19 Nodi da S-Ovest	20 Nodi da S-Ovest	22 Nodi da S-Ovest
	Temperature	-03 °C	-03 °C	-04 °C
	Temp.percepita	-11 °C	-11 °C	-13 °C
Zero termico		2200-2400 m.	2200-2400 m.	2100-2300 m.
Fenomeno		—	—	
Stato del cielo				

LEGENDA FENOMENI

Assenza Fenomeni · Nebbia · Foschia · Pioggia debole · Pioggia moderata · Pioggia forte · Temporali

Nevicata debole · Nevicata moderata · Nevicata forte

STATO DEL CIELO

Sereno · Poco nuvoloso · Nuvoloso · Molto nuvoloso · Coperto

Parametri meteonivometrici registrati presso i campi di rilevamento il 02/02/2026.

Località	Comune	Quota (m.s.l.m.)	Altezza neve (cm)	Neve caduta nelle 24 ore (cm)	Temp. Min (°C)	Temp. Max (°C)	Condizioni del tempo
FAVACCHIOLE	Crognaleto (TE)	1016	0	0	-3	+4	Assenza di precipitazioni
PRATO SELVA	Fano Adriano (TE)	1355	17	N.P.	N.P.	N.P.	Assenza di precipitazioni
RIGOPIANO	Farindola (PE)	1135	0	0	-6	+4	Assenza di precipitazioni
PIANO SAN PIETRO	Isola del Gran Sasso d'Italia (TE)	950	0	0	N.P.	N.P.	Assenza di precipitazioni
PRATI DI TIVO	Pietracamela (TE)	1380	34	0	-6	+4	Assenza di precipitazioni
CEPPO	Rocca Santa Maria (TE)	1349	7	0	-4	+2	Assenza di precipitazioni
SAN PAOLO	Acquasanta Terme (AP)	960	0	0	-4	+10	Assenza di precipitazioni
COLLE SAN GIACOMO	Civitella del Tronto (TE)	1075	0	0	-3	+6	Assenza di precipitazioni

(*) Rilievi fuori campo

L'INFORMAZIONE E' PREVENZIONE - LEGGI L'ATTUALE GRADO DI PERICOLO VALANGHE!

IL CAPO DEL CENTRO NAZIONALE METEOMONT
(Ten. Col. RFI Emanuela Gini)
FIRMA AUTOGRAFA OMESSA AI SENSI
DELL'ART.3 DEL D.LGS N.39/1993

Bollettino realizzato su scala sinottica-regionale (standard EAWS). La sua valutazione non può escludere in alcun modo la necessità di una seria e capace valutazione locale del pericolo (singolo pendio) che può essere anche sensibilmente diverso. Le previsioni meteorologiche sono relative all'orario UTC (per l'Italia +1 in inverno e +2 in estate).