MINISTERO DELLA DIFESA

meteomont Servizio Nazionale di previsione neve e valanghe

EAWS EUROPEAN AVALANCHE WARNING SERVICES

CARABINIERI

TERMINILLO MONTI REATINI E LAGA OVEST

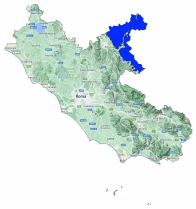

Bollettino Valanghe N. 276/2026 del 03/02/2026 ore 14.00
Validità 48 ore prossima emissione 04/02/2026

A cura del Servizio METEOMONT dell'ARMA dei CARABINIERI
In collaborazione con Servizio Meteorologico dell'Aeronautica militare

SITUAZIONE alle 14:00 del 03/02/2026

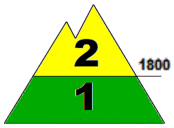

SITUAZIONE TIPO: neve a debole coesione e vento.



SITUAZIONE TIPO: pioggia su neve.

Quota neve (mslm)	Nord	Sud
	1100 - 1300	1300 - 1400

Altezza Neve (cm)	Neve al suolo	Neve Fresca	Quota (mslm)
	140	000	1825
	024	000	1350

VALANGHE OSSERVATE: Nessuna valanga.

PREVISIONI 04/02/2026

GRADO DI PERICOLO: MODERATO 2

SITUAZIONE TIPO: neve a debole coesione e vento.

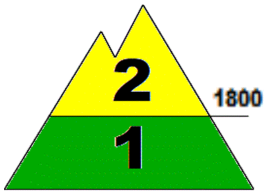

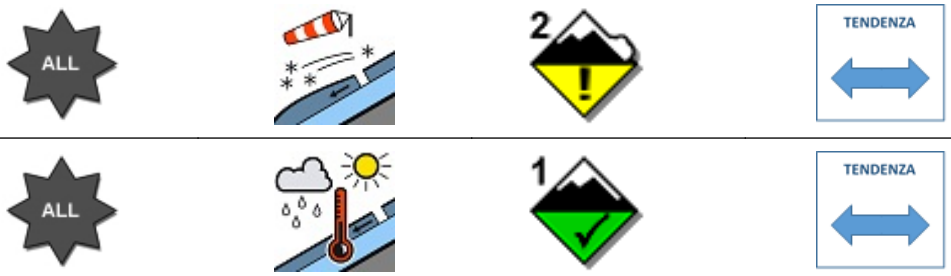

SITUAZIONE TIPO: pioggia su neve.

MANTO NEVOSO: La stabilità del manto nevoso è scarsa su alcuni punti (aree) per tutte le esposizioni al di sopra di 1800 mslm, possibili valanghe di dimensioni medie.
La stabilità del manto nevoso è discreta su alcuni punti (aree) per tutte le esposizioni al di sotto di 1800 mslm, possibili valanghe di dimensioni piccole.

AVVERTENZE

In considerazione delle avverse condizioni meteorologiche previste, le attività al di fuori delle piste battute e segnalate sono limitate. Se effettuate, richiedono ottime capacità di valutazione del pericolo locale.

SCALA EUROPEA DEL GRADO DI PERICOLO VALANGHE

LEGENDA PROBLEMA

Bollettino realizzato su scala sinottica-regionale (standard EAWS). La sua valutazione non può escludere in alcun modo la necessità di una seria e capace valutazione locale del pericolo (singolo pendio) che può essere anche sensibilmente diverso. Le previsioni meteorologiche sono relative all'orario UTC (per l'Italia +1 in inverno e +2 in estate).

MINISTERO DELLA DIFESA

meteomont
Servizio Nazionale di previsione neve e valanghe

EAWS EUROPEAN AVALANCHE WARNING SERVICES

CARABINIERI

TERMINILLO MONTI REATINI E LAGA OVEST

PREVISIONE METEO

Quota		04/02/2026 h6:00	04/02/2026 h12:00	04/02/2026 h18:00
1000	Venti	07 Nodi da Sud	05 Nodi da Sud	03 Nodi da S-Ovest
	Temperature	+03 °C	+03 °C	+01 °C
	Temp.percepita	-0 °C	0 °C	-1 °C
2000	Venti	21 Nodi da Sud	14 Nodi da Sud	09 Nodi da S-Ovest
	Temperature	-01 °C	-01 °C	-03 °C
	Temp.percepita	-9 °C	-7 °C	-8 °C
3000	Venti	24 Nodi da Sud	11 Nodi da S-Ovest	11 Nodi da Ovest
	Temperature	-04 °C	-06 °C	-06 °C
	Temp.percepita	-13 °C	-13 °C	-13 °C
Zero termico		1800-2000 m.	1700-1900 m.	1500-1700 m.
Fenomeno		—		—
Stato del cielo				

LEGENDA FENOMENI

— Assenza Fenomeni · Nebbia · Foschia · Pioggia debole · Pioggia moderata · Pioggia forte · Temporali

Nevicata debole · Nevicata moderata · Nevicata forte

STATO DEL CIELO

Sereno · Poco nuvoloso · Nuvoloso · Molto nuvoloso · Coperto

Parametri meteonivometrici registrati presso i campi di rilevamento il 03/02/2026.

Località	Comune	Quota (m.s.l.m.)	Altezza neve (cm)	Neve caduta nelle 24 ore (cm)	Temp. Min (°C)	Temp. Max (°C)	Condizioni del tempo
PESCHIERE	Amatrice (RI)	1270	0	0	-3	+9	Assenza di precipitazioni
M. CAIDURO	Cittareale (RI)	1300	12	0	0	+12	Assenza di precipitazioni
VALLONINA	Leonessa (RI)	1350	24	0	-5	+8	Pioggia debole intermittente
RIALTO *	Micigliano (RI)	1700	100	0	-1	+2	Pioggia debole intermittente

(*) Rilievi fuori campo

L'INFORMAZIONE E' PREVENZIONE - LEGGI L'ATTUALE GRADO DI PERICOLO VALANGHE!

IL CAPO DEL CENTRO NAZIONALE METEOMONT
(Ten. Col. RFI Emanuela Gini)
FIRMA AUTOGRAFA OMESSA AI SENSI
DELL'ART.3 DEL D.LGS N.39/1993

Bollettino realizzato su scala sinottica-regionale (standard EAWS). La sua valutazione non può escludere in alcun modo la necessità di una seria e capace valutazione locale del pericolo (singolo pendio) che può essere anche sensibilmente diverso. Le previsioni meteorologiche sono relative all'orario UTC (per l'Italia +1 in inverno e +2 in estate).