MINISTERO DELLA DIFESA

meteomont
Servizio Nazionale di previsione neve e valanghe

EAWS EUROPEAN AVALANCHE WARNING SERVICES

CARABINIERI

AERONAUTICA MILITARE SERVIZIO METEOROLOGICO

APPENNINO LUCANO

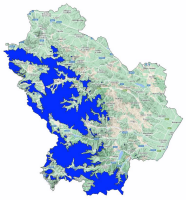

Bollettino Valanghe N. 231/2026 del 02/02/2026 ore 14.00
Validità 48 ore prossima emissione 03/02/2026

A cura del Servizio METEOMONT dell'ARMA dei CARABINIERI
In collaborazione con Servizio Meteorologico dell'Aeronautica militare

SITUAZIONE alle 14:00 del 02/02/2026

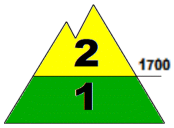

SITUAZIONE TIPO: neve a debole coesione e vento.



SITUAZIONE TIPO: situazione primaverile.

Quota neve (mslm)	Nord	Sud
	1400 - 1500	1500 - 1600

Altezza Neve (cm)	Neve al suolo	Neve Fresca	Quota (mslm)
	120	000	1800
	022	000	1532

VALANGHE OSSERVATE: Nessuna valanga.

PREVISIONI 03/02/2026

GRADO DI PERICOLO: MODERATO 2

SITUAZIONE TIPO: neve a debole coesione e vento.

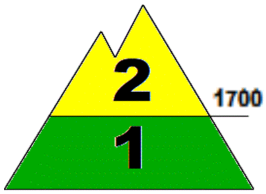

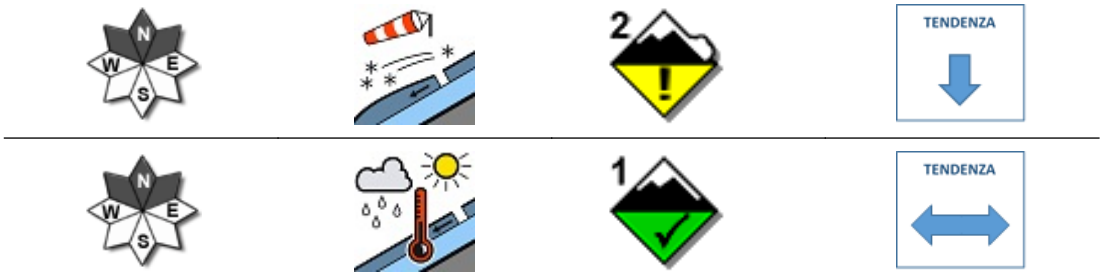

SITUAZIONE TIPO: situazione primaverile.

MANTO NEVOSO: La stabilità del manto nevoso è discreta su alcuni punti (aree) per versanti settentrionali al di sopra di 1700 mslm, possibili valanghe di dimensioni medie.
La stabilità del manto nevoso è discreta su alcuni punti (aree) per versanti settentrionali al di sotto di 1700 mslm, possibili valanghe di dimensioni piccole.

AVVERTENZE

Il rialzo termico diurno richiede un'attenta valutazione temporale dell'escursione che eviti l'attraversamento di pendii ripidi nelle ore più calde della giornata.

SCALA EUROPEA DEL GRADO DI PERICOLO VALANGHE

LEGENDA PROBLEMA

Bollettino realizzato su scala sinottica-regionale (standard EAWS). La sua valutazione non può escludere in alcun modo la necessità di una seria e capace valutazione locale del pericolo (singolo pendio) che può essere anche sensibilmente diverso. Le previsioni meteorologiche sono relative all'orario UTC (per l'Italia +1 in inverno e +2 in estate).

APPENNINO LUCANO

PREVISIONE METEO

Quota		03/02/2026 h6:00	03/02/2026 h12:00	03/02/2026 h18:00
1000	Venti	07 Nodi da S-Est	07 Nodi da S-Est	06 Nodi da S-Est
	Temperature	+07 °C	+08 °C	+09 °C
	Temp.percepita	5 °C	6 °C	7 °C
2000	Venti	09 Nodi da S-Ovest	14 Nodi da Sud	13 Nodi da S-Ovest
	Temperature	+03 °C	+04 °C	+04 °C
	Temp.percepita	-1 °C	-1 °C	-1 °C
3000	Venti	11 Nodi da Ovest	16 Nodi da S-Ovest	17 Nodi da S-Ovest
	Temperature	-01 °C	-01 °C	-02 °C
	Temp.percepita	-7 °C	-8 °C	-9 °C
Zero termico		2600-2800 m.	2800-3000 m.	2600-2800 m.
Fenomeno		—	—	—
Stato del cielo				

LEGENDA FENOMENI

— Assenza Fenomeni · Nebbia · Foschia · Pioggia debole · Pioggia moderata · Pioggia forte · Temporali

Nevicata debole · Nevicata moderata · Nevicata forte

STATO DEL CIELO

Sereno · Poco nuvoloso · Nuvoloso · Molto nuvoloso · Coperto

Parametri meteonivometrici registrati presso i campi di rilevamento il 02/02/2026.

Località	Comune	Quota (m.s.l.m.)	Altezza neve (cm)	Neve caduta nelle 24 ore (cm)	Temp. Min (°C)	Temp. Max (°C)	Condizioni del tempo
LAUDEMIO	Lagonegro (PZ)	1532	22	0	0	+1	Assenza di precipitazioni
PIANO IMPERATORE	Marsicovetere (PZ)	1560	20	0	-2	+1	Assenza di precipitazioni
PEDARRETO	Rotonda (PZ)	1380	3	0	-1	+7	Assenza di precipitazioni
FORCELLA M.TE PAPA *	Lagonegro (PZ)	1800	120	0	N.P.	N.P.	Assenza di precipitazioni

(*) Rilievi fuori campo

L'INFORMAZIONE E' PREVENZIONE - LEGGI L'ATTUALE GRADO DI PERICOLO VALANGHE!

IL CAPO DEL CENTRO NAZIONALE METEOMONT
(Ten. Col. RFI Emanuela Gini)
FIRMA AUTOGRAFA OMESSA AI SENSI
DELL'ART.3 DEL D.LGS N.39/1993