APPENNINO CALABRO

Bollettino Valanghe N. 218/2026 del 03/02/2026 ore 14.00
Validità 48 ore prossima emissione 04/02/2026

A cura del Servizio METEOMONT dell'ARMA dei CARABINIERI
In collaborazione con Servizio Meteorologico dell'Aeronautica militare

SITUAZIONE alle 14:00 del 03/02/2026

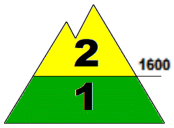

SITUAZIONE TIPO: neve a debole coesione e vento.



SITUAZIONE TIPO: situazione primaverile.

Quota neve (mslm)	Nord	Sud
	1300 - 1400	1400 - 1600

Altezza Neve (cm)	Neve al suolo	Neve Fresca	Quota (mslm)
	045	000	1600
	002	000	1367

VALANGHE OSSERVATE: Nessuna valanga.

PREVISIONI 04/02/2026

GRADO DI PERICOLO: MODERATO 2

SITUAZIONE TIPO: pioggia su neve.

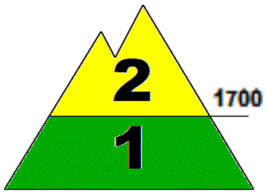

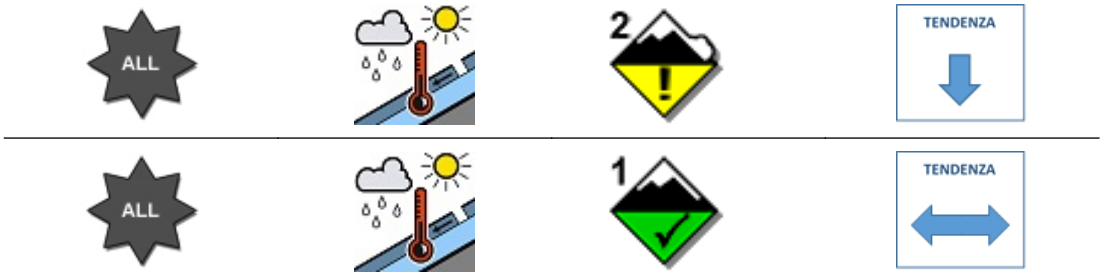

SITUAZIONE TIPO: pioggia su neve.

MANTO NEVOSO: La stabilità del manto nevoso è discreta su alcuni punti (aree) per tutte le esposizioni al di sopra di 1700 mslm, possibili valanghe di dimensioni medie.
La stabilità del manto nevoso è discreta su pochi punti (aree) per tutte le esposizioni al di sotto di 1700 mslm, possibili valanghe di dimensioni piccole.

AVVERTENZE

In considerazione dei recenti apporti di neve fresca, è richiesta una buona valutazione locale della stabilità ed individuazione dell'itinerario.

SCALA EUROPEA DEL GRADO DI PERICOLO VALANGHE

5 - MOLTO FORTE | 4 - FORTE | 3 - MARCATO | 2 - MODERATO | 1 - DEBOLE | NO NEVE | NO INFO

LEGENDA PROBLEMA

NEVE FRESCA | LASTRONI DA VENTO | STRATI DEBOLI PERSISTENTI | NEVE BAGNATA | SLITTAMENTO | CORNICI | NESSUN PROBLEMA VALANGHIVO EVIDENTE | NO_INFO

Bollettino realizzato su scala sinottica-regionale (standard EAWS). La sua valutazione non può escludere in alcun modo la necessità di una seria e capace valutazione locale del pericolo (singolo pendio) che può essere anche sensibilmente diverso. Le previsioni meteorologiche sono relative all'orario UTC (per l'Italia +1 in inverno e +2 in estate).

MINISTERO DELLA DIFESA

meteomont
Servizio Nazionale di previsione neve e valanghe

EAWS EUROPEAN AVALANCHE WARNING SERVICES

CARABINIERI

APPENNINO CALABRO

PREVISIONE METEO

Quota		04/02/2026 h6:00	04/02/2026 h12:00	04/02/2026 h18:00
1000	Venti	11 Nodi da Sud	10 Nodi da Sud	07 Nodi da S-Ovest
	Temperature	+03 °C	+04 °C	+01 °C
	Temp.percepita	-1 °C	0 °C	-3 °C
2000	Venti	26 Nodi da Sud	23 Nodi da Sud	16 Nodi da Ovest
	Temperature	+07 °C	+00 °C	-02 °C
	Temp.percepita	2 °C	-8 °C	-9 °C
3000	Venti	23 Nodi da Sud	26 Nodi da Sud	19 Nodi da S-Ovest
	Temperature	+00 °C	-05 °C	-07 °C
	Temp.percepita	-8 °C	-15 °C	-16 °C
Zero termico		2900-3100 m.	2000-2200 m.	1600-1800 m.
Fenomeno		—		—
Stato del cielo				

LEGENDA FENOMENI

— Assenza Fenomeni · Nebbia · Foschia · Pioggia debole · Pioggia moderata · Pioggia forte · Temporali

Nevicata debole · Nevicata moderata · Nevicata forte

STATO DEL CIELO

Sereno · Poco nuvoloso · Nuvoloso · Molto nuvoloso · Coperto

Parametri meteonivometrici registrati presso i campi di rilevamento il 03/02/2026.

Località	Comune	Quota (m.s.l.m.)	Altezza neve (cm)	Neve caduta nelle 24 ore (cm)	Temp. Min (°C)	Temp. Max (°C)	Condizioni del tempo
BIVIO NARDODIPACE	Mongiana (VV)	1339	0	0	0	+8	Assenza di precipitazioni
GAMBARIE	Santo Stefano in Aspromonte (RC)	1367	2	0	-1	+6	Assenza di precipitazioni
COZZO VARDO	Morano Calabro (CS)	1475	0	0	+0	+8	Assenza di precipitazioni
VALICO DI MONTE SCURO	Celico (CS)	1600	45	0	-2	+9	Assenza di precipitazioni
BUTURO	Albi (CZ)	1530	47	0	-1	+4	Assenza di precipitazioni

(*) Rilievi fuori campo

L'INFORMAZIONE E' PREVENZIONE - LEGGI L'ATTUALE GRADO DI PERICOLO VALANGHE!

IL CAPO DEL CENTRO NAZIONALE METEOMONT
(Ten. Col. RFI Emanuela Gini)
FIRMA AUTOGRAFA OMESSA AI SENSI
DELL'ART.3 DEL D.LGS N.39/1993

Bollettino realizzato su scala sinottica-regionale (standard EAWS). La sua valutazione non può escludere in alcun modo la necessità di una seria e capace valutazione locale del pericolo (singolo pendio) che può essere anche sensibilmente diverso. Le previsioni meteorologiche sono relative all'orario UTC (per l'Italia +1 in inverno e +2 in estate).