Bulletin d'estimation du risque d'avalanche

(valable en dehors des pistes balisées et ouvertes)

MASSIF : Capcir Puymorens

Rédigé le mardi 3 février 2026 à 16h

Estimation des risques pour le : MERCREDI 04 FÉVRIER

MANTEAU ENCORE INSTABLE EN ALTITUDE

3

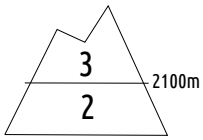

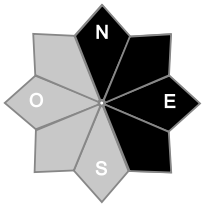

Au-dessus de 2100m indice de risque marqué, plus bas indice limité.

Départs spontanés : Suivant l'altitude, par surcharge due au vent ou par humidification en profondeur

Déclenchements provoqués : Structures de plaques en altitude, plus épaisses dans un large secteur est

Indices de risque : 5 très fort - 4 fort - 3 marqué - 2 limité - 1 faible -- En noir : les pentes les plus dangereuses

Stabilité du manteau neigeux

Situation avalancheuse typique : neige ventée neige humide

Déclenchements provoqués :

* En altitude, au dessus de 2100m, le manteau neigeux reste instable en de nombreuses orientations et des structures de plaques déclenchables parfois par le passage d'un simple randonneur sont en place et continuent de se former, s'empilant parfois les unes sur les autres. Elles sont plus épaisses dans un large secteur nord à sud-est, où elles peuvent occasionner des avalanches moyennes (taille 2), plus rarement grandes (tailles 3). Situées parfois loin des crêtes, leur détection sur le terrain n'est pas toujours aisée. Rester attentif à l'apparition de fissures sous les skis ou à l'émission de 'whoumf'.
* En dessous de 2100m, le manteau neigeux s'est bien humidifié, et a souvent regelé dans la nuit, assurant une bonne cohésion en surface. Le risque de déclencher une avalanche de plaque y est donc plus faible. Un départ ponctuel en neige humide est en revanche possible dans les pentes raides s'humidifiant au fil de la journée (Taille 1 à 2) .

Départs spontanés :

* En altitude, au dessus de 2100m, le transport de neige par le vent pourra entrainer par surcharge le départ spontané de structures de plaques décrites ci-dessus (avalanches de taille petite à moyenne, plus rarement grandes).
* Sous 2000/2100 m dans les pentes raides, en toutes orientations, l'humidification en profondeur du manteau neigeux se poursuivra et des avalanches spontanées avec départ ponctuel ou linéaire pourront localement entrainer l'ensemble de la neige récente, parfois même jusqu'au sol en terrain herbeux ou sur des dalles lisses (Taille 1 à 2, rarement 3). Des fissures et des débuts de reptations peuvent être des signes précurseurs à ces départs qui sans être généralisés, pourront se produire à tout moment.

Qualité de la neige

Enneigement :
Enneigement excellent et excédentaire pour la saison, avec des cumuls importants de neige récente en montagne. Mardi matin, on pourra chausser les skis dès 1100 m en nord et plutôt 1200/1300 m au sud.

État de la neige :
Mardi matin, en dessous de 2100m, on trouvera une neige croutée plus ou moins portante.
Plus haut, la neige est restée froide, mais toujours travaillée par le vent proche des crêtes avec une surface irrégulière et des épaisseurs hétérogènes. On pourra encore trouver de la neige légère et plus agréable à skier dans les combes d'altitude abritées du vent. En journée, la neige va peu évoluer en altitude, mais s'humidifier en dessous de 2100m au soleil ou dans une couche nuageuse.

Aperçu météo pour le mercredi 04 février

	nuit	matin	après-midi	soir
	Plus nuageux, avec encore du vent			
Pluie-Neige				
Iso 0 °C	1 500 m	1 600 m	2 000 m	2 100 m
Vent 2000 m	30 km/h	50 km/h	25 km/h	30 km/h
Vent 3000 m	35 km/h	55 km/h	35 km/h	40 km/h

Épaisseur de neige hors-piste

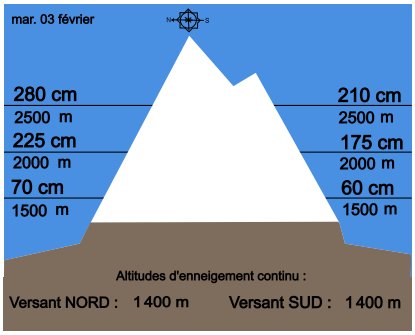

Précipitations à 1800 m

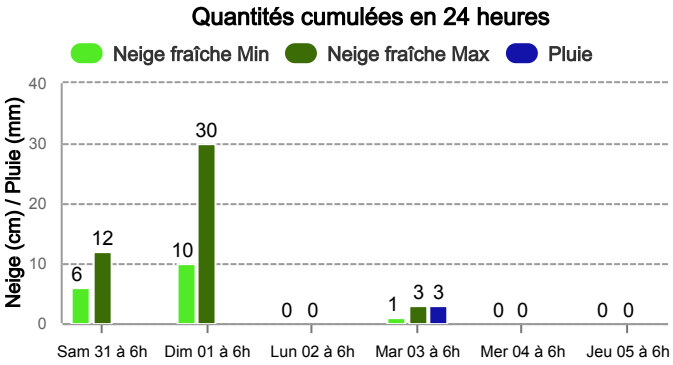

Tendance du jeudi 05 février

3 **Indice de risque marqué**

Maintien d'un risque marqué avec le redoux prévu jeudi

Pour consulter la vigilance en cours, veuillez vous rendre sur le site https://vigilance.meteofrance.fr/fr

Météo-France - 73 avenue de Paris, 94165 Saint-Mandé cedex - Contact : contact@meteo.fr

Rédigé par Météo-France avec la contribution des observateurs du réseau nivo-météorologiques. Partenariat : ANMSM (Maires de Stations de Montagne), DSF (Domaines Skiables de France), ADSP (Directeurs de Pistes et de la Sécurité des Stations de Sports d'Hiver) et autres acteurs de la montagne.

Bulletin neige & avalanches par téléphone au **0 892 68 10 20** Service 0,35 € / min + prix appel

RÉPUBLIQUE FRANÇAISE
Liberté Égalité Fraternité

METEO FRANCE
À VOS CÔTÉS, DANS UN CLIMAT QUI CHANGE

Bulletin d'estimation du risque d'avalanche

(valable en dehors des pistes balisées et ouvertes)

MASSIF : Capcir Puymorens

Rédigé le mardi 3 février 2026 à 16h

Conditions nivo-météo des 7 derniers jours

	mer. 28/01				jeu. 29/01				ven. 30/01				sam. 31/01				dim. 01/02				lun. 02/02				mar. 03/02			
	03h	09h	15h	21h	03h	09h	15h	21h	03h	09h	15h	21h	03h	09h	15h	21h	03h	09h	15h	21h	03h	09h	15h	21h	03h	09h	15h	21h
Météo																												
Vent (km/h)	40	50	50	55	50	50	55	75	80	70	60	40	55	85	80	70	55	35	35	30	60	80	100	65	50	35	40	30
à 3000m	↑	↑	↘	↘	↘	↘	↘	↘	↘	↘	↘	↘	↘	↘	↘	↘	↘	→	→	→	↗	↑	↑	↗	→	↗	↗	↗
Vent (km/h)	25	35	35	35	30	30	40	50	55	45	45	25	35	65	65	50	35	25	20	15	20	50	75	45	35	25	30	25
à 2000m	↑	↑	↘	→	↘	→	→	→	→	→	→	→	→	→	↘	→	↘	→	→	↗	↗	↗	↑	↗	↗	↗	↗	↗

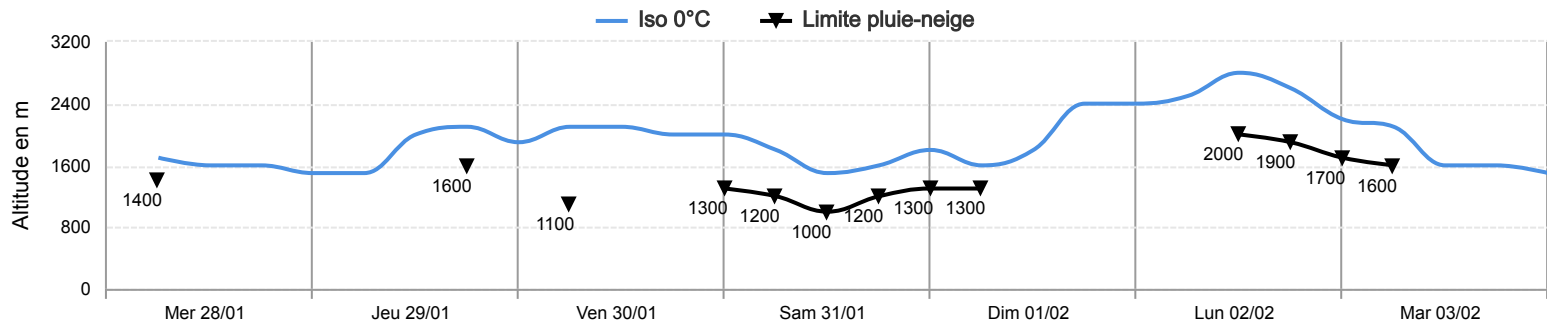

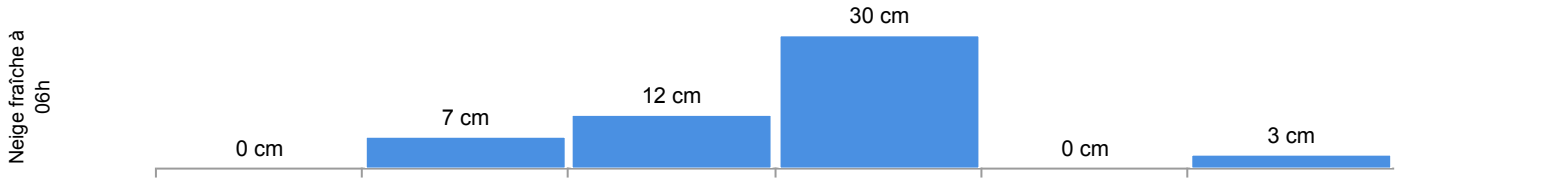

Risque d'avalanche	mer. 28/01	jeu. 29/01	ven. 30/01	sam. 31/01	dim. 01/02	lun. 02/02	mar. 03/02
	3	3	3	3	4	3	3

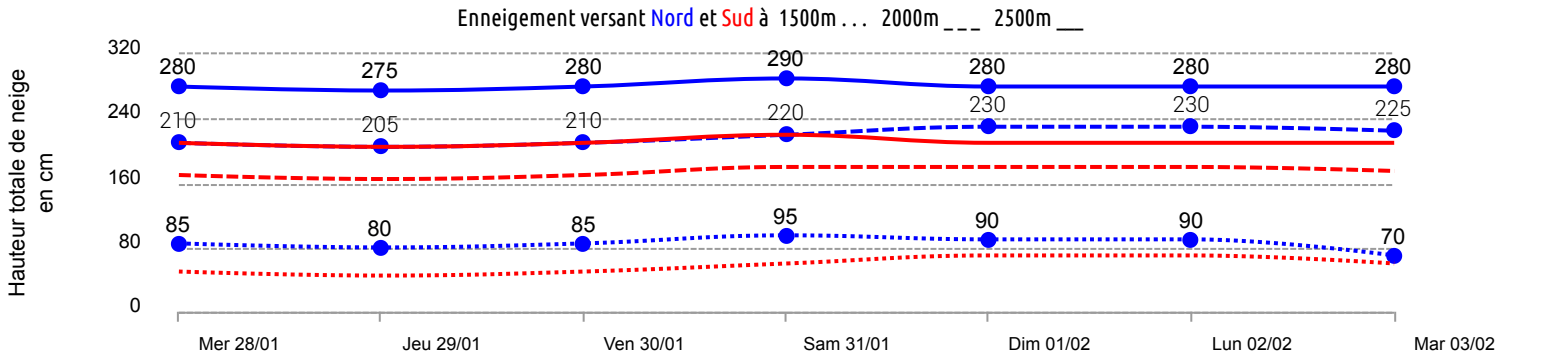

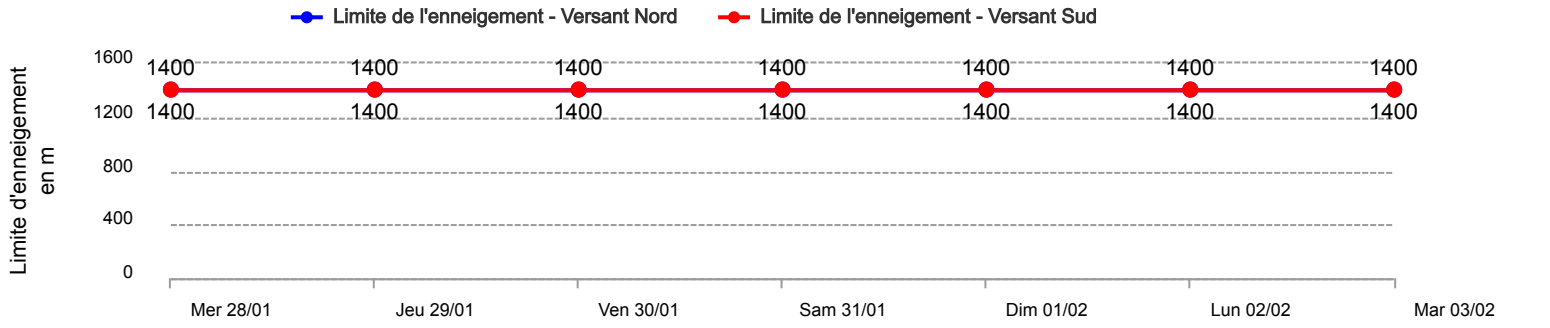

Pour consulter la vigilance en cours, veuillez vous rendre sur le site https://vigilance.meteofrance.fr/fr

Météo-France - 73 avenue de Paris, 94165 Saint-Mandé cedex - Contact : contact@meteo.fr

Bulletin neige & avalanches par téléphone au

0 892 68 10 20 Service 0,35 € / min + prix appel

Rédigé par Météo-France avec la contribution des observateurs du réseau nivo-météorologiques. Partenariat : ANMSM (Maires de Stations de Montagne), DSF (Domaines Skiables de France), ADSP (Directeurs de Pistes et de la Sécurité des Stations de Sports d'Hiver) et autres acteurs de la montagne.