Bulletin d'estimation du risque d'avalanche

(valable en dehors des pistes balisées et ouvertes)

MASSIF : Haut-Var Haut-Verdon

Rédigé le mardi 3 février 2026 à 16h

Estimation des risques pour le : MERCREDI 04 FÉVRIER

NOMBREUSES PLAQUES DANS LA NEIGE FRAICHE, LOCALEMENT VOLUMINEUSES

3

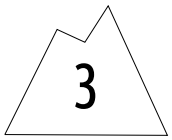

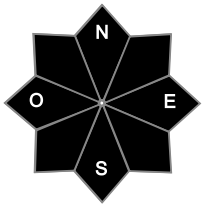

Indice de risque marqué.

Départs spontanés : quelques départs de neige fraîche s'humidifiant en journée.

Déclenchements provoqués : nombreuses plaques dans la neige fraîche, localement volumineuses.

Indices de risque : 5 très fort - 4 fort - 3 marqué - 2 limité - 1 faible -- En noir : les pentes les plus dangereuses

Stabilité du manteau neigeux

Situation avalancheuse typique : neige fraîche couche fragile persistante

Déclenchements provoqués : nombreuses instabilités en place, pouvant être déclenchées à distance dans de nombreuses pentes supérieures à 30 degrés, y compris en forêts. De nombreuses plaques dans la neige fraiche sont en place, possibles en toutes orientations au dessus de 1800 m environ. Elles sont généralement d'aspect friable et difficiles à détecter, sinon durcies par le vent dans les secteurs exposés. Leur déclenchement est possible au passage d'un seul skieur, et elles peuvent provoquer des avalanches de taille souvent moyenne (taille 2).

En versants est, nord et ouest, la présence d'une couche fragile persistante au dessus de 1800/2000 m, peut occasionner des avalanches de plus grande taille (taille 3), emportant une grande partie du manteau neigeux, parfois sur de grandes distances. Toutefois, leur déclenchement est généralement devenu difficile à cause des importantes accumulations de neige des derniers épisodes, qui isolent cette couche en profondeur, mais peut être rendu possible sous une forte contrainte comme le déclenchement d'une première avalanche en surface.

Départs spontanés : quelques départs de neige fraîche s'humidifiant en journée sont possibles. Départs ponctuels en pentes raides, de petite taille.

Qualité de la neige

Enneigement bon voire excédentaire jusqu'à basse altitude pour un début février. Données observées vers 2000 m en fond de vallon : 140 à 150 cm de hauteur totale de neige.

Enneigement skiable dès 1200/1300 m en terrain favorable, mais peu de sous-couche sous 1600 m en général.

État de la neige en surface : couche de neige fraiche atteignant 15/20 cm à partir de 1800 m, localement 30/35 cm. Cette neige est plus lourde sous 1800/2000 m environ, mais encore froide et légère au-dessus, localement travaillée par le vent en altitude dans les secteurs exposés. Corniches et congères parfois volumineuses en place.

Aperçu météo pour le mercredi 04 février

	nuit	matin	après-midi	soir
Pluie-Neige				
Iso 0 °C	1 500 m	1 500 m	1 600 m	1 500 m
Vent 2000 m	← 15 km/h	↖ 20 km/h	↖ 20 km/h	↙ 10 km/h
Vent 3000 m	↖ 25 km/h	↖ 25 km/h	↖ 25 km/h	↘ 15 km/h

Épaisseur de neige hors-piste

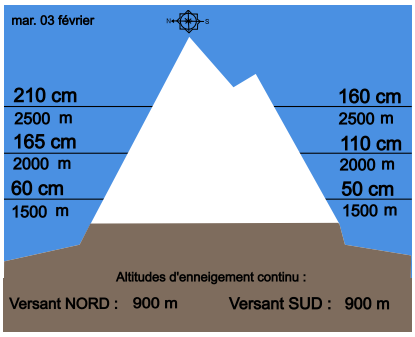

Précipitations à 1800 m

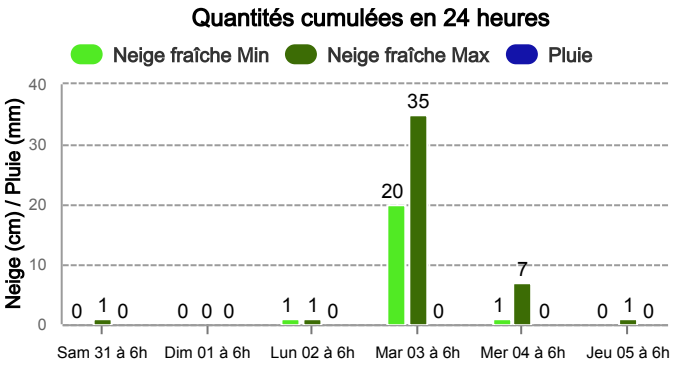

Tendance du jeudi 05 février

3 **Indice de risque marqué**

Risque marqué avec la persistance de plaques dans la neige récente, encore insuffisamment stabilisées.

Pour consulter la vigilance en cours, veuillez vous rendre sur le site https://vigilance.meteofrance.fr/fr

Météo-France - 73 avenue de Paris, 94165 Saint-Mandé cedex - Contact : contact@meteo.fr

Rédigé par Météo-France avec la contribution des observateurs du réseau nivo-météorologiques. Partenariat : ANMSM (Maires de Stations de Montagne), DSF (Domaines Skiables de France), ADSP (Directeurs de Pistes et de la Sécurité des Stations de Sports d'Hiver) et autres acteurs de la montagne.

Bulletin neige & avalanches par téléphone au **0 892 68 10 20** Service 0,35 € / min + prix appel

RÉPUBLIQUE FRANÇAISE
Liberté Égalité Fraternité

METEO FRANCE
À VOS CÔTÉS, DANS UN CLIMAT QUI CHANGE

Bulletin d'estimation du risque d'avalanche

(valable en dehors des pistes balisées et ouvertes)

MASSIF : Haut-Var Haut-Verdon

Rédigé le mardi 3 février 2026 à 16h

Conditions nivo-météo des 7 derniers jours

	mer. 28/01				jeu. 29/01				ven. 30/01				sam. 31/01				dim. 01/02				lun. 02/02				mar. 03/02			
	03h	09h	15h	21h	03h	09h	15h	21h	03h	09h	15h	21h	03h	09h	15h	21h	03h	09h	15h	21h	03h	09h	15h	21h	03h	09h	15h	21h
Météo																												
Vent (km/h)	45	25	5	30	45	40	35	20	45	60	50	20	20	20	20	15	20	15	15	15	20	25	40	65	75	50	35	20
à 3000m																												
Vent (km/h)	15	15	5	25	35	25	25	15	20	30	25	10	15	15	15	15	10	10	15	10	10	10	20	30	35	30	20	15
à 2000m																												

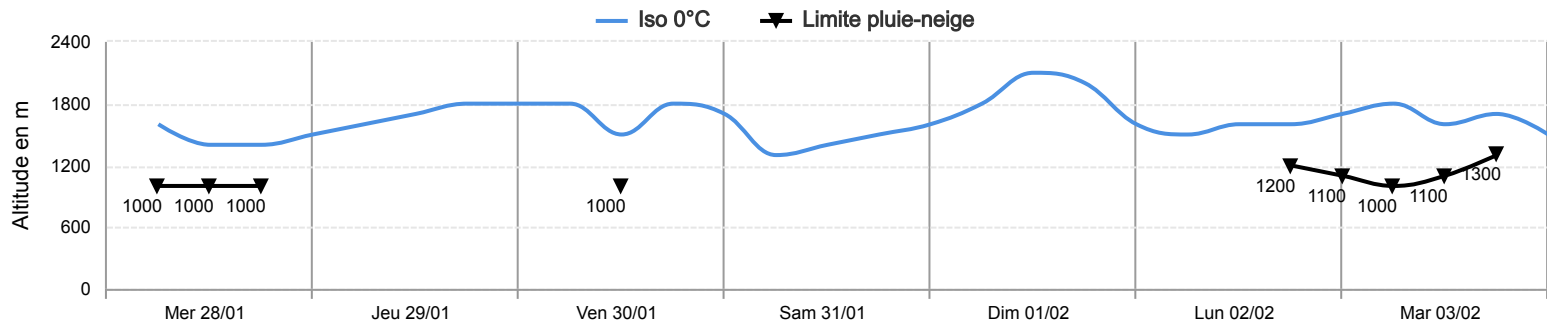

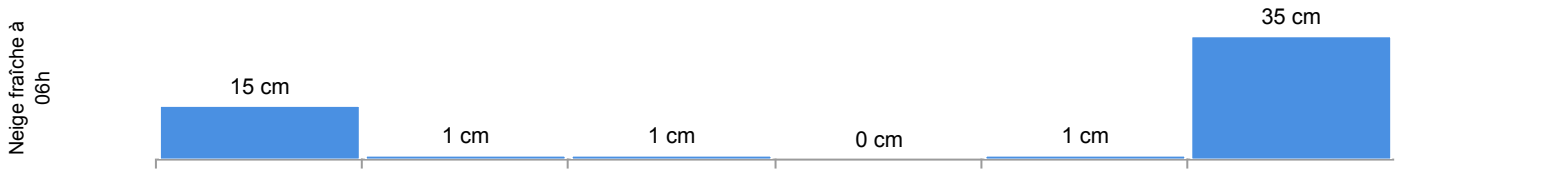

Risque d'avalanche	mer. 28/01	jeu. 29/01	ven. 30/01	sam. 31/01	dim. 01/02	lun. 02/02	mar. 03/02
	4	4	4	3	3	3	4

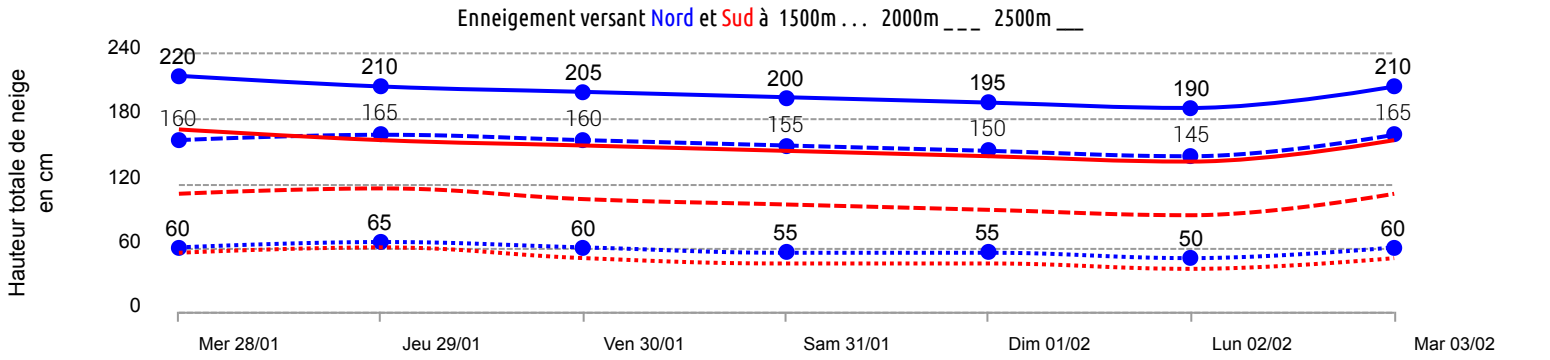

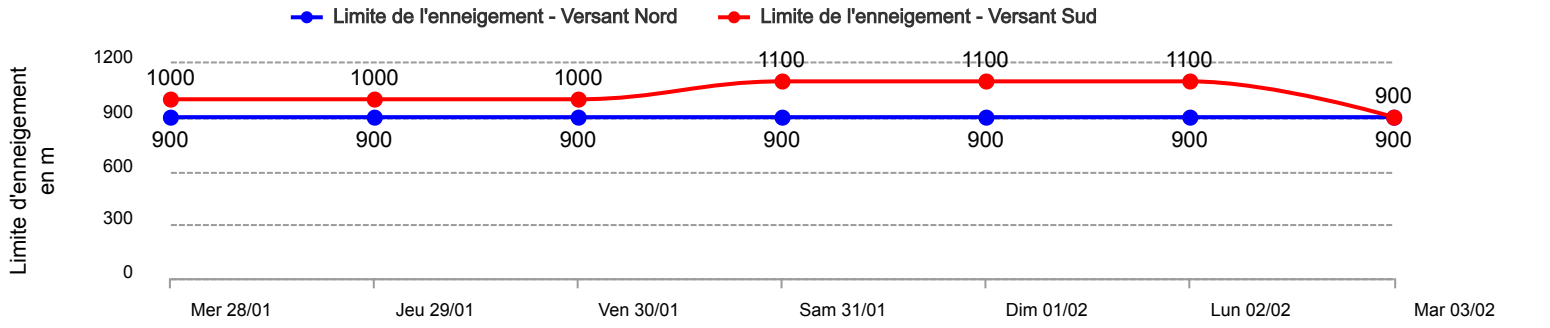

Pour consulter la vigilance en cours, veuillez vous rendre sur le site https://vigilance.meteofrance.fr/fr

Météo-France - 73 avenue de Paris, 94165 Saint-Mandé cedex - Contact : contact@meteo.fr

Rédigé par Météo-France avec la contribution des observateurs du réseau nivo-météorologiques. Partenariat : ANMSM (Maires de Stations de Montagne), DSF (Domaines Skiables de France), ADSP (Directeurs de Pistes et de la Sécurité des Stations de Sports d'Hiver) et autres acteurs de la montagne.

Bulletin neige & avalanches par téléphone au
0 892 68 10 20 Service 0,35 € / min + prix appel