Bulletin d'estimation du risque d'avalanche

(valable en dehors des pistes balisées et ouvertes)

MASSIF : Haute-Bigorre

Rédigé le mardi 3 février 2026 à 16h

Estimation des risques pour le : MERCREDI 04 FÉVRIER

NEIGE VENTÉE EN ALTITUDE, HUMIDIFICATION PROGRESSIVE PLUS BAS.

3

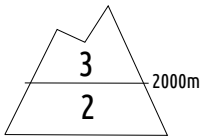

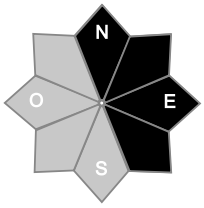

Plaques en altitude.

Indices de risque : 5 très fort - 4 fort - 3 marqué - 2 limité - 1 faible -- En noir : les pentes les plus dangereuses

Au-dessus de 2000m indice de risque marqué, plus bas indice limité.

Départs spontanés : Départs ponctuels en neige ventée et humide, avalanches de fond possibles.

Déclenchements provoqués : Plaques en altitude.

Stabilité du manteau neigeux

Situation avalancheuse typique : neige ventée neige humide

Déclenchements provoqués :
Au-dessus de 2000m, dans les pentes raides des versants allant du Nord au Sud-Est, des plaques à vent sont en cours de formation ce mercredi sous les chutes de neige. Elles viennent se superposer sur des plaques plus fines de mardi, et plus épaisses de lundi. Leur déclenchement par un simple skieur peut engendrer des cassures linéaires moyennes (taille 2), à grandes (taille 3) notamment en secteur frontalier où les accumulations de neige récente restent les plus importantes. Il n'est pas exclu de trouver des plaques à vent dans un large secteur Ouest, leur déclenchement engendrant des avalanches moyennes (taille 2).
Sous 2000m, quelques plaques à vent peu épaisses se forment ce mercredi, s'ajoutant à celles de mardi plus fines et de lundi plus épaisses, leur rupture engendrant des avalanches petites à moyennes (taille 1 à 2), plus rarement des grandes (taille 3) sur les pentes raides des versants allant du Nord vers le Sud-Est et notamment en secteur frontalier (accumulations plus importantes).

Départs spontanés :
Au-dessus de 2000m, des départs ponctuels de plaques décrites ci-dessus restent possibles, par surcharge par le vent, engendrant ainsi des avalanches généralement moyennes (taille 2), voire des grandes (taille 3) notamment en secteur frontalier.
Sous 2000m, avec l'humidification de la veille et celle se poursuivant ce mercredi en journée, des départs ponctuels en neige humide sont attendus en journée, générant de petites avalanches ou des moyennes (taille 1 à 2), plus rarement des grandes (taille 3) dans les versants Nord à Sud-Est et notamment en secteur frontalier. Des avalanches de fond restent aussi possibles en toutes orientations lorsque l'humidification atteint le sol, engendrant ainsi des avalanches moyennes (taille 2), à parfois grandes (taille 3) dans les zones d'accumulation les plus importantes.

Qualité de la neige

Enneigement : L'enneigement est assez correct pour la saison, mais les crêtes, cols et sommets sont souvent pelés par le vent dans les expositions ouest. Le manteau neigeux s'est bien humidifié ce mardi sous 1600/1700m, se réduisant progressivement. Nouvelles chutes de neige mercredi, petits centimètres de neige dès 1200m, un peu plus de neige au-dessus, notamment en secteur frontalier.
Limites skiables : Manteau neigeux skiable à partir de 1400/1500m ce mercredi.
État de la neige : Neige regelée sous 1600/1700m ce mercredi matin, fine couche de neige récente dès 1200m au fil de la journée. Neige plus souvent travaillée par le vent de Sud à Sud-Ouest au-dessus de 1700/1800m. Accumulations de neige ventée plus importantes en secteur frontalier.

Aperçu météo pour le mercredi 04 février

	nuit	matin	après-midi	soir

Quelques averses pour la journée, neige dès 1200m le matin, plutôt 1500m l'après-midi. Vent de Sud-Ouest le matin, Ouest/Nord-Ouest ensuite.

Pluie-Neige	1 100 m	1 400 m	1 500 m	1 600 m
Iso 0 °C	1 500 m	1 900 m	2 000 m	2 100 m
Vent 2000 m	↑ 45 km/h	↗ 35 km/h	→ 35 km/h	↗ 35 km/h
Vent 3000 m	↑ 80 km/h	↑ 70 km/h	→ 60 km/h	↗ 50 km/h

Épaisseur de neige hors-piste

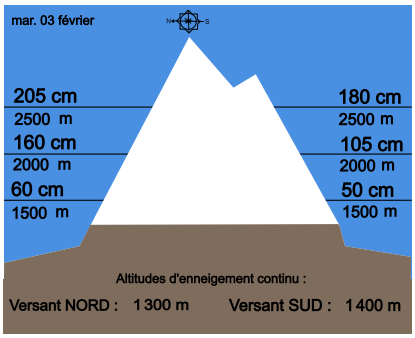

Précipitations à 1800 m

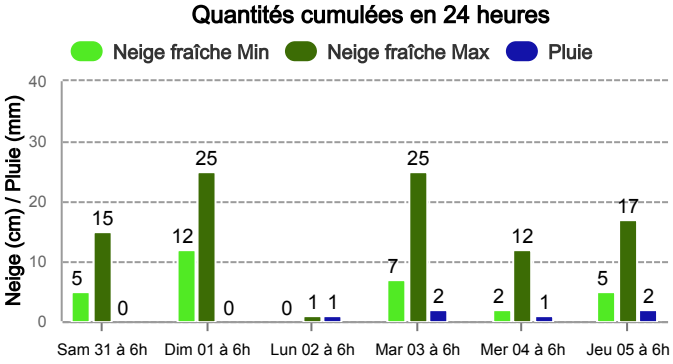

Tendance du jeudi 05 février

3 **Indice de risque marqué**

Maintien du risque marqué, nouvelles chutes de neige avec un vent de Sud-Ouest fort.

Pour consulter la vigilance en cours, veuillez vous rendre sur le site https://vigilance.meteofrance.fr/fr

Météo-France - 73 avenue de Paris, 94165 Saint-Mandé cedex - Contact : contact@meteo.fr

Rédigé par Météo-France avec la contribution des observateurs du réseau nivo-météorologiques. Partenariat : ANMSM (Maires de Stations de Montagne), DSF (Domaines Skiables de France), ADSP (Directeurs de Pistes et de la Sécurité des Stations de Sports d'Hiver) et autres acteurs de la montagne.

Bulletin neige & avalanches par téléphone au **0 892 68 10 20** Service 0,35 € / min + prix appel

RÉPUBLIQUE FRANÇAISE
Liberté Égalité Fraternité

METEO FRANCE
À VOS CÔTÉS, DANS UN CLIMAT QUI CHANGE

Bulletin d'estimation du risque d'avalanche

(valable en dehors des pistes balisées et ouvertes)

MASSIF : Haute-Bigorre

Rédigé le mardi 3 février 2026 à 16h

Conditions nivo-météo des 7 derniers jours

	mer. 28/01				jeu. 29/01				ven. 30/01				sam. 31/01				dim. 01/02				lun. 02/02				mar. 03/02			
	03h	09h	15h	21h	03h	09h	15h	21h	03h	09h	15h	21h	03h	09h	15h	21h	03h	09h	15h	21h	03h	09h	15h	21h	03h	09h	15h	21h
Météo																												
Vent (km/h)	60	55	55	80	70	100	70	90	100	90	60	90	100	105	100	70	40	40	45	50	70	125	120	80	50	45	55	75
à 3000m																												
Vent (km/h)	25	35	15	35	30	50	30	50	45	35	15	40	60	65	70	40	40	20	20	35	50	95	90	50	35	35	30	50
à 2000m																												

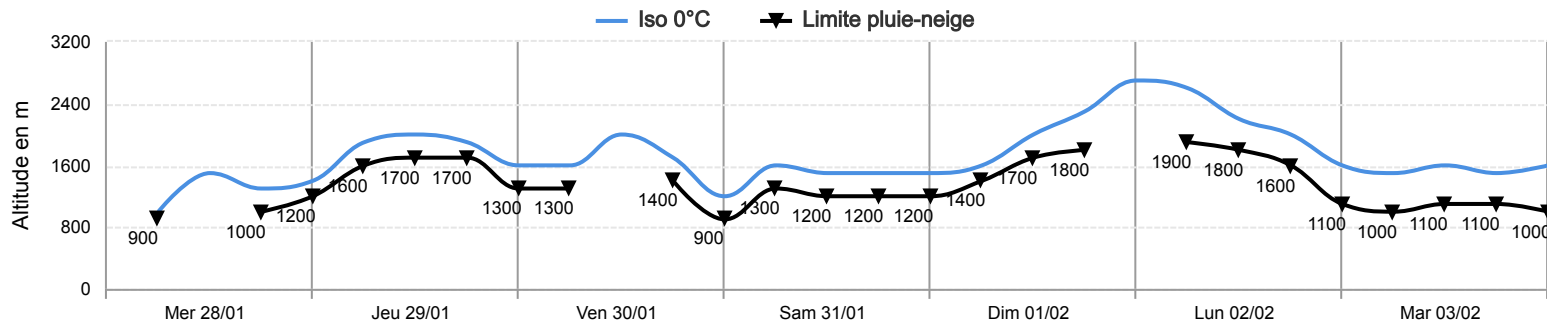

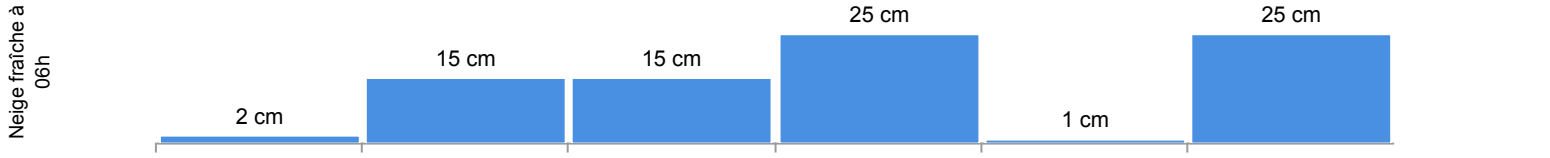

Risque d'avalanche	mer. 28/01	jeu. 29/01	ven. 30/01	sam. 31/01	dim. 01/02	lun. 02/02	mar. 03/02
	3	3	3	4	4	3	3

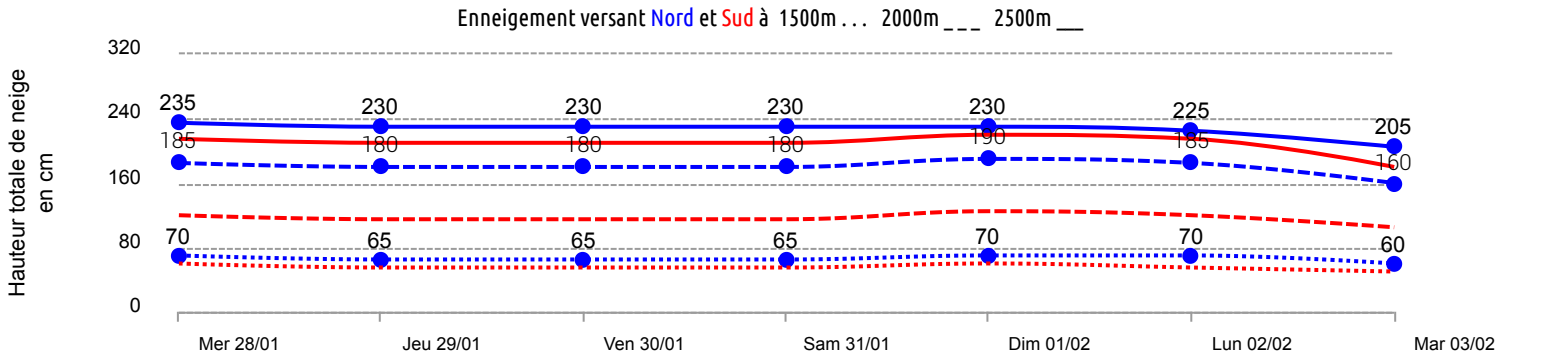

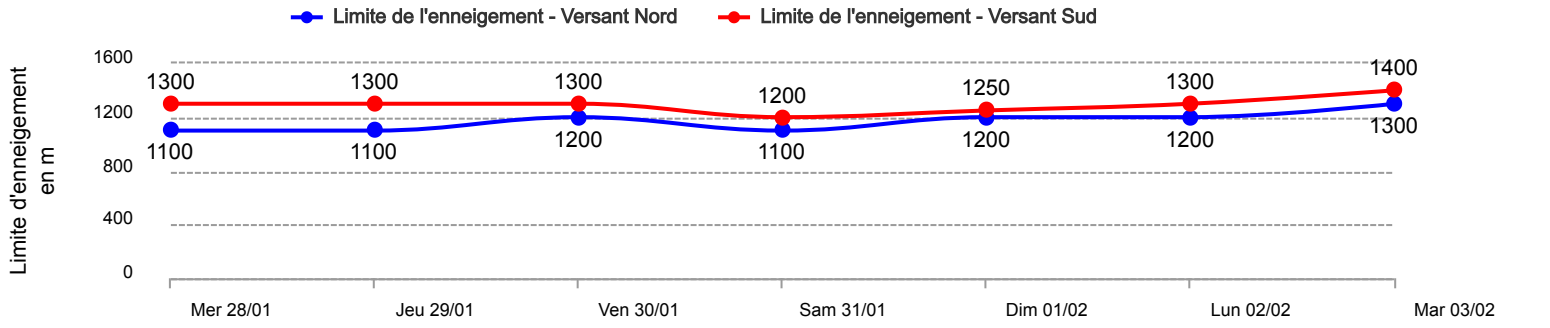

Pour consulter la vigilance en cours, veuillez vous rendre sur le site https://vigilance.meteofrance.fr/fr

Météo-France - 73 avenue de Paris, 94165 Saint-Mandé cedex - Contact : contact@meteo.fr

Rédigé par Météo-France avec la contribution des observateurs du réseau nivo-météorologiques. Partenariat : ANMSM (Maires de Stations de Montagne), DSF (Domaines Skiables de France), ADSP (Directeurs de Pistes et de la Sécurité des Stations de Sports d'Hiver) et autres acteurs de la montagne.

Bulletin neige & avalanches par téléphone au
0 892 68 10 20 Service 0,35 € / min + prix appel