# Bulletin d'estimation du risque d'avalanche
## (valable en dehors des pistes balisées et ouvertes)

# MASSIF : Mercantour

Rédigé le mardi 3 février 2026 à 16h

## Estimation des risques pour le : MERCREDI 04 FÉVRIER

**NOMBREUSES PLAQUES DANS LA NEIGE FRAICHE, LOCALEMENT VOLUMINEUSES**

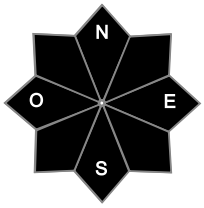


Indice de risque fort.

**Départs spontanés :** quelques départs de neige fraîche s'humidifiant en journée.

**Déclenchements provoqués :** nombreuses plaques dans la neige fraîche, localement volumineuses, en particulier sur l'est du massif.

Indices de risque : 5 très fort - 4 fort - 3 marqué - 2 limité - 1 faible -- En noir : les pentes les plus dangereuses

## Stabilité du manteau neigeux

**Situation avalancheuse typique :** neige fraîche couche fragile persistante

**Déclenchements provoqués :** nombreuses instabilités en place, pouvant être déclenchées à distance dans de nombreuses pentes supérieures à 30 degrés, y compris en forêts. De nombreuses plaques dans la neige fraiche sont en place, possibles en toutes orientations au dessus de 1700/1800 m environ. Elles sont généralement d'aspect friable et difficiles à détecter, sinon durcies par le vent dans les secteurs exposés. Leur déclenchement est possible au passage d'un seul skieur, et elles peuvent provoquer des avalanches de taille souvent moyenne, parfois grande dans les zones d'accumulation, en particulier des vallées de la Vésubie à la Roya où les cumuls de neige ont étés plus importants (taille 2 à 3).

En versants est, nord et ouest, la présence d'une couche fragile persistante au dessus de 1800/2000 m, peut occasionner des avalanches de plus grande taille (taille 3 à rarement 4), emportant une grande partie du manteau neigeux, parfois sur de grandes distances. Toutefois, leur déclenchement est généralement devenu difficile à cause des importantes accumulations de neige des derniers épisodes, qui isolent cette couche en profondeur, mais peut être rendu possible sous une forte contrainte comme le déclenchement d'une première avalanche en surface.

**Départs spontanés :** quelques départs de neige fraîche s'humidifiant en journée sont possibles. Départs ponctuels en pentes raides, de taille petite à moyenne (1 à 2)

## Qualité de la neige

**Enneigement** bon voire excédentaire jusqu'à basse altitude pour un début février.
Données observées : 125 cm à la nivôse de Millefonts à 2400 m.

**Enneigement skiable** dès 1200/1300 m en terrain favorable, mais peu de sous-couche sous 1600 m en général.

**État de la neige en surface** : couche de neige fraiche atteignant 20/30 cm à partir de 1800 m, localement 50 à 60 cm sur l'est du massif entre la Vésubie et la Roya. Cette neige est plus lourde sous 1800/2000 m environ, mais encore froide et légère au-dessus, localement travaillée par le vent en altitude dans les secteurs exposés. Corniches et congères parfois volumineuses en place.

## Aperçu météo pour le mercredi 04 février

| | nuit | matin | après-midi | soir |
|---|---|---|---|---|
| | | | | |

Quelques éclaircies matinales avant le retour des nuages l'après-midi.

| Pluie-Neige | | | | |
|---|---|---|---|---|
| Iso 0 °C | 1 600 m | 1 500 m | 1 600 m | 1 600 m |
| Vent 2000 m | ↓ 15 km/h | ↙ 25 km/h | ↗ 15 km/h | → 10 km/h |
| Vent 3000 m | ↗ 35 km/h | ← 20 km/h | ↗ 25 km/h | → 25 km/h |

## Épaisseur de neige hors-piste

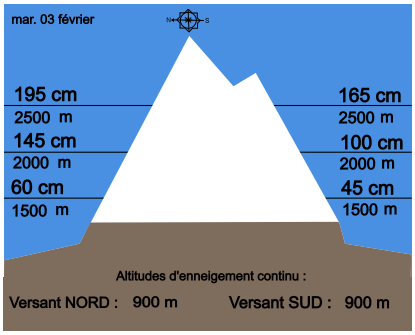


## Précipitations à 1800 m

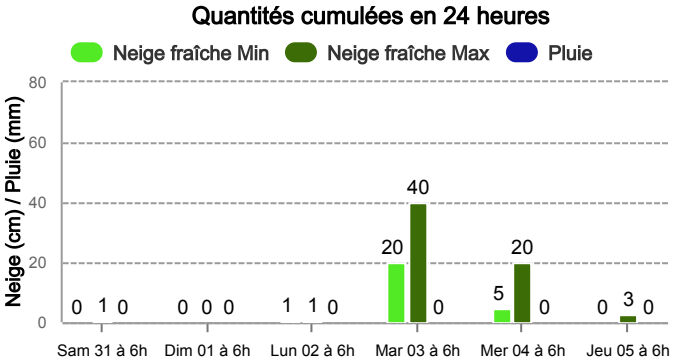


## Tendance du jeudi 05 février

**Indice de risque marqué**

Risque marqué avec la persistance de plaques dans la neige récente, encore insuffisamment stabilisées.

Pour consulter la vigilance en cours, veuillez vous rendre sur le site https://vigilance.meteofrance.fr/fr

Météo-France - 73 avenue de Paris, 94165 Saint-Mandé cedex - Contact : contact@meteo.fr

Rédigé par Météo-France avec la contribution des observateurs du réseau nivo-météorologiques. Partenariat : ANMSM (Maires de Stations de Montagne), DSF (Domaines Skiables de France), ADSP (Directeurs de Pistes et de la Sécurité des Stations de Sports d'Hiver) et autres acteurs de la montagne.

Bulletin neige & avalanches par téléphone au **0 892 68 10 20** Service 0,35 € / min + prix appel

RÉPUBLIQUE FRANÇAISE
*Liberté Égalité Fraternité*

METEO FRANCE
À VOS CÔTÉS, DANS UN CLIMAT QUI CHANGE

# Bulletin d'estimation du risque d'avalanche

## (valable en dehors des pistes balisées et ouvertes)

# MASSIF : Mercantour

Rédigé le mardi 3 février 2026 à 16h

## Conditions nivo-météo des 7 derniers jours

| | mer. 28/01 | | | | jeu. 29/01 | | | | ven. 30/01 | | | | sam. 31/01 | | | | dim. 01/02 | | | | lun. 02/02 | | | | mar. 03/02 | | | |
|---|---|---|---|---|---|---|---|---|---|---|---|---|---|---|---|---|---|---|---|---|---|---|---|---|---|---|---|---|
| | 03h | 09h | 15h | 21h | 03h | 09h | 15h | 21h | 03h | 09h | 15h | 21h | 03h | 09h | 15h | 21h | 03h | 09h | 15h | 21h | 03h | 09h | 15h | 21h | 03h | 09h | 15h | 21h |
| Météo | | | | | | | | | | | | | | | | | | | | | | | | | | | | |
| Vent (km/h) | 50 | 40 | 10 | 15 | 50 | 45 | 25 | 20 | 35 | 40 | 35 | 20 | 20 | 20 | 30 | 20 | 15 | 15 | 20 | 20 | 25 | 35 | 45 | 60 | 75 | 50 | 35 | 30 |
| à 3000m | ↑ | ↑ | → | ↘ | ↘ | ↘ | ↘ | ↘ | → | ↘ | → | ← | ← | ↖ | ↓ | ↘ | ↘ | ↗ | → | → | → | ↑ | ↑ | ↑ | ↑ | ↑ | ↗ | ↗ |
| Vent (km/h) | 10 | 10 | 10 | 15 | 20 | 15 | 15 | 10 | 10 | 15 | 15 | 10 | 10 | 15 | 20 | 10 | 15 | 10 | 10 | 10 | 10 | 10 | 20 | 25 | 25 | 40 | 25 | 15 |
| à 2000m | ↓ | ↓ | ↑ | ↘ | ↘ | ↘ | ↘ | ↘ | ↘ | ↘ | ↘ | ↘ | → | ↓ | ↓ | ↘ | ↓ | ↖ | ↘ | → | → | ↗ | ↑ | ↑ | ↖ | ↗ | ↗ | ↑ |

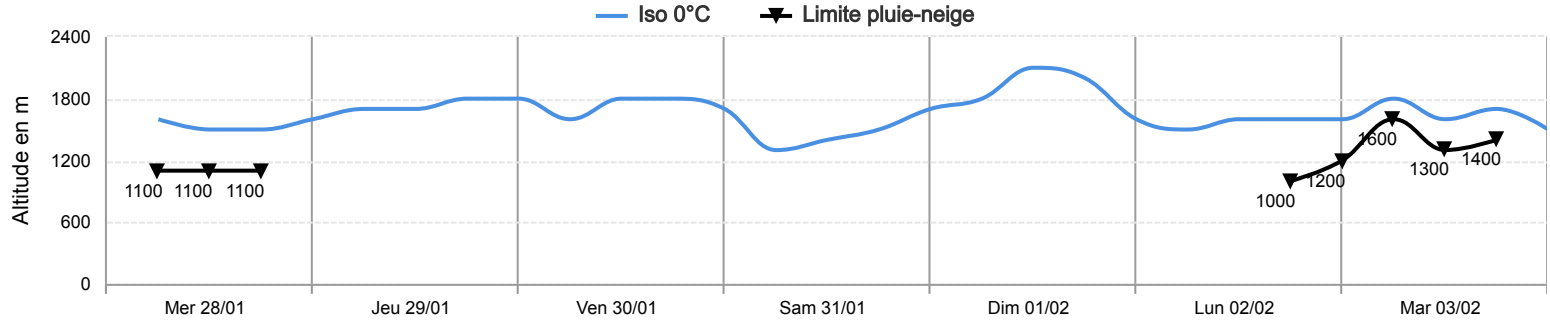


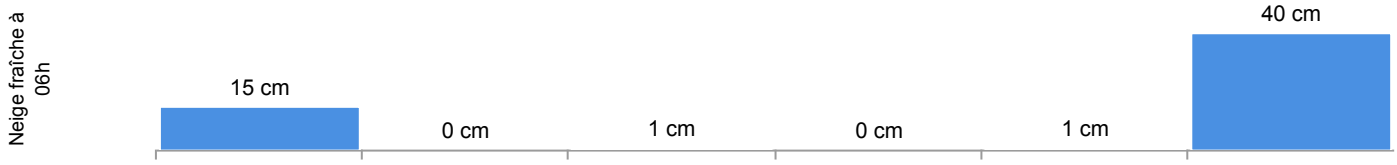


| Risque d'avalanche | mer. 28/01 | jeu. 29/01 | ven. 30/01 | sam. 31/01 | dim. 01/02 | lun. 02/02 | mar. 03/02 |
|---|---|---|---|---|---|---|---|
| | 4 | 4 | 3 | 3 | 3 | 3 | 4 |

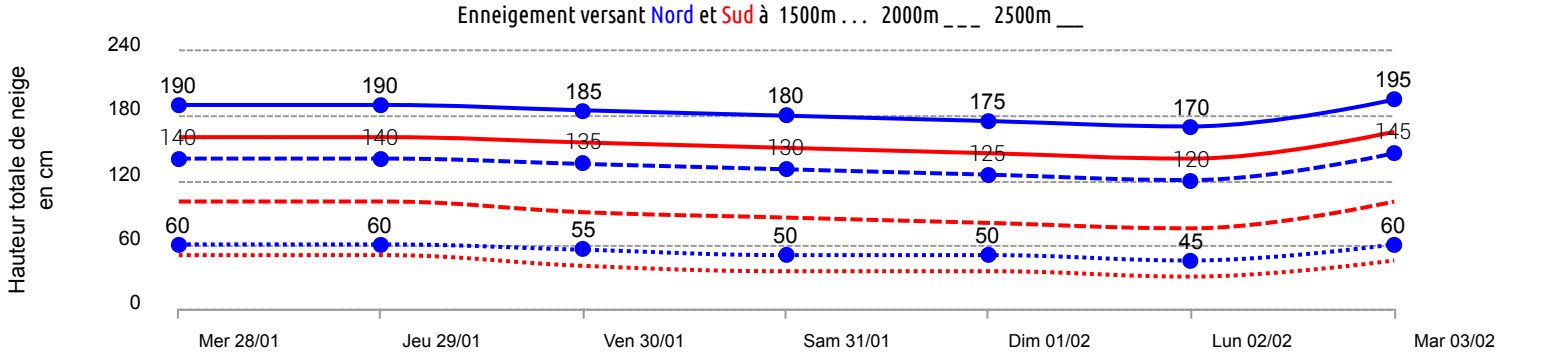


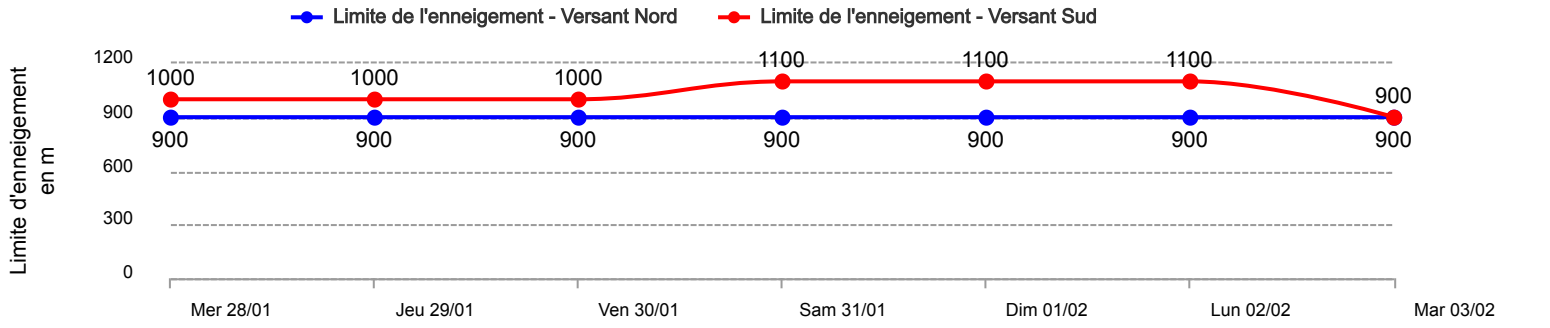


Pour consulter la vigilance en cours, veuillez vous rendre sur le site https://vigilance.meteofrance.fr/fr


Météo-France - 73 avenue de Paris, 94165 Saint-Mandé cedex - Contact : contact@meteo.fr



Rédigé par Météo-France avec la contribution des observateurs du réseau nivo-météorologiques. Partenariat : ANMSM (Maires de Stations de Montagne), DSF (Domaines Skiables de France), ADSP (Directeurs de Pistes et de la Sécurité des Stations de Sports d'Hiver) et autres acteurs de la montagne.



Bulletin neige & avalanches par téléphone au
0 892 68 10 20 Service 0,35 € / min + prix appel