Bulletin d'estimation du risque d'avalanche
(valable en dehors des pistes balisées et ouvertes)

MASSIF : Pays-Basque

Rédigé le mardi 3 février 2026 à 16h

Estimation des risques pour le : MERCREDI 04 FÉVRIER

NEIGE VENTÉE EN ALTITUDE, HUMIDIFICATION PROGRESSIVE PLUS BAS.

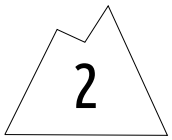

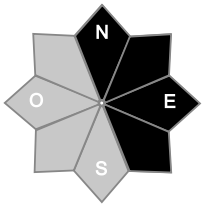

Plaques en altitude.

Indices de risque : 5 très fort - 4 fort - 3 marqué - 2 limité - 1 faible -- En noir : les pentes les plus dangereuses

Indice de risque limité.

Départs spontanés : Départs ponctuels en neige ventée et humide, avalanches de fond possibles.

Déclenchements provoqués : Quelques plaques en altitude.

Stabilité du manteau neigeux

Situation avalancheuse typique : neige ventée neige humide

Déclenchements provoqués :
Quelques plaques à vent peu épaisses se forment ce mercredi, s'ajoutant à celles de mardi plus fines et de lundi plus épaisses. Elles restent facilement déclenchables par un simple skieur et leur rupture peut engendrer des cassures linéaires petites à moyennes (taille 1 à 2), plus rarement des grandes (taille 3) sur les pentes raides des versants allant du Nord vers le Sud-Est.

Départs spontanés :
Des départs ponctuels de plaques décrites ci-dessus restent possibles, par surcharge par le vent, engendrant ainsi des avalanches petites à moyennes (taille 1 à 2), plus rarement des grandes (taille 3) en particulier dans les pentes raides des versants allant du Nord au Sud-Est.
Avec l'humidification de la veille et celle se poursuivant ce mercredi en journée, des départs ponctuels en neige humide sont attendus en journée, générant de petites avalanches ou des moyennes (taille 1 à 2), plus rarement des grandes (taille 3) dans les versants Nord à Sud-Est. Des avalanches de fond restent aussi possibles en toutes orientations lorsque l'humidification atteint le sol, engendrant ainsi des avalanches moyennes (taille 2), à parfois grandes (taille 3) dans les zones d'accumulation les plus importantes.

Qualité de la neige

Enneigement : L'enneigement est assez bon pour la saison, mais les crêtes, cols et sommets sont souvent pelés par le vent en altitude dans les expositions ouest. Le manteau neigeux s'est bien humidifié mardi sous 1600/1700m, se réduisant progressivement. Nouvelles chutes de neige mercredi, petits centimètres de neige dès 1200m, un peu plus de neige au-dessus.
Limites skiables : Manteau neigeux skiable à partir de 1400/1500m ce mercredi.
État de la neige : Neige regelée sous 1600/1700m ce mercredi matin, fine couche de neige récente dès 1200m au fil de la journée. Neige plus souvent travaillée par le vent de Sud à Sud-Ouest au-dessus de 1700/1800m. Accumulations de neige ventée plus importantes en secteur frontalier.

Aperçu météo pour le mercredi 04 février

	nuit	matin	après-midi	soir

Quelques averses pour la journée, neige dès 1200m le matin, plutôt 1500m l'après-midi. Vent de Sud-Ouest le matin, Ouest/Nord-Ouest ensuite.

Pluie-Neige	1 100 m	1 100 m	1 400 m	1 500 m
Iso 0 °C	1 800 m	2 000 m	2 100 m	2 200 m
Vent 1000 m	↑ 70 km/h	↑ 75 km/h	→ 55 km/h	↗ 55 km/h
Vent 2000 m	↑ 100 km/h	↑ 90 km/h	→ 65 km/h	↗ 70 km/h

Épaisseur de neige hors-piste

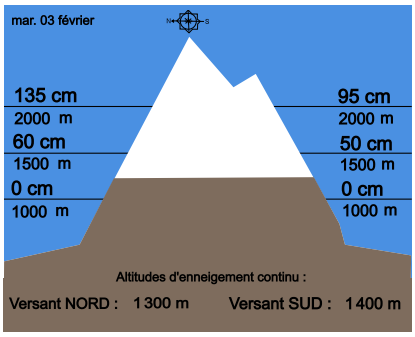

Précipitations à 1800 m

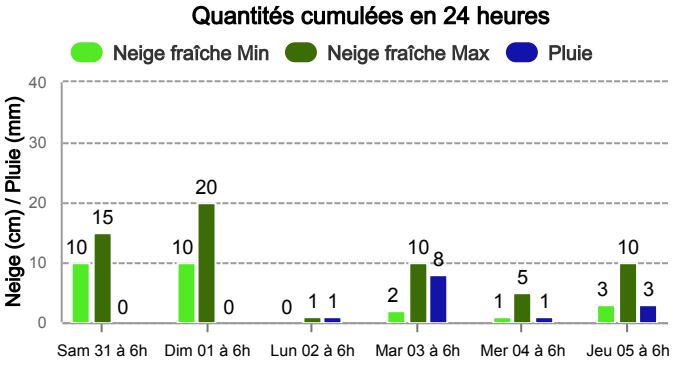

Tendance du jeudi 05 février

Indice de risque limité

Maintien d'un risque limité, nouvelles chutes de neige et vent de Sud-Ouest fort.

Pour consulter la vigilance en cours, veuillez vous rendre sur le site https://vigilance.meteofrance.fr/fr

Météo-France - 73 avenue de Paris, 94165 Saint-Mandé cedex - Contact : contact@meteo.fr

Rédigé par Météo-France avec la contribution des observateurs du réseau nivo-météorologiques. Partenariat : ANMSM (Maires de Stations de Montagne), DSF (Domaines Skiables de France), ADSP (Directeurs de Pistes et de la Sécurité des Stations de Sports d'Hiver) et autres acteurs de la montagne.

Bulletin neige & avalanches par téléphone au
0 892 68 10 20 Service 0,35 € / min + prix appel

Bulletin d'estimation du risque d'avalanche

(valable en dehors des pistes balisées et ouvertes)

MASSIF : Pays-Basque

Rédigé le mardi 3 février 2026 à 16h

Conditions nivo-météo des 7 derniers jours

	mer. 28/01				jeu. 29/01				ven. 30/01				sam. 31/01				dim. 01/02				lun. 02/02				mar. 03/02			
	03h	09h	15h	21h	03h	09h	15h	21h	03h	09h	15h	21h	03h	09h	15h	21h	03h	09h	15h	21h	03h	09h	15h	21h	03h	09h	15h	21h
Météo																												
Vent (km/h)	40	40	55	60	65	80	75	75	80	95	65	80	70	90	90	60	70	45	50	80	95	120	120	80	80	80	80	90
à 2000m																												
Vent (km/h)	15	10	25	35	45	50	50	50	50	65	40	50	50	70	70	35	30	30	40	60	60	90	90	55	55	60	55	65
à 1000m																												

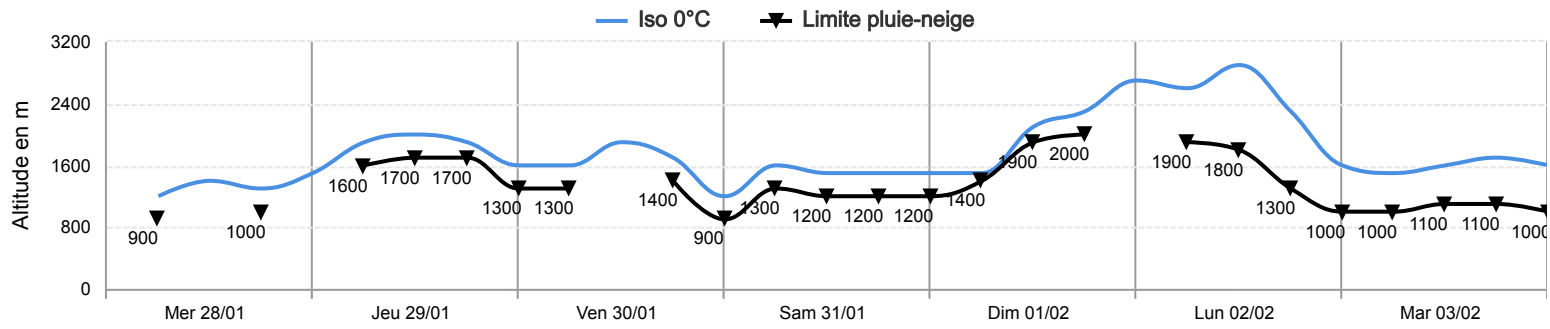

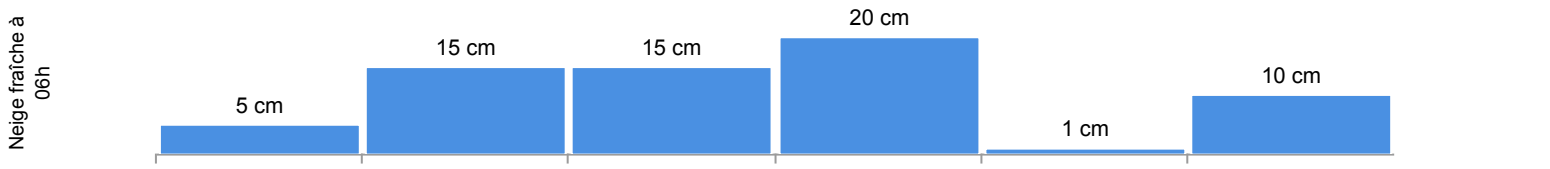

Risque d'avalanche	mer. 28/01	jeu. 29/01	ven. 30/01	sam. 31/01	dim. 01/02	lun. 02/02	mar. 03/02
	2	2	3	4	3	3	2

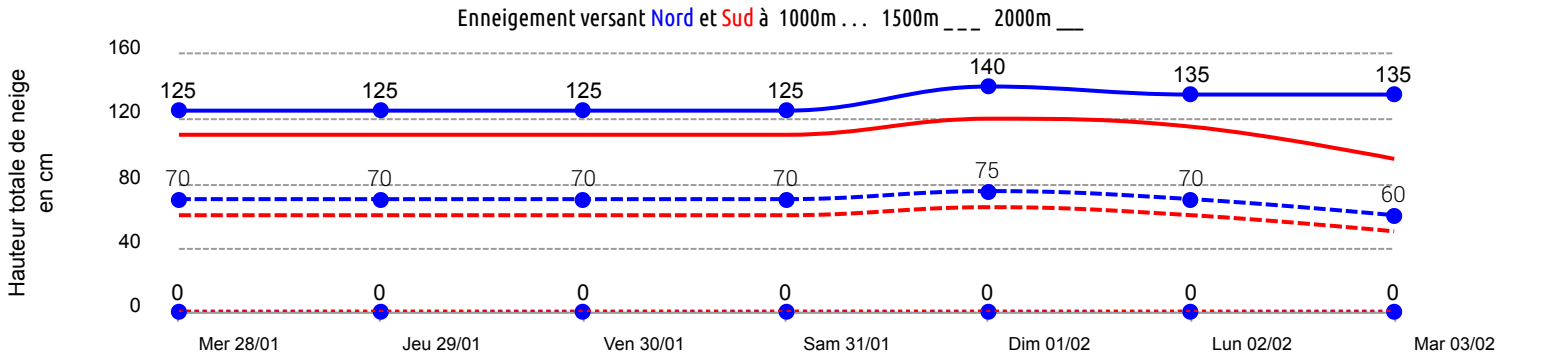

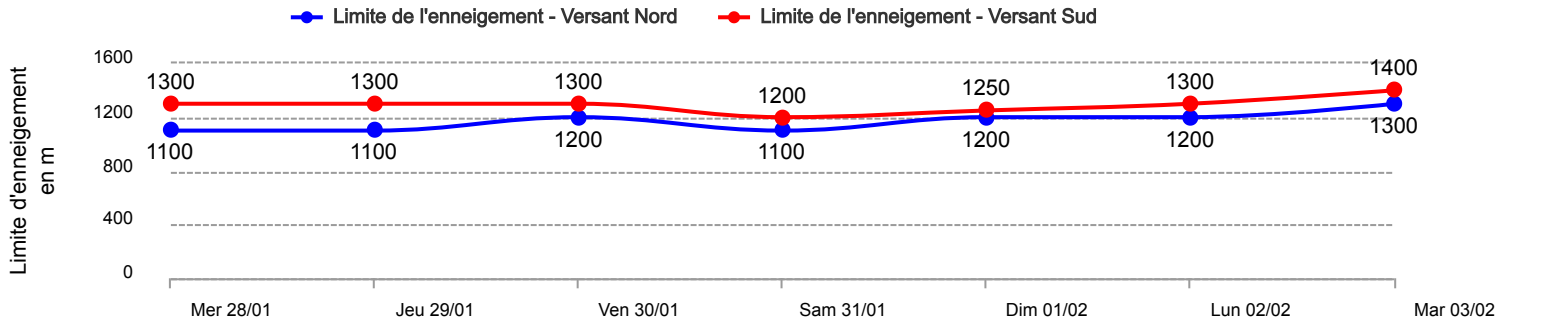

Pour consulter la vigilance en cours, veuillez vous rendre sur le site https://vigilance.meteofrance.fr/fr

Météo-France - 73 avenue de Paris, 94165 Saint-Mandé cedex - Contact : contact@meteo.fr

Bulletin neige & avalanches par téléphone au

0 892 68 10 20 Service 0,35 € / min + prix appel

Rédigé par Météo-France avec la contribution des observateurs du réseau nivo-météorologiques. Partenariat : ANMSM (Maires de Stations de Montagne), DSF (Domaines Skiables de France), ADSP (Directeurs de Pistes et de la Sécurité des Stations de Sports d'Hiver) et autres acteurs de la montagne.