Bulletin d'estimation du risque d'avalanche
(valable en dehors des pistes balisées et ouvertes)

MASSIF : Ubaye

Rédigé le mardi 3 février 2026 à 16h

Estimation des risques pour le : MERCREDI 04 FÉVRIER

NOMBREUSES INSTABILITÉS DANS LA NEIGE FRAICHE, LOCALEMENT VOLUMINEUSES

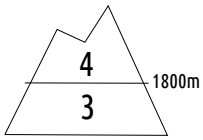

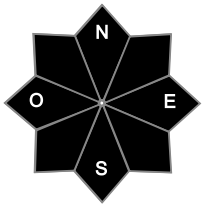

Au-dessus de 1800m indice de risque fort, plus bas indice marqué.

Départs spontanés : quelques départs de neige fraîche s'humidifiant en journée.

Déclenchements provoqués : nombreuses instabilités dans la neige fraîche, localement volumineuses.

Indices de risque : 5 très fort - 4 fort - 3 marqué - 2 limité - 1 faible -- En noir : les pentes les plus dangereuses

Stabilité du manteau neigeux

Situation avalancheuse typique : neige fraîche couche fragile persistante

Déclenchements provoqués : nombreuses instabilités en place, pouvant être déclenchées à distance dans de nombreuses pentes supérieures à 30 degrés, y compris en forêts. Des plaques dans la neige fraiche sont en place, possibles en toutes orientations surtout au dessus de 1800 m environ. Elles sont généralement d'aspect friable et difficiles à détecter, sinon durcies par le vent dans les secteurs exposés. Leur déclenchement est possible au passage d'un seul skieur, et elles peuvent provoquer des avalanches de taille petite à moyenne (taille 1 à 2).

En versants est, nord et ouest, la présence fréquente d'une couche fragile persistante au dessus de 1800/2000 m, parfois encore insuffisamment enfouie, peut occasionner des avalanches de taille moyenne à grande (2 à 3) en emportant une grande partie du manteau neigeux, parfois sur de grandes distances.

En dessous de 1800 m environ, les instabilités sont moins nombreuses, plus difficiles à déclencher, et les avalanches associées sont de taille plus petite, avec des cassures moins épaisses.

Départs spontanés : quelques départs de neige fraîche s'humidifiant en journée sont possibles. Départs ponctuels en pentes raides, de petite taille.

Qualité de la neige

Enneigement proche des normales pour un début février.
Données observées : 98 cm au-dessus de Larche à 2270 m, 16 cm à Barcelonnette à 1200 m.

Enneigement skiable dès 1200/1300 m en terrain favorable, mais peu de sous-couche sous 1600 m en général.

État de la neige en surface : couche de neige fraiche atteignant 15/20 cm à partir de 1800 m, localement 30 cm en bordure de la Tinée et du Haut-Var. Cette neige est plus lourde sous 1800/2000 m environ, mais encore froide et légère au-dessus, localement travaillée par le vent en altitude dans les secteurs exposés. Corniches et congères parfois volumineuses en place.

Aperçu météo pour le mercredi 04 février

	nuit	matin	après-midi	soir
	Quelques éclaircies matinales avant le retour des nuages l'après-midi.			
Pluie-Neige				
Iso 0 °C	1 700 m	1 500 m	1 700 m	1 500 m
Vent 2000 m	↖ 20 km/h	← 20 km/h	↖ 20 km/h	→ 10 km/h
Vent 3000 m	↑ 25 km/h	↖ 25 km/h	↑ 25 km/h	→ 20 km/h

Épaisseur de neige hors-piste

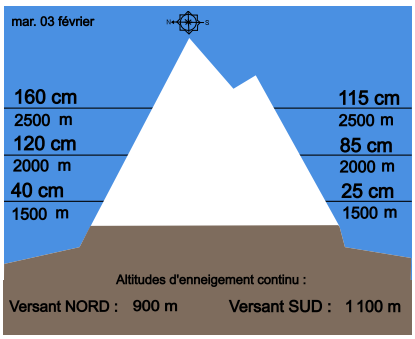

Précipitations à 1800 m

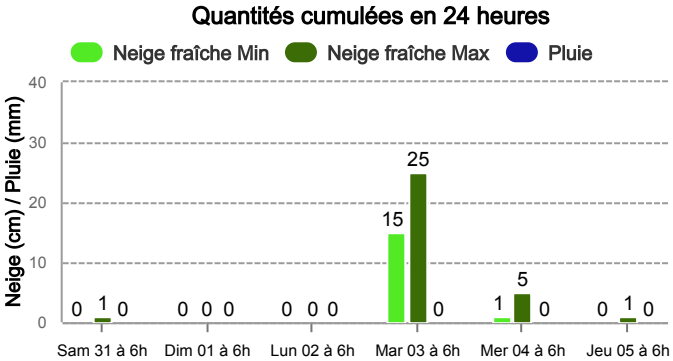

Tendance du jeudi 05 février

Indice de risque marqué

Risque marqué avec la persistance de plaques dans la neige récente, encore insuffisamment stabilisées, et des couches fragiles enfouies localement sollicitables.

Pour consulter la vigilance en cours, veuillez vous rendre sur le site https://vigilance.meteofrance.fr/fr

Météo-France - 73 avenue de Paris, 94165 Saint-Mandé cedex - Contact : contact@meteo.fr

Rédigé par Météo-France avec la contribution des observateurs du réseau nivo-météorologiques. Partenariat : ANMSM (Maires de Stations de Montagne), DSF (Domaines Skiables de France), ADSP (Directeurs de Pistes et de la Sécurité des Stations de Sports d'Hiver) et autres acteurs de la montagne.

Bulletin neige & avalanches par téléphone au **0 892 68 10 20** Service 0,35 € / min + prix appel

RÉPUBLIQUE FRANÇAISE
Liberté Égalité Fraternité

METEO FRANCE
À VOS CÔTÉS, DANS UN CLIMAT QUI CHANGE

Bulletin d'estimation du risque d'avalanche

(valable en dehors des pistes balisées et ouvertes)

MASSIF : Ubaye

Rédigé le mardi 3 février 2026 à 16h

Conditions nivo-météo des 7 derniers jours

	mer. 28/01				jeu. 29/01				ven. 30/01				sam. 31/01				dim. 01/02				lun. 02/02				mar. 03/02			
	03h	09h	15h	21h	03h	09h	15h	21h	03h	09h	15h	21h	03h	09h	15h	21h	03h	09h	15h	21h	03h	09h	15h	21h	03h	09h	15h	21h
Météo																												
Vent (km/h)	50	35	15	30	45	40	25	20	30	40	30	20	25	15	20	15	15	15	15	20	20	25	35	55	70	45	35	25
à 3000m	↑	↗	→	↓	↘	↘	↘	↘	↘	↘	→	←	←	←	↘	→	↘	↘	→	→	→	↗	↑	↖	↖	↑	↗	↑
Vent (km/h)	25	20	10	15	20	15	20	10	10	15	20	5	5	5	15	10	10	10	15	10	10	15	20	30	45	35	25	20
à 2000m	↖	↑	↗	↓	↓	↘	→	→	→	↘	→	←	↖	↖	↑	↘	↙	↙	→	→	→	↑	↑	↖	↖	↑	↑	↖

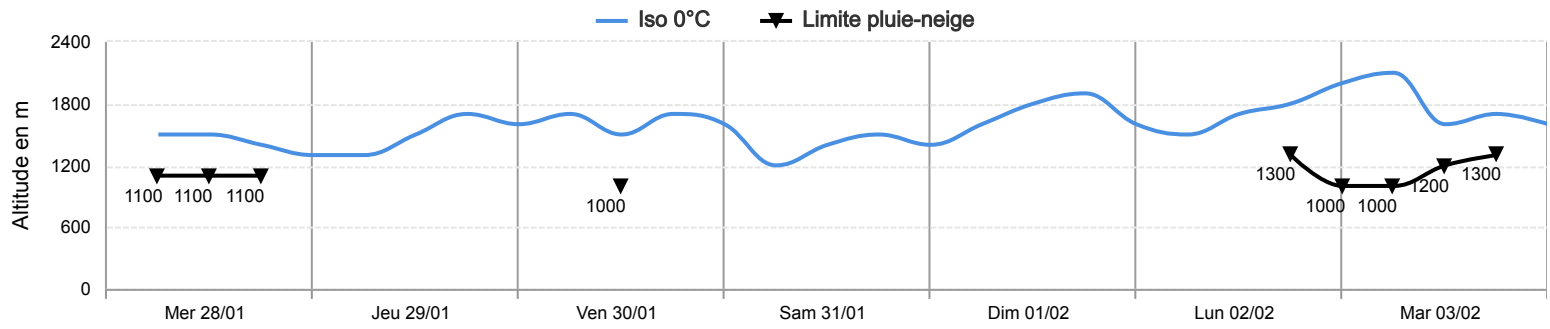

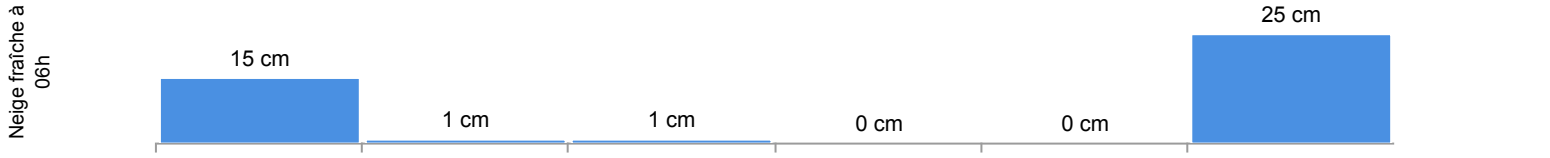

Risque d'avalanche	mer. 28/01	jeu. 29/01	ven. 30/01	sam. 31/01	dim. 01/02	lun. 02/02	mar. 03/02
	4	4	4	3	3	3	4

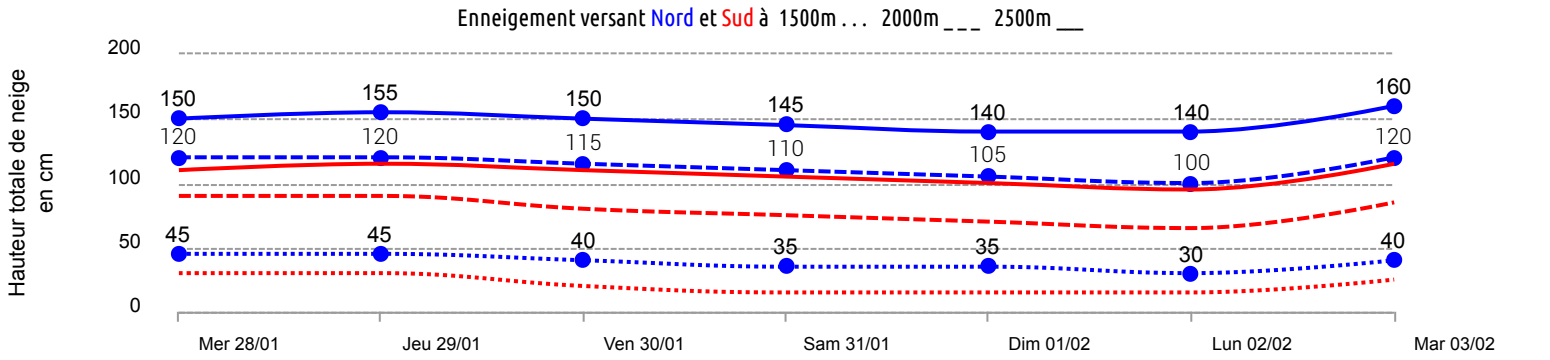

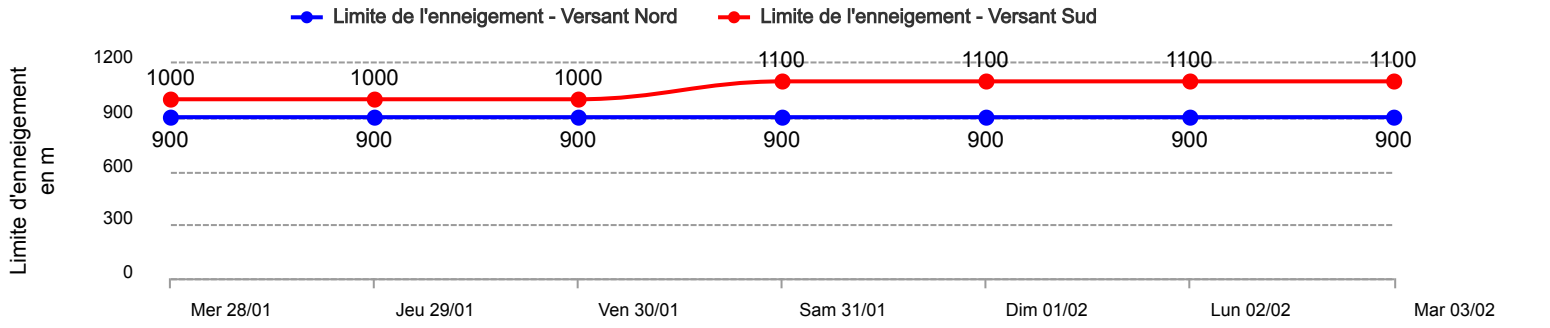

Pour consulter la vigilance en cours, veuillez vous rendre sur le site https://vigilance.meteofrance.fr/fr

Météo-France - 73 avenue de Paris, 94165 Saint-Mandé cedex - Contact : contact@meteo.fr

Rédigé par Météo-France avec la contribution des observateurs du réseau nivo-météorologiques. Partenariat : ANMSM (Maires de Stations de Montagne), DSF (Domaines Skiables de France), ADSP (Directeurs de Pistes et de la Sécurité des Stations de Sports d'Hiver) et autres acteurs de la montagne.

Bulletin neige & avalanches par téléphone au
0 892 68 10 20 Service 0,35 € / min + prix appel