Bulletin d'estimation du risque d'avalanche
(valable en dehors des pistes balisées et ouvertes)

MASSIF : Vanoise

Rédigé le mardi 3 février 2026 à 16h

Estimation des risques pour le : MERCREDI 04 FÉVRIER

QUELQUES PLAQUES « À VENT » REPOSANT SUR UN MANTEAU GLOBALEMENT INSTABLE.

3

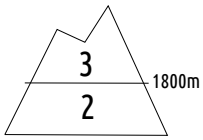

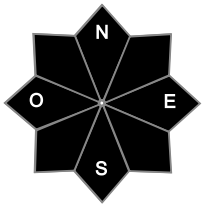

Même loin des crêtes

Au-dessus de 1800m indice de risque marqué, plus bas indice limité.

Départs spontanés : rares petits départs dans les pentes raides ensoleillées.

Déclenchements provoqués : quelques plaques dans la neige ventée. Couche fragile persistante dans de nombreuses pentes.

Indices de risque : 5 très fort - 4 fort - 3 marqué - 2 limité - 1 faible -- En noir : les pentes les plus dangereuses

Stabilité du manteau neigeux

Situation avalancheuse typique :

neige ventée

couche fragile persistante

Déclenchements provoqués :

(1) **Quelques plaques généralement friables** suite au fort coup de vent de sud (foehn) de la nuit de lundi à mardi. Encore généralement **réactives**, on les trouve en tous versants, aussi bien **près des crêtes qu'en pied de pentes**. Tailles 2 (moyennes) avec des cassures très variables, pour une moyenne **de 40-60 cm** d'épaisseur. *Observables : indices de transport, accumulation ferme sous les skis.*

(2) La **couche fragile persistante** (**grains anguleux** semblables à du gros sel)**, enfouie** depuis plusieurs semaine, reste **généralisée dès 1800 m**, dans les pentes **Nord**, **Est** et **Ouest** mais **aussi en Sud à haute altitude**. Elle vient former une épaisse structure de plaque qui, en cas de déclenchement, entraîne l'ensemble du manteau neigeux. Déclenchement aléatoire, parfois possible à distance, provoquant des avalanches de taille 2 à 3 (grandes), avec des cassures s'approchant d'1m. *Observables : woumfs, tests CT/ECT pour identifier la couche fragile.*

A fortiori, une première avalanche dans la neige ventée (1) pourrait mobiliser en cascade la couche fragile enfouie (2).

Départs spontanés : rares petits départs ponctuels dans les pentes raides au soleil, taille 1 (petite avalanche, généralement de simples boulettes). Vu l'instabilité du manteau, cf (1) et (2), un premier départ ponctuel peut exceptionnellement venir déclencher une plaque, engendrant alors une avalanche de plus grande envergure.

Qualité de la neige

Enneigement : tout à fait correct pour la saison.

Limite skiable : Les versants froids voyant pas ou peu le soleil ont gardé de la neige à basse altitude, skiable sur l'herbe ou sur pistes forestières dès 800 à 1000m. Sur terrain rocheux, il vaut mieux atteindre 1300 m en N, 1800 m en Sud pour trouver un terrain plus serein.

Qualité de la neige : manteau neigeux partiellement travaillé par le vent. On trouve encore de la neige poudreuse légère dans les secteurs à l'abri, tandis que la neige est souvent raffermie par le vent ailleurs. Neige transformée en tous versants sous 1500 m, et faiblement croutée jusque vers 2000/2200 m en sud raide (potentiellement pénible à skier).

Aperçu météo pour le mercredi 04 février

	nuit	matin	après-midi	soir
Ciel peu nuageux le matin, un peu voilé dans l'après-midi. Globalement bien lumineux.				
Pluie-Neige				
Iso 0 °C	1 800 m	1 700 m	1 800 m	1 700 m
Vent 2500 m	↖ 50 km/h	↖ 20 km/h	↖ 20 km/h	↑ 10 km/h
Vent 3500 m	↑ 40 km/h	↑ 30 km/h	→ 30 km/h	→ 20 km/h

Épaisseur de neige hors-piste

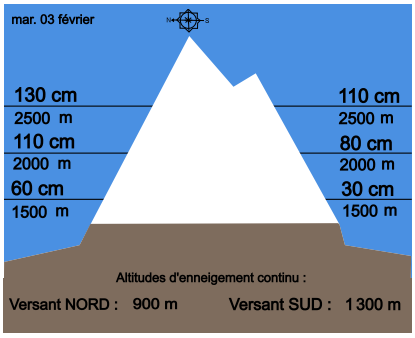

Précipitations à 1800 m

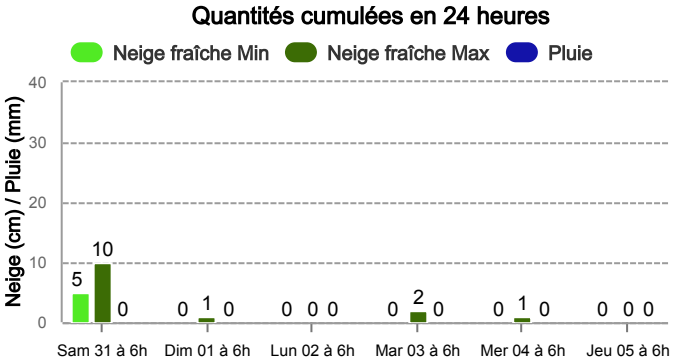

Tendance du jeudi 05 février

3

Indice de risque marqué

Ciel peu nuageux et vent faible en journée de jeudi. Les plaques en surface se stabilisent assez rapidement, mais les couches fragiles enfouies sont toujours présentes et piégeuses : le risque est stationnaire.

Pour consulter la vigilance en cours, veuillez vous rendre sur le site https://vigilance.meteofrance.fr/fr

Météo-France - 73 avenue de Paris, 94165 Saint-Mandé cedex - Contact : contact@meteo.fr

Rédigé par Météo-France avec la contribution des observateurs du réseau nivo-météorologiques. Partenariat : ANMSM (Maires de Stations de Montagne), DSF (Domaines Skiables de France), ADSP (Directeurs de Pistes et de la Sécurité des Stations de Sports d'Hiver) et autres acteurs de la montagne.

Bulletin neige & avalanches par téléphone au

0 892 68 10 20 Service 0,35 € / min + prix appel

RÉPUBLIQUE FRANÇAISE
Liberté Égalité Fraternité

METEO FRANCE
À VOS CÔTÉS, DANS UN CLIMAT QUI CHANGE

Bulletin d'estimation du risque d'avalanche

(valable en dehors des pistes balisées et ouvertes)

MASSIF : Vanoise

Rédigé le mardi 3 février 2026 à 16h

Conditions nivo-météo des 7 derniers jours

	mer. 28/01				jeu. 29/01				ven. 30/01				sam. 31/01				dim. 01/02				lun. 02/02				mar. 03/02			
	03h	09h	15h	21h	03h	09h	15h	21h	03h	09h	15h	21h	03h	09h	15h	21h	03h	09h	15h	21h	03h	09h	15h	21h	03h	09h	15h	21h
Météo																												
Vent (km/h)	55	30	25	35	35	20	20	30	40	35	35	25	25	20	20	20	20	20	30	30	35	35	55	80	90	75	50	35
à 3500m																												
Vent (km/h)	40	15	10	15	20	15	15	10	10	15	15	10	15	10	10	10	10	10	10	10	15	25	40	65	80	60	35	25
à 2500m																												

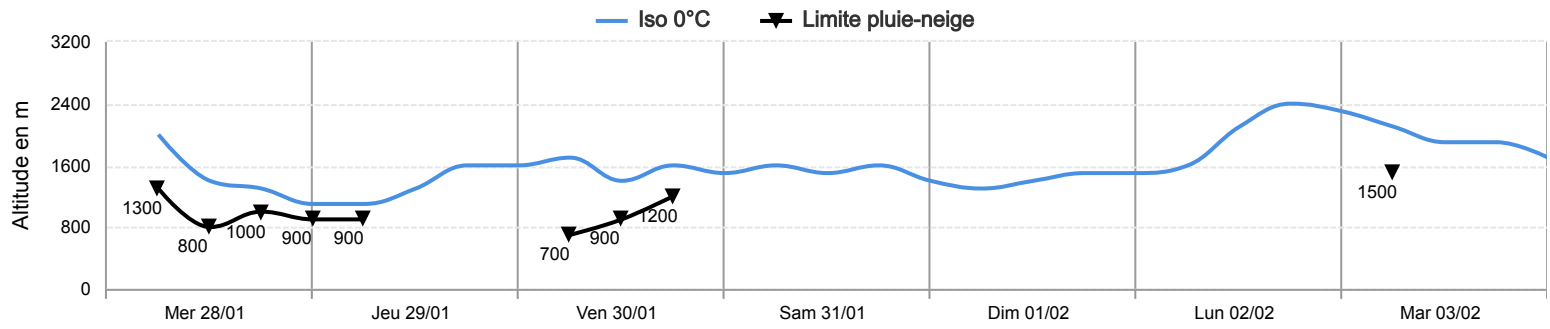

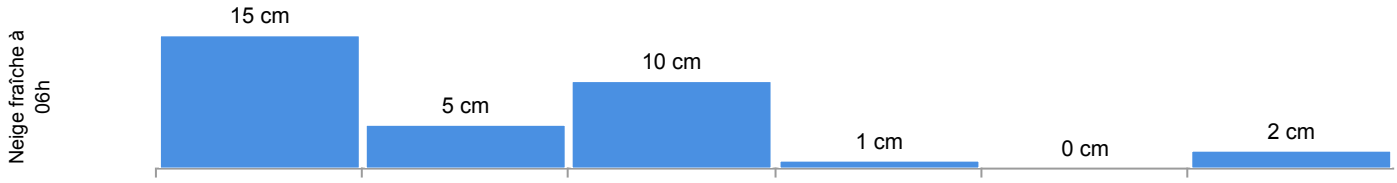

Risque d'avalanche	mer. 28/01	jeu. 29/01	ven. 30/01	sam. 31/01	dim. 01/02	lun. 02/02	mar. 03/02
	3	3	3	3	3	3	3

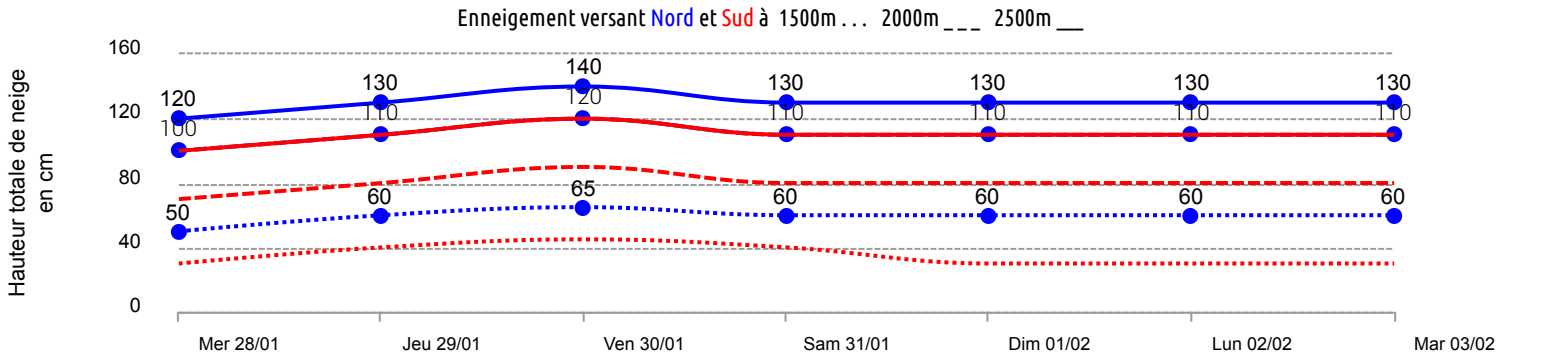

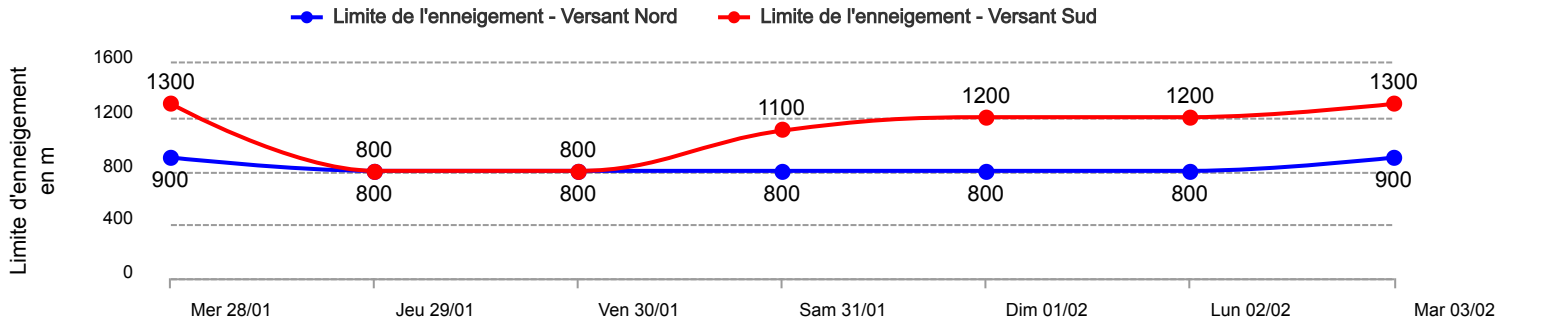

Pour consulter la vigilance en cours, veuillez vous rendre sur le site https://vigilance.meteofrance.fr/fr

Météo-France - 73 avenue de Paris, 94165 Saint-Mandé cedex - Contact : contact@meteo.fr

Bulletin neige & avalanches par téléphone au

0 892 68 10 20 Service 0,35 € / min + prix appel

Rédigé par Météo-France avec la contribution des observateurs du réseau nivo-météorologiques. Partenariat : ANMSM (Maires de Stations de Montagne), DSF (Domaines Skiables de France), ADSP (Directeurs de Pistes et de la Sécurité des Stations de Sports d'Hiver) et autres acteurs de la montagne.