Bulletin d'estimation du risque d'avalanche
(valable en dehors des pistes balisées et ouvertes)

MASSIF : Vercors

Rédigé le mardi 3 février 2026 à 16h

Estimation des risques pour le : MERCREDI 04 FÉVRIER

L'ÉPISODE DE VENT DE SUD AUGMENTE L'INSTABILITÉ DU MANTEAU NEIGEUX.

3

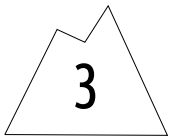

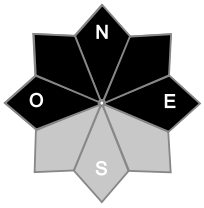

Indice de risque marqué.

Départs spontanés : Départs de plaques chargées par le vent toujours possibles..

Déclenchements provoqués : Instabilités surtout présentes en versants froids.

Indices de risque : 5 très fort - 4 fort - 3 marqué - 2 limité - 1 faible -- En noir : les pentes les plus dangereuses

Stabilité du manteau neigeux

Situation avalancheuse typique : neige ventée

Déclenchements provoqués : la petite couche de neige récente (10/15 cm) a déjà subi un fort transport par le vent de sud, créant souvent des instabilités faciles à déclencher dans les ubacs. D'ampleur généralement limitée, ces plaques de neige en cours de densification peuvent être ponctuellement à l'origine de plus grosses avalanches quand des couches fragiles plus profondes viennent à être sollicitées sur leur trajet. Le risque est surtout présent au dessus de 1700 m environ.
Départs spontanés : quelques départs spontanés de plaques chargées par le vent de sud sont encore possibles jusqu'en mi-journée de mercredi. Méfiance également l'après-midi car la couverture nuageuse pourrait accélérer l'humidification superficielle du manteau neigeux et provoquer quelques purges de neige lourde dans les endroits restés à l'ombre.

Qualité de la neige

Qualification de l'enneigement : l'enneigement est redevenu correct voire bon pour la saison, mais l'épisode de vent de Sud modifie beaucoup la répartition spatiale de la neige.

Limites skiables : vers 1100/1400 m, hors sapins.

Qualité de la neige mercredi : neige poudreuse dans les pentes à l'ombre et à l'abri du vent. Neige croûtée puis lourde dans les versants au soleil jusqu'au moins 1800 m. Neige fortement soufflée et densifiée près des crêtes avec des cailloux qui ressortent par endroits.

Aperçu météo pour le mercredi 04 février

	nuit	matin	après-midi	soir
Pluie-Neige				
Iso 0 °C	1 700 m	1 600 m	1 700 m	1 600 m
Vent 1500 m	40 km/h	45 km/h	40 km/h	25 km/h
Vent 2000 m	45 km/h	50 km/h	50 km/h	30 km/h

Épaisseur de neige hors-piste

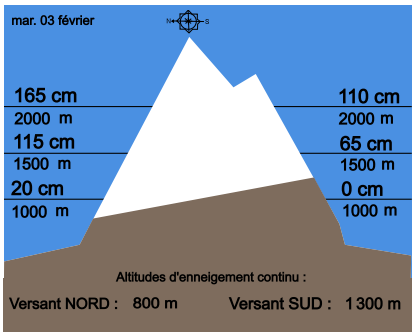

Précipitations à 1800 m

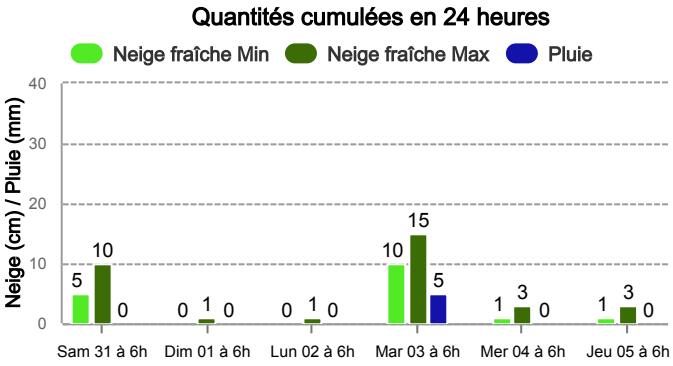

Tendance du jeudi 05 février

3

Indice de risque marqué

Jeudi, lente stabilisation dans les adrets. Par contre les versants ombragés resteront sensibles. Nouvelle chute de neige en soirée, augmentant de nouveau les risques.

Pour consulter la vigilance en cours, veuillez vous rendre sur le site https://vigilance.meteofrance.fr/fr

Météo-France - 73 avenue de Paris, 94165 Saint-Mandé cedex - Contact : contact@meteo.fr

Rédigé par Météo-France avec la contribution des observateurs du réseau nivo-météorologiques. Partenariat : ANMSM (Maires de Stations de Montagne), DSF (Domaines Skiables de France), ADSP (Directeurs de Pistes et de la Sécurité des Stations de Sports d'Hiver) et autres acteurs de la montagne.

Bulletin neige & avalanches par téléphone au 0 892 68 10 20 Service 0,35 € / min + prix appel

RÉPUBLIQUE FRANÇAISE
Liberté Égalité Fraternité

METEO FRANCE
À VOS CÔTÉS, DANS UN CLIMAT QUI CHANGE

Bulletin d'estimation du risque d'avalanche

(valable en dehors des pistes balisées et ouvertes)

MASSIF : Vercors

Rédigé le mardi 3 février 2026 à 16h

Conditions nivo-météo des 7 derniers jours

	mer. 28/01				jeu. 29/01				ven. 30/01				sam. 31/01				dim. 01/02				lun. 02/02				mar. 03/02			
	03h	09h	15h	21h	03h	09h	15h	21h	03h	09h	15h	21h	03h	09h	15h	21h	03h	09h	15h	21h	03h	09h	15h	21h	03h	09h	15h	21h
Météo																												
Vent (km/h)	20	30	40	45	45	25	15	30	45	35	25	20	20	15	20	20	20	20	20	20	25	55	80	120	125	90	75	70
à 2000m																												
Vent (km/h)	10	15	15	15	20	5	0	15	30	20	15	15	15	10	15	10	15	15	15	15	15	35	65	100	110	75	55	50
à 1500m																												

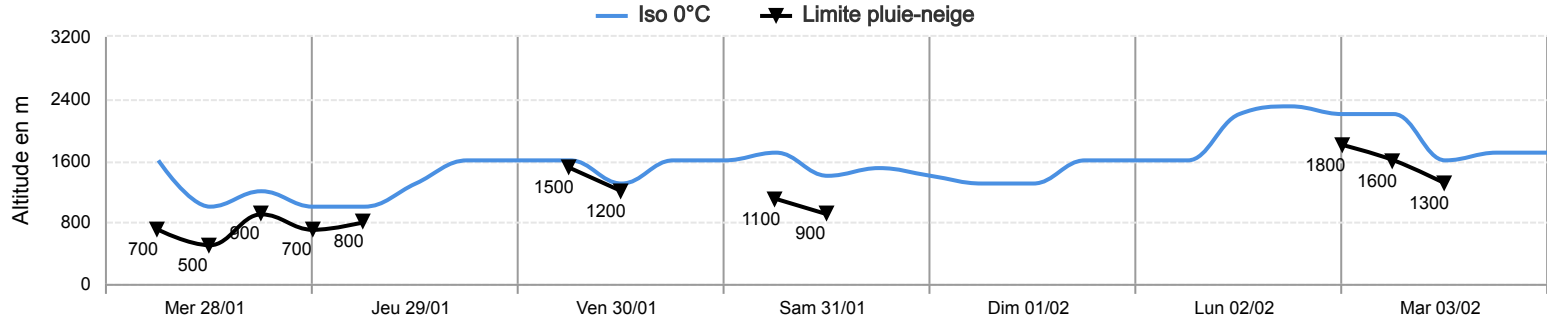

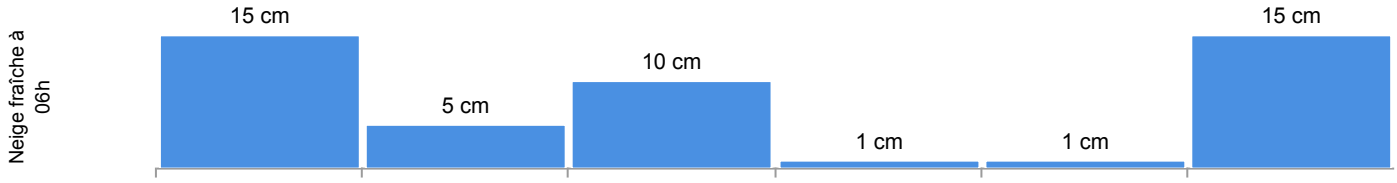

Risque d'avalanche	mer. 28/01	jeu. 29/01	ven. 30/01	sam. 31/01	dim. 01/02	lun. 02/02	mar. 03/02
	3	3	3	2	2	3	3

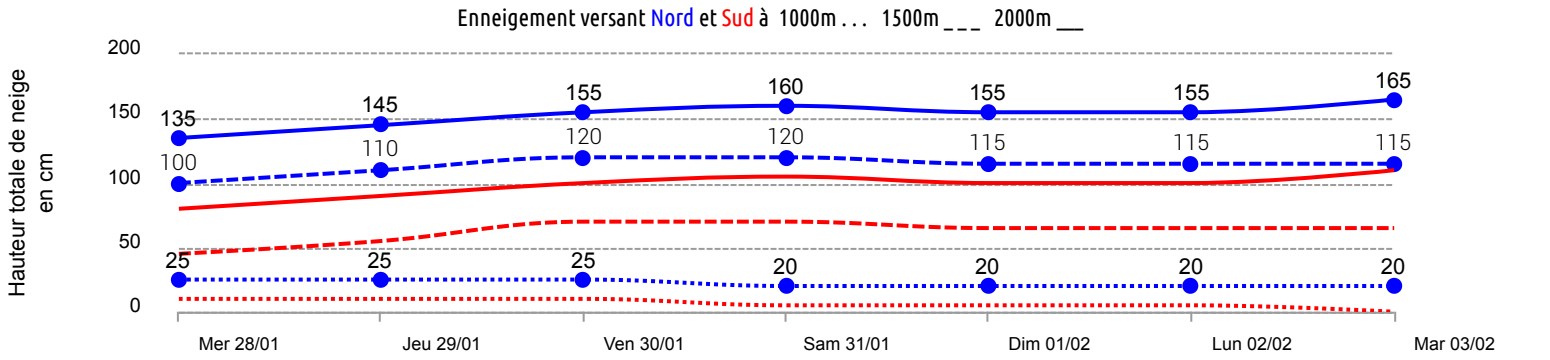

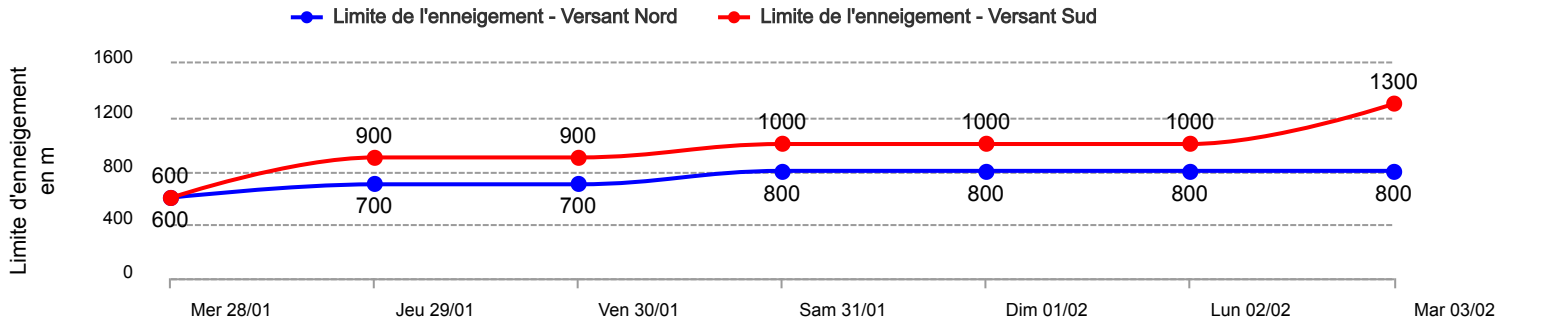

Pour consulter la vigilance en cours, veuillez vous rendre sur le site https://vigilance.meteofrance.fr/fr

Météo-France - 73 avenue de Paris, 94165 Saint-Mandé cedex - Contact : contact@meteo.fr

Rédigé par Météo-France avec la contribution des observateurs du réseau nivo-météorologiques. Partenariat : ANMSM (Maires de Stations de Montagne), DSF (Domaines Skiables de France), ADSP (Directeurs de Pistes et de la Sécurité des Stations de Sports d'Hiver) et autres acteurs de la montagne.

Bulletin neige & avalanches par téléphone au

0 892 68 10 20 Service 0,35 € / min + prix appel