Bulletin d'estimation du risque d'avalanche

(valable en dehors des pistes balisées et ouvertes)

MASSIF : Champsaur

Rédigé le mardi 3 février 2026 à 17h

Estimation des risques pour le : MERCREDI 04 FÉVRIER

PLAQUES ENCORE FACILES À DÉCLENCHER SUITE AU TRANSPORT DE NEIGE PAR LE VENT

3

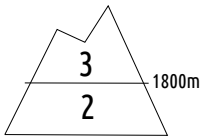

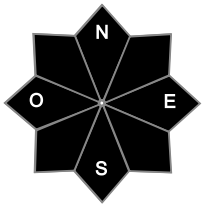

Au-dessus de 1800m indice de risque marqué, plus bas indice limité.

Départs spontanés : en plaques ou en neige récente humidifiée.

Déclenchements provoqués : plaques sensibles au passage d'un skieur, principalement au-dessus de 1800/2000 m.

Indices de risque : 5 très fort - 4 fort - 3 marqué - 2 limité - 1 faible -- En noir : les pentes les plus dangereuses

Stabilité du manteau neigeux

Situation avalancheuse typique :

neige ventée

couche fragile persistante

Déclenchements provoqués : le manteau neigeux reste instable, avec une double problématique de plaques, principalement au-dessus de 1800/2000 m :
- des plaques récentes sont en place dans les pentes où le vent fort a transporté et accumulé la neige récente. Elles peuvent céder au passage d'un seul skieur et engendrer des avalanches petites à moyennes (taille 1 à 2). Cassures pouvant être assez larges quand la topographie de la pente s'y prête.
- des plaques plus anciennes, essentiellement dans les pentes ouest, nord à est, masquées par la couche de neige récente. Elles sont moins fréquentes et plus difficiles à déclencher, mais les cassures sont alors épaisses en cas de départ. Avalanches moyennes à grandes (taille 2 à 3). Une première plaque de surface peut faciliter le départ d'une de ces plaques plus épaisses en contrebas.

Sous 1800/2000 m, le manteau neigeux a souvent été en partie humidifié/regelé, limitant la probabilité de déclencher une plaque.

Départs spontanés : - quelques départs de plaques possibles, suite au transport de neige par le vent. Avalanches petites à moyennes (taille 1 à 2). Une grande (taille 3) non exclue en cas de déclenchement d'une couche fragile persistante enfouie, suite à un premier départ de surface.
- Quelques avalanches de neige récente humidifiée, départs près des rochers. Taille 1, voire 2 si la topographie est favorable.

Qualité de la neige

L'enneigement est légèrement excédentaire pour un début février.
Données observées : 40 cm au hameau des Portes dans le Valgaudemar à 1270 m, 94 cm à la Nivôse d'Orcières à 2280 m, et 144 cm au-dessus de Prapic à 2480 m.

Limite d'enneigement skiable : dès les fonds de vallées, mais avec une sous-couche un peu limite en adrets sous 1600 m.

État de la neige de surface : 20/30 cm de neige récente au-dessus de 2000/2200 m, souvent densifiée ou durcie par le vent, mais encore poudreuse dans les pentes abritées. En sud suffisamment raide, fine croûte possible suite aux éclaircies de ce mardi.

Aperçu météo pour le mercredi 04 février

	nuit	matin	après-midi	soir

Éclaircies et passages nuageux, quelques flocons le soir. Vent de sud modéré sur les sommets et tournant à l'ouest la nuit suivante.

Pluie-Neige				1 000 m
Iso 0 °C	1 600 m	1 500 m	1 500 m	1 400 m
Vent 2000 m	↖ 20 km/h	↖ 20 km/h	↖ 15 km/h	↖ 10 km/h
Vent 3000 m	↖ 20 km/h	↖ 30 km/h	↖ 20 km/h	↗ 30 km/h

Épaisseur de neige hors-piste

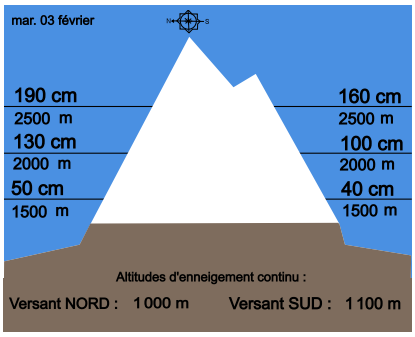

Précipitations à 1800 m

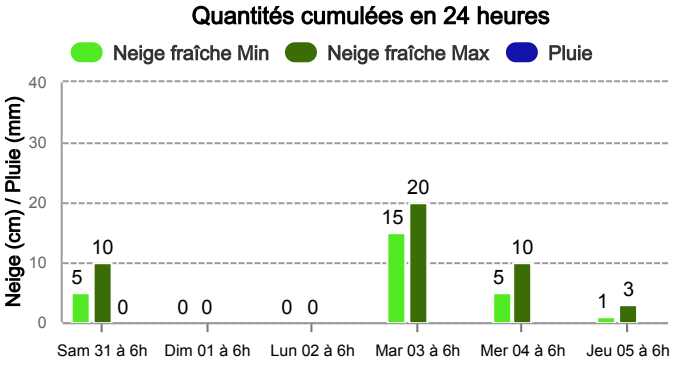

Tendance du jeudi 05 février

3

Indice de risque marqué

Lente stabilisation du manteau neigeux.
Encore des plaques pouvant céder au passage d'un seul skieur.

Pour consulter la vigilance en cours, veuillez vous rendre sur le site https://vigilance.meteofrance.fr/fr

Météo-France - 73 avenue de Paris, 94165 Saint-Mandé cedex - Contact : contact@meteo.fr

Rédigé par Météo-France avec la contribution des observateurs du réseau nivo-météorologiques. Partenariat : ANMSM (Maires de Stations de Montagne), DSF (Domaines Skiables de France), ADSP (Directeurs de Pistes et de la Sécurité des Stations de Sports d'Hiver) et autres acteurs de la montagne.

Bulletin neige & avalanches par téléphone au 0 892 68 10 20 Service 0,35 € / min + prix appel

RÉPUBLIQUE FRANÇAISE
Liberté Égalité Fraternité

METEO FRANCE
À VOS CÔTÉS, DANS UN CLIMAT QUI CHANGE

Bulletin d'estimation du risque d'avalanche

(valable en dehors des pistes balisées et ouvertes)

MASSIF : Champsaur

Rédigé le mardi 3 février 2026 à 17h

Conditions nivo-météo des 7 derniers jours

	mer. 28/01				jeu. 29/01				ven. 30/01				sam. 31/01				dim. 01/02				lun. 02/02				mar. 03/02			
	03h	09h	15h	21h	03h	09h	15h	21h	03h	09h	15h	21h	03h	09h	15h	21h	03h	09h	15h	21h	03h	09h	15h	21h	03h	09h	15h	21h
Météo																												
Vent (km/h)	60	50	35	50	40	30	20	15	20	30	40	25	20	20	10	10	10	10	25	45	35	25	50	80	100	70	40	25
à 3000m	↑	↗	↘	↓	↓	↓	→	↘	↘	↘	↘	→	↖	←	→	↘	↘	↘	→	→	→	↗	↗	↑	↑	↑	↗	↖
Vent (km/h)	45	35	35	40	30	20	15	10	10	20	25	15	10	10	10	10	10	10	15	20	20	10	20	35	50	35	20	15
à 2000m	↖	↘	↘	↓	↓	↘	→	↘	↘	↘	↘	←	←	←	→	↓	↓	↘	→	↘	→	↑	↖	↖	↖	↑	↑	↖

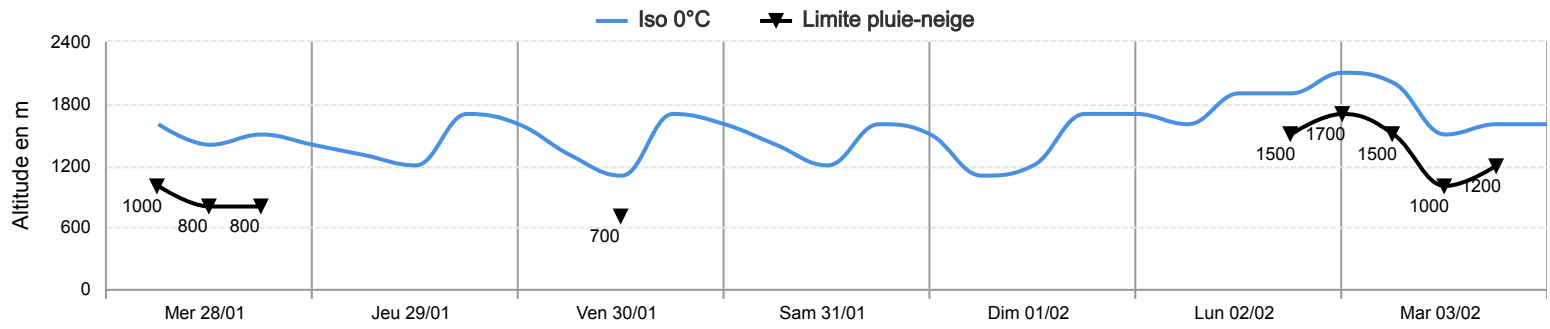

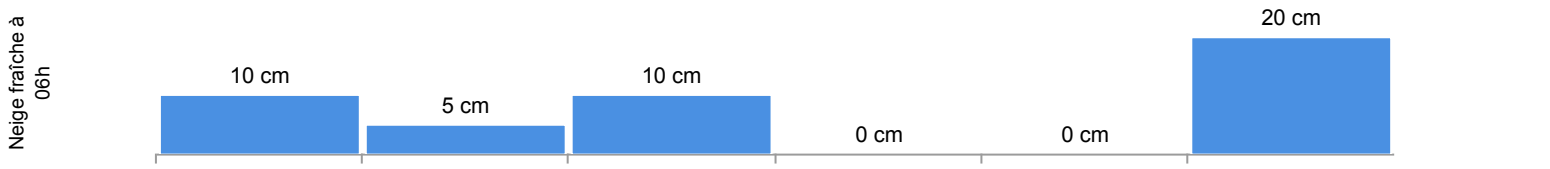

Risque d'avalanche	mer. 28/01	jeu. 29/01	ven. 30/01	sam. 31/01	dim. 01/02	lun. 02/02	mar. 03/02
	4	4	4	3	3	3	4

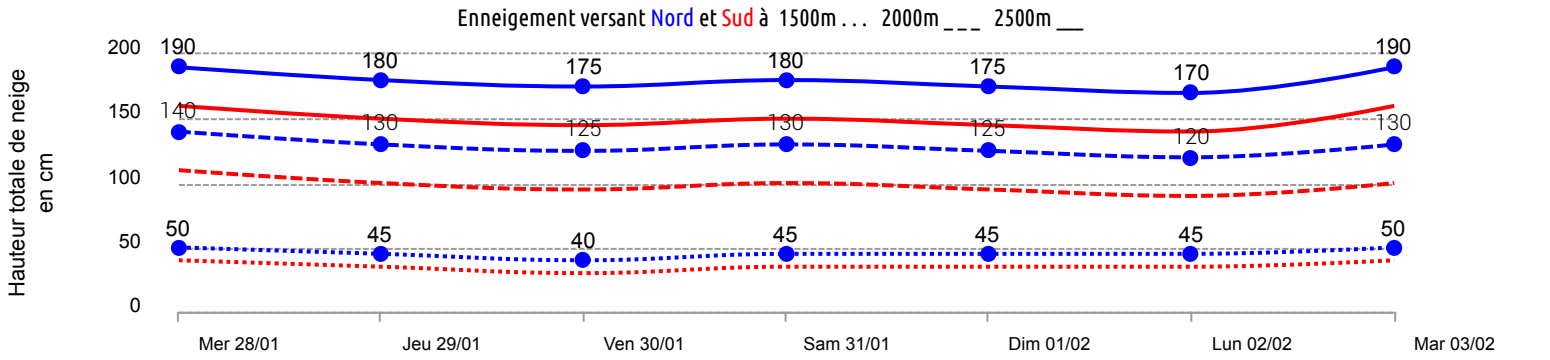

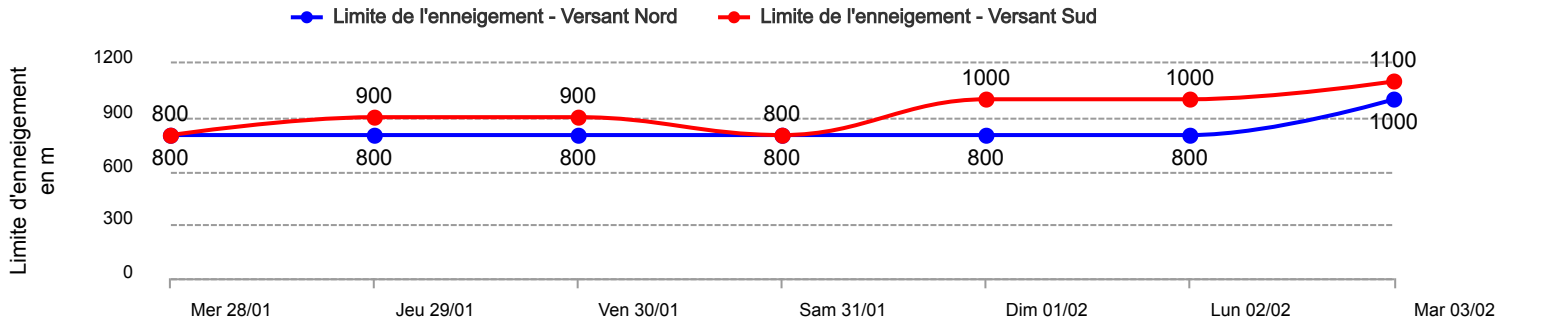

Pour consulter la vigilance en cours, veuillez vous rendre sur le site https://vigilance.meteofrance.fr/fr

Météo-France - 73 avenue de Paris, 94165 Saint-Mandé cedex - Contact : contact@meteo.fr

Bulletin neige & avalanches par téléphone au

0 892 68 10 20 Service 0,35 € / min + prix appel

Rédigé par Météo-France avec la contribution des observateurs du réseau nivo-météorologiques. Partenariat : ANMSM (Maires de Stations de Montagne), DSF (Domaines Skiables de France), ADSP (Directeurs de Pistes et de la Sécurité des Stations de Sports d'Hiver) et autres acteurs de la montagne.