Bulletin d'estimation du risque d'avalanche
(valable en dehors des pistes balisées et ouvertes)

MASSIF : Devoluy

Rédigé le mardi 3 février 2026 à 17h

Estimation des risques pour le : MERCREDI 04 FÉVRIER

PLAQUES ENCORE FACILES À DÉCLENCHER SUITE AU TRANSPORT DE NEIGE PAR LE VENT

3

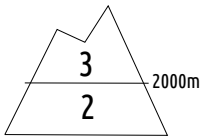

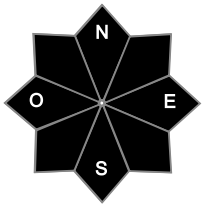

Au-dessus de 2000m indice de risque marqué, plus bas indice limité.

Départs spontanés : en plaques ou en neige récente humidifiée.

Déclenchements provoqués : plaques sensibles au passage d'un skieur, principalement au-dessus de 2000 m.

Indices de risque : 5 très fort - 4 fort - 3 marqué - 2 limité - 1 faible -- En noir : les pentes les plus dangereuses

Stabilité du manteau neigeux

Situation avalancheuse typique : neige ventée couche fragile persistante

Déclenchements provoqués : au-dessus de 2000 m environ, des plaques sont en place dans les pentes où le vent fort a transporté et accumulé la neige récente. Elles peuvent céder au passage d'un seul skieur et engendrer des avalanches petites à moyennes (taille 1 à 2). Une grande avalanche (taille 3) non exclue, en cas de rupture sur une couche fragile persistante enfouie. Déclenchement plutôt difficile, mais pouvant être provoqué par le départ d'une première avalanche de surface.

Sous 2000 m, le manteau neigeux a souvent été en partie humidifié/regelé, limitant la probabilité de déclencher une plaque.

Départs spontanés : - quelques départs de plaques possibles, suite au transport de neige par le vent. Avalanches petites à moyennes (taille 1 à 2). Une grande (taille 3) non exclue en cas de déclenchement "en cascade", suite à un premier départ de surface.
- quelques avalanches de neige récente humidifiée, départs près des rochers. Taille 1, voire 2 si la topographie est favorable.

Qualité de la neige

L'enneigement est plutôt excédentaire pour un début février.

Limite d'enneigement skiable : vers 1000/1200 m en ubacs. Sous-couche un peu limite en adrets sous 1400/1500 m.

État de la neige de surface : neige récente irrégulièrement répartie suite au vent fort, souvent densifiée ou durcie, mais encore poudreuse dans les pentes abritées. En sud suffisamment raide, fine croûte possible suite aux éclaircies de ce mardi.

Aperçu météo pour le mercredi 04 février

	nuit	matin	après-midi	soir

Éclaircies et passages nuageux, quelques flocons le soir. Vent de sud faiblissant progressivement et tournant à l'ouest la nuit suivante.

Pluie-Neige				900 m
Iso 0 °C	1 600 m	1 500 m	1 500 m	1 300 m
Vent 2000 m	↑ 35 km/h	↑ 40 km/h	↑ 35 km/h	↑ 20 km/h
Vent 3000 m	↑ 40 km/h	↑ 50 km/h	↗ 35 km/h	→ 25 km/h

Épaisseur de neige hors-piste

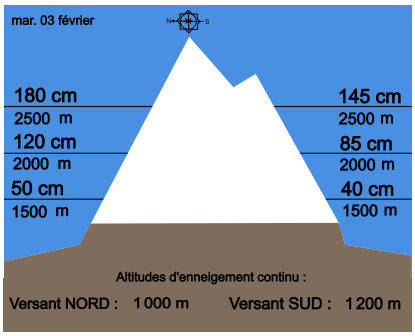

Précipitations à 1800 m

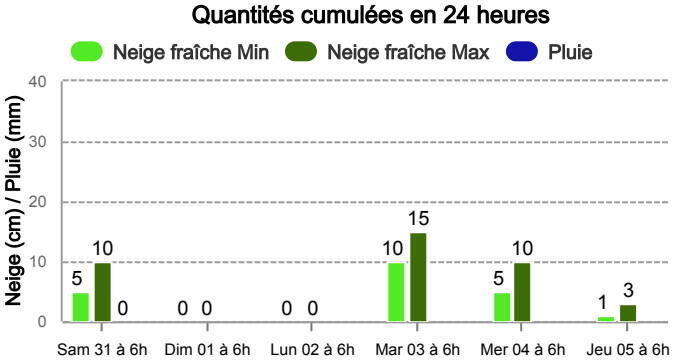

Tendance du jeudi 05 février

3

Indice de risque marqué

Lente stabilisation du manteau neigeux. Encore des plaques pouvant céder au passage d'un seul skieur.

Pour consulter la vigilance en cours, veuillez vous rendre sur le site https://vigilance.meteofrance.fr/fr

Météo-France - 73 avenue de Paris, 94165 Saint-Mandé cedex - Contact : contact@meteo.fr

Rédigé par Météo-France avec la contribution des observateurs du réseau nivo-météorologiques. Partenariat : ANMSM (Maires de Stations de Montagne), DSF (Domaines Skiables de France), ADSP (Directeurs de Pistes et de la Sécurité des Stations de Sports d'Hiver) et autres acteurs de la montagne.

Bulletin neige & avalanches par téléphone au
0 892 68 10 20 Service 0,35 € / min + prix appel

RÉPUBLIQUE FRANÇAISE
Liberté Égalité Fraternité

METEO FRANCE
À VOS CÔTÉS, DANS UN CLIMAT QUI CHANGE

Bulletin d'estimation du risque d'avalanche
(valable en dehors des pistes balisées et ouvertes)

MASSIF : Devoluy

Rédigé le mardi 3 février 2026 à 17h

Conditions nivo-météo des 7 derniers jours

	mer. 28/01				jeu. 29/01				ven. 30/01				sam. 31/01				dim. 01/02				lun. 02/02				mar. 03/02			
	03h	09h	15h	21h	03h	09h	15h	21h	03h	09h	15h	21h	03h	09h	15h	21h	03h	09h	15h	21h	03h	09h	15h	21h	03h	09h	15h	21h
Météo																												
Vent (km/h)	60	40	35	50	50	35	30	30	35	40	40	25	25	5	5	10	20	20	40	30	35	50	70	100	120	60	50	40
à 3000m																												
Vent (km/h)	40	30	25	50	50	30	20	15	15	30	25	15	15	15	15	10	20	20	15	10	10	25	45	80	70	45	35	35
à 2000m																												

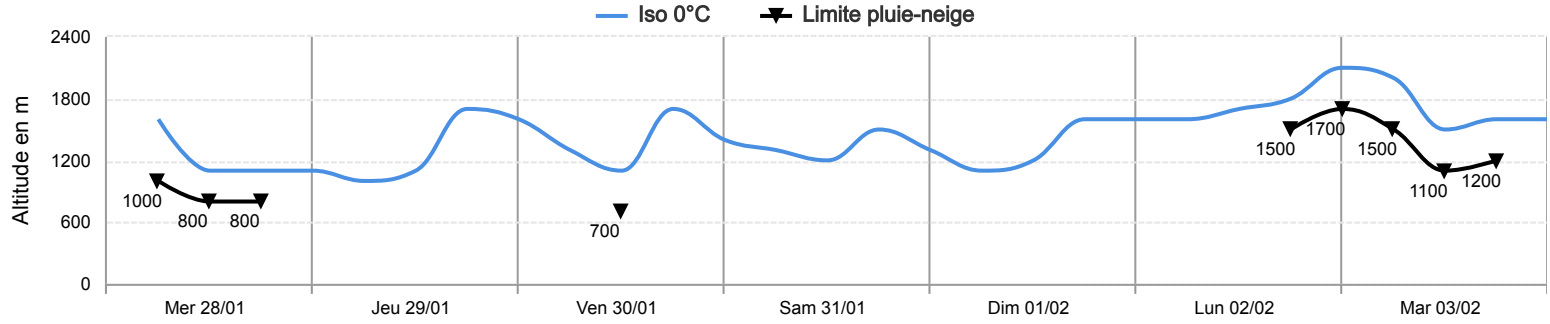

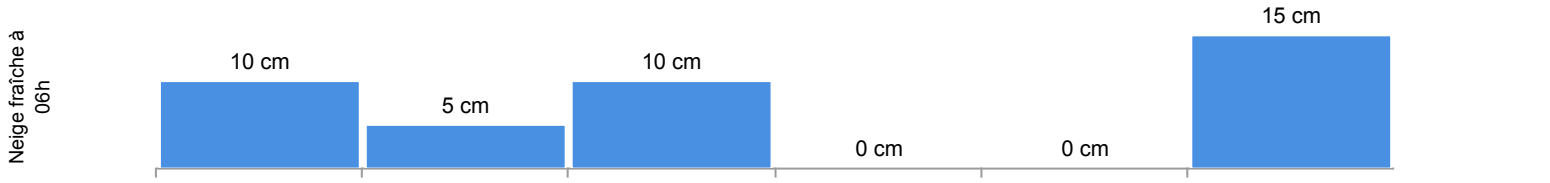

Risque d'avalanche	mer. 28/01	jeu. 29/01	ven. 30/01	sam. 31/01	dim. 01/02	lun. 02/02	mar. 03/02
	4	4	4	3	3	3	4

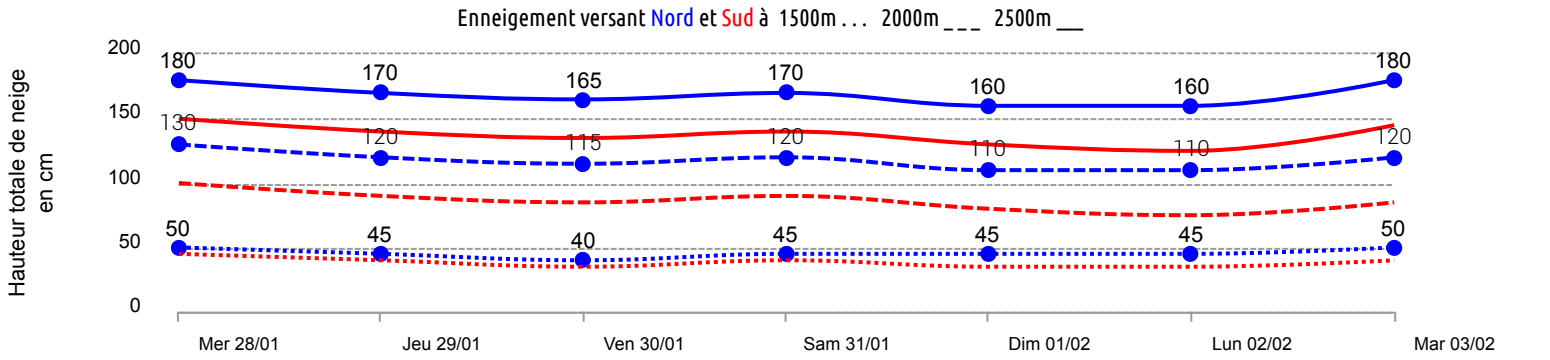

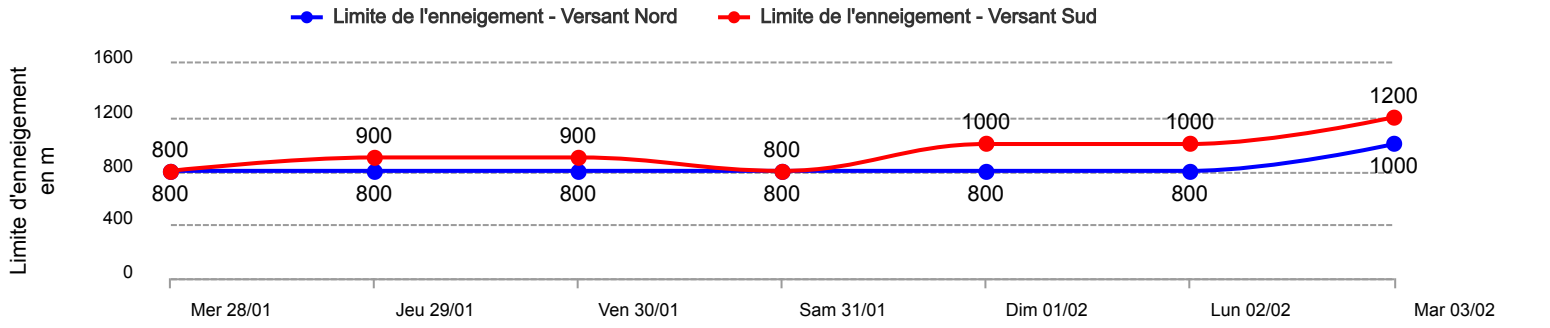

Pour consulter la vigilance en cours, veuillez vous rendre sur le site https://vigilance.meteofrance.fr/fr

Météo-France - 73 avenue de Paris, 94165 Saint-Mandé cedex - Contact : contact@meteo.fr

Rédigé par Météo-France avec la contribution des observateurs du réseau nivo-météorologiques. Partenariat : ANMSM (Maires de Stations de Montagne), DSF (Domaines Skiables de France), ADSP (Directeurs de Pistes et de la Sécurité des Stations de Sports d'Hiver) et autres acteurs de la montagne.

Bulletin neige & avalanches par téléphone au
0 892 68 10 20 Service 0,35 € / min + prix appel