Bulletin d'estimation du risque d'avalanche
(valable en dehors des pistes balisées et ouvertes)

MASSIF : Pelvoux

Rédigé le mardi 3 février 2026 à 17h

Estimation des risques pour le : MERCREDI 04 FÉVRIER

NOMBREUSES PLAQUES ENCORE FACILES À DÉCLENCHER

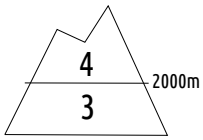

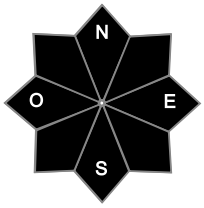

Au-dessus de 2000m indice de risque fort, plus bas indice marqué.

Départs spontanés : en plaques ou en neige récente humidifiée.

Déclenchements provoqués : plaques sensibles au passage d'un seul skieur, cassures parfois larges et/ou épaisses.

Indices de risque : 5 très fort - 4 fort - 3 marqué - 2 limité - 1 faible -- En noir : les pentes les plus dangereuses

Stabilité du manteau neigeux

Situation avalancheuse typique : neige fraîche couche fragile persistante

Déclenchements provoqués : le manteau neigeux est instable dans de nombreuses pentes, avec une double problématique de plaques :
- des plaques dans la neige fraîche souvent ventée sont en place. Elles peuvent facilement céder au passage d'un seul skieur et engendrer des avalanches moyennes à grandes (taille 2 à 3). Cassures pouvant être larges quand la topographie de la pente s'y prête, en particulier au-dessus de 2000 m.
- des plaques plus anciennes, masquées par la couche de neige récente, essentiellement dans les pentes ouest, nord à est, et même en forêt. Elles sont plus difficiles à déclencher, mais les cassures sont épaisses en cas de départ (potentiellement plus d'1 mètre). Avalanches moyennes à grandes (taille 2 à 3). Une première plaque de surface peut faciliter le départ d'une de ces plaques plus épaisses en contrebas.

Départs spontanés : - encore quelques départs de plaques possibles, dans les secteurs suffisamment ventés (chasse-neige visible). Avalanches moyennes (taille 2). Une grande (taille 3) possible en cas de déclenchement d'une couche fragile persistante enfouie, suite à un premier départ de surface.
- Avalanches de neige récente humidifiée, départs près des rochers. Taille 1 à 2 en général.

Qualité de la neige

L'enneigement est désormais excédentaire pour un début février.
Données observées : 177 cm à la Nivôse de Écrins vers 3000 m soufflée par le vent, 178 cm au Pré de Madame Carle à 1900 m, 117 cm au hameau de Dormillouse à 1730 m.

Limite d'enneigement skiable : dès les fonds de vallées, mais avec une sous-couche un peu limite sous 1500 m en adrets.

État de la neige de surface : 20/40 cm de neige récente, souvent densifiée ou durcie par le vent, mais encore poudreuse dans les pentes abritées. En sud suffisamment raide, fine croûte possible suite aux éclaircies de ce mardi.

Aperçu météo pour le mercredi 04 février

nuit	matin	après-midi	soir

Éclaircies et passages nuageux, quelques flocons le soir. Vent de sud modéré sur les sommets et tournant à l'ouest la nuit suivante.

Pluie-Neige				
Iso 0 °C	1 500 m	1 500 m	1 500 m	1 400 m
Vent 2000 m	15 km/h	15 km/h	15 km/h	10 km/h
Vent 3000 m	30 km/h	30 km/h	25 km/h	20 km/h

Épaisseur de neige hors-piste

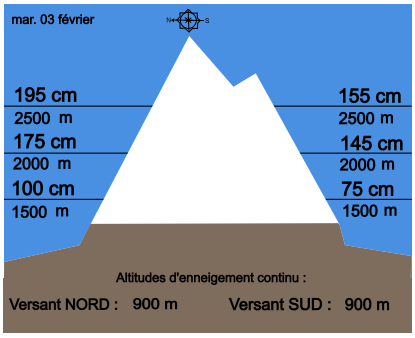

Précipitations à 1800 m

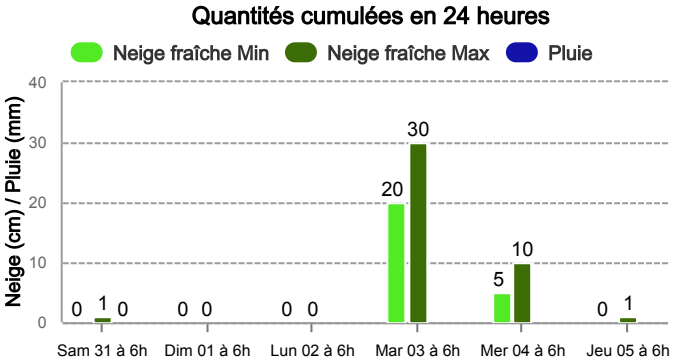

Tendance du jeudi 05 février

Indice de risque marqué

Lente stabilisation du manteau neigeux.
Encore des plaques pouvant céder au passage d'un seul skieur.

Pour consulter la vigilance en cours, veuillez vous rendre sur le site https://vigilance.meteofrance.fr/fr

Météo-France - 73 avenue de Paris, 94165 Saint-Mandé cedex - Contact : contact@meteo.fr

Rédigé par Météo-France avec la contribution des observateurs du réseau nivo-météorologiques. Partenariat : ANMSM (Maires de Stations de Montagne), DSF (Domaines Skiables de France), ADSP (Directeurs de Pistes et de la Sécurité des Stations de Sports d'Hiver) et autres acteurs de la montagne.

Bulletin neige & avalanches par téléphone au 0 892 68 10 20 Service 0,35 € / min + prix appel

RÉPUBLIQUE FRANÇAISE
Liberté Égalité Fraternité

METEO FRANCE
À VOS CÔTÉS, DANS UN CLIMAT QUI CHANGE

Bulletin d'estimation du risque d'avalanche
(valable en dehors des pistes balisées et ouvertes)

MASSIF : Pelvoux

Rédigé le mardi 3 février 2026 à 17h

Conditions nivo-météo des 7 derniers jours

	mer. 28/01				jeu. 29/01				ven. 30/01				sam. 31/01				dim. 01/02				lun. 02/02				mar. 03/02			
	03h	09h	15h	21h	03h	09h	15h	21h	03h	09h	15h	21h	03h	09h	15h	21h	03h	09h	15h	21h	03h	09h	15h	21h	03h	09h	15h	21h
Météo																												
Vent (km/h)	50	30	25	40	40	30	20	20	20	25	30	10	15	15	5	10	10	10	15	15	20	25	40	60	100	70	40	30
à 3000m																												
Vent (km/h)	30	15	15	25	30	20	15	10	10	10	20	10	10	10	10	10	10	10	10	10	10	15	20	20	60	35	25	15
à 2000m																												

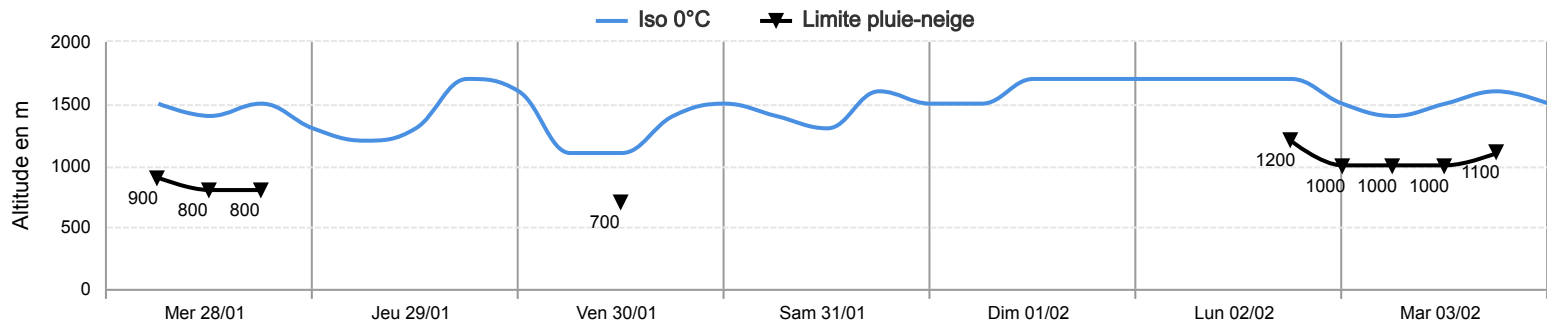

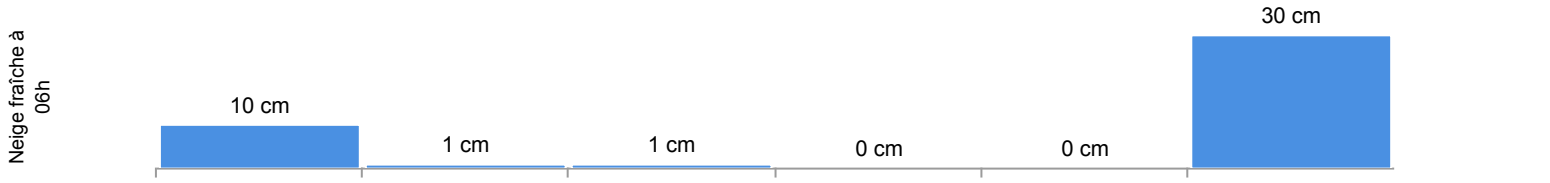

Risque d'avalanche	mer. 28/01	jeu. 29/01	ven. 30/01	sam. 31/01	dim. 01/02	lun. 02/02	mar. 03/02
	4	4	4	3	3	3	4

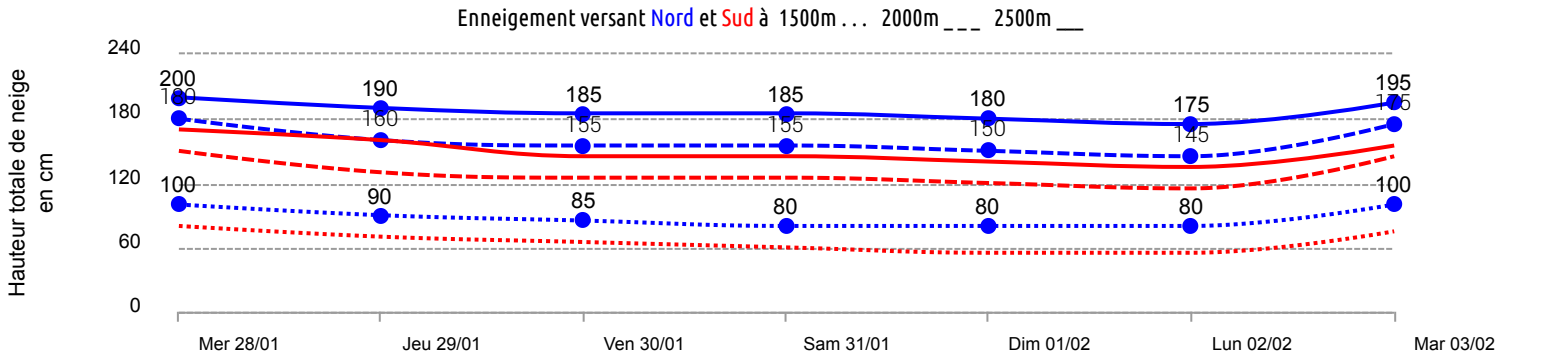

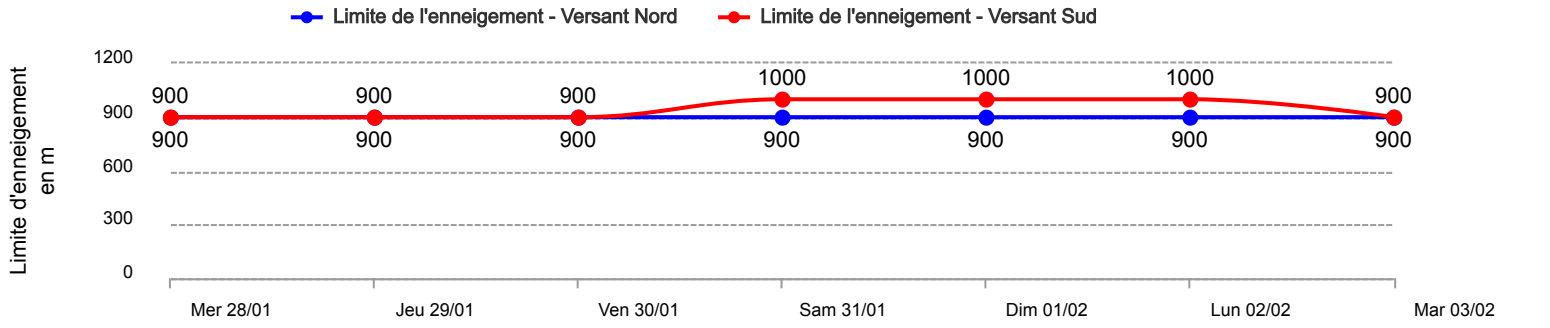

Pour consulter la vigilance en cours, veuillez vous rendre sur le site https://vigilance.meteofrance.fr/fr

Météo-France - 73 avenue de Paris, 94165 Saint-Mandé cedex - Contact : contact@meteo.fr

Rédigé par Météo-France avec la contribution des observateurs du réseau nivo-météorologiques. Partenariat : ANMSM (Maires de Stations de Montagne), DSF (Domaines Skiables de France), ADSP (Directeurs de Pistes et de la Sécurité des Stations de Sports d'Hiver) et autres acteurs de la montagne.

Bulletin neige & avalanches par téléphone au

0 892 68 10 20 Service 0,35 € / min + prix appel