Bulletin d'estimation du risque d'avalanche
(valable en dehors des pistes balisées et ouvertes)

MASSIF : Queyras

Rédigé le mardi 3 février 2026 à 17h

Estimation des risques pour le : MERCREDI 04 FÉVRIER

NOMBREUSES PLAQUES ENCORE FACILES À DÉCLENCHER

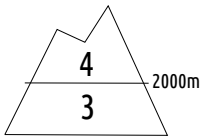

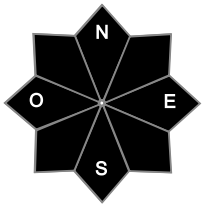

Au-dessus de 2000m indice de risque fort, plus bas indice marqué.

Départs spontanés : en plaques ou en neige récente humidifiée.

Déclenchements provoqués : plaques sensibles au passage d'un seul skieur, cassures parfois larges et/ou épaisses.

Indices de risque : 5 très fort - 4 fort - 3 marqué - 2 limité - 1 faible -- En noir : les pentes les plus dangereuses

Stabilité du manteau neigeux

Situation avalancheuse typique : neige ventée couche fragile persistante

Déclenchements provoqués : le manteau neigeux reste instable dans de nombreuses pentes, avec une double problématique de plaques :
- des plaques récentes sont en place dans les pentes où le vent fort a transporté et accumulé la neige récente. Elles peuvent céder au passage d'un seul skieur et engendrer des avalanches petites à moyennes (taille 1 à 2). Cassures pouvant être larges quand la topographie de la pente s'y prête.
- des plaques plus anciennes, souvent masquées par la petite couche de neige récente, essentiellement dans les pentes ouest, nord à est. Elles restent faciles à déclencher dans de nombreux secteurs, avec des cassures pouvant être épaisses, en particulier au-dessus de 2000 m. Avalanches moyennes à grandes (taille 2 à 3). Une première plaque de surface peut faciliter le départ d'une de ces plaques plus épaisses en contrebas.

Départs spontanés : - quelques départs de plaques possibles, suite au transport de neige par le vent. Avalanches petites à moyennes (taille 1 à 2). Une grande (taille 3) possible en cas de déclenchement d'une couche fragile persistante enfouie, suite à un premier départ de surface.
- Avalanches de neige récente humidifiée, départs près des rochers. Taille 1 en général.

Qualité de la neige

L'enneigement est proche des normales dans les ubacs, mais reste déficitaire dans les adrets d'altitude.
Données observées : 138 cm en versant nord du col Izoard à 2300 m, 60 cm à la Nivôse du Col Agnel à 2630 m, 56 cm à Ristolas à 1670 m.

Limite d'enneigement skiable : dès 1000/1200 m en ubacs, plutôt 1500/1700 m en adrets avec très peu de sous-couche jusqu'à haute altitude.

État de la neige de surface : 15/20 cm de neige récente selon les secteurs, souvent densifiée ou durcie par le vent, mais encore poudreuse dans les pentes abritées. En sud suffisamment raide, fine croûte possible suite aux éclaircies de ce mardi.

Aperçu météo pour le mercredi 04 février

	nuit	matin	après-midi	soir

Ciel chargé sur la frontière italienne, éclaircies et passages nuageux ailleurs, quelques flocons. Vent d'est à sud-est modéré sur les sommets, tournant à l'ouest la nuit suivante.

Pluie-Neige				
Iso 0 °C	1 600 m	1 400 m	1 400 m	1 400 m
Vent 2000 m	↖ 15 km/h	← 20 km/h	← 15 km/h	→ 10 km/h
Vent 3000 m	↖ 30 km/h	← 30 km/h	↖ 25 km/h	→ 30 km/h

Épaisseur de neige hors-piste

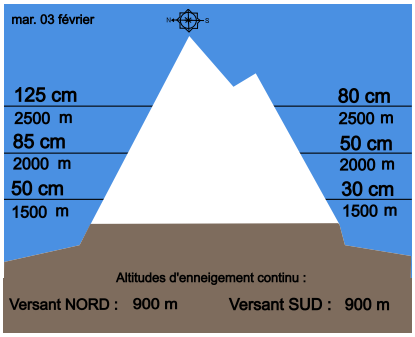

Précipitations à 1800 m

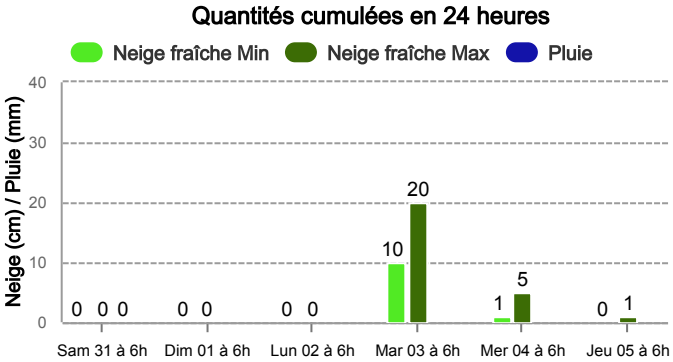

Tendance du jeudi 05 février

Indice de risque marqué

Lente stabilisation du manteau neigeux. Encore des plaques pouvant céder au passage d'un seul skieur.

Pour consulter la vigilance en cours, veuillez vous rendre sur le site https://vigilance.meteofrance.fr/fr

Météo-France - 73 avenue de Paris, 94165 Saint-Mandé cedex - Contact : contact@meteo.fr

Rédigé par Météo-France avec la contribution des observateurs du réseau nivo-météorologiques. Partenariat : ANMSM (Maires de Stations de Montagne), DSF (Domaines Skiables de France), ADSP (Directeurs de Pistes et de la Sécurité des Stations de Sports d'Hiver) et autres acteurs de la montagne.

Bulletin neige & avalanches par téléphone au **0 892 68 10 20** Service 0,35 € / min + prix appel

RÉPUBLIQUE FRANÇAISE
Liberté Égalité Fraternité

METEO FRANCE
À VOS CÔTÉS, DANS UN CLIMAT QUI CHANGE

Bulletin d'estimation du risque d'avalanche
(valable en dehors des pistes balisées et ouvertes)

MASSIF : Queyras

Rédigé le mardi 3 février 2026 à 17h

Conditions nivo-météo des 7 derniers jours

	mer. 28/01				jeu. 29/01				ven. 30/01				sam. 31/01				dim. 01/02				lun. 02/02				mar. 03/02			
	03h	09h	15h	21h	03h	09h	15h	21h	03h	09h	15h	21h	03h	09h	15h	21h	03h	09h	15h	21h	03h	09h	15h	21h	03h	09h	15h	21h
Météo																												
Vent (km/h)	50	40	30	45	45	30	25	20	20	30	35	25	20	30	20	15	15	15	15	15	20	30	40	60	80	60	40	40
à 3000m																												
Vent (km/h)	30	25	20	20	25	20	15	10	10	15	25	15	10	15	10	10	5	10	15	10	10	10	20	30	40	35	25	15
à 2000m																												

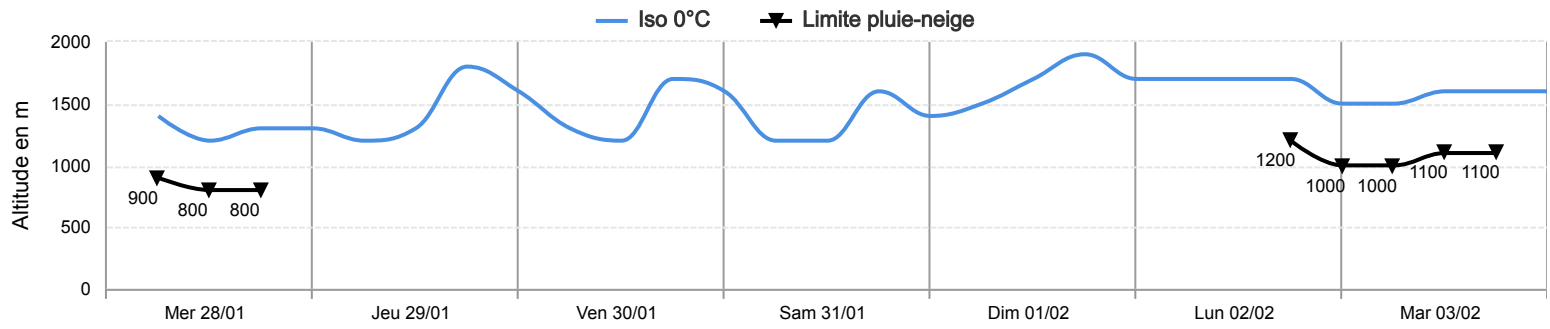

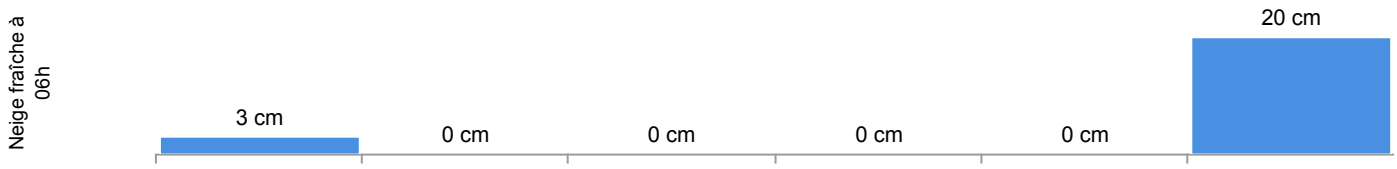

Risque d'avalanche	mer. 28/01	jeu. 29/01	ven. 30/01	sam. 31/01	dim. 01/02	lun. 02/02	mar. 03/02
	4	4	4	3	3	3	4

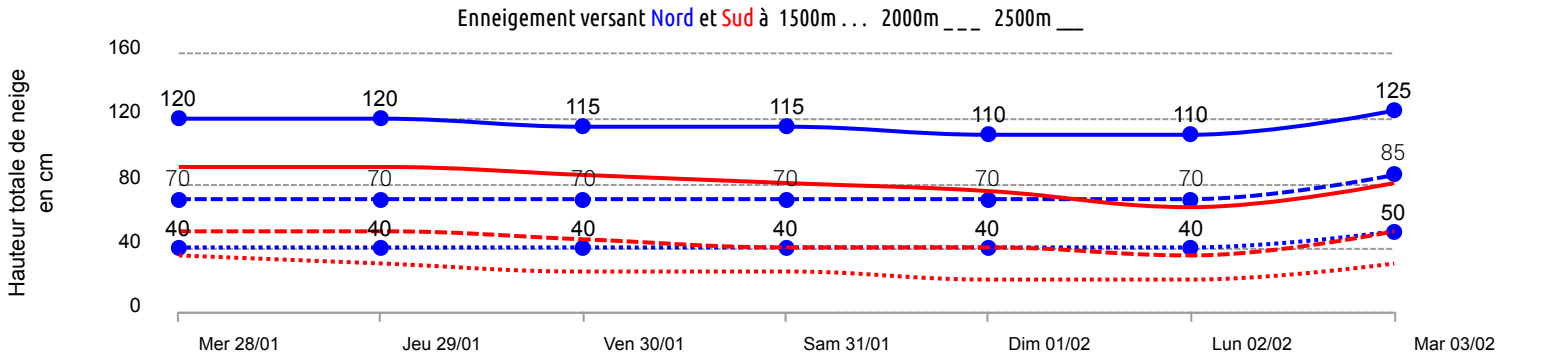

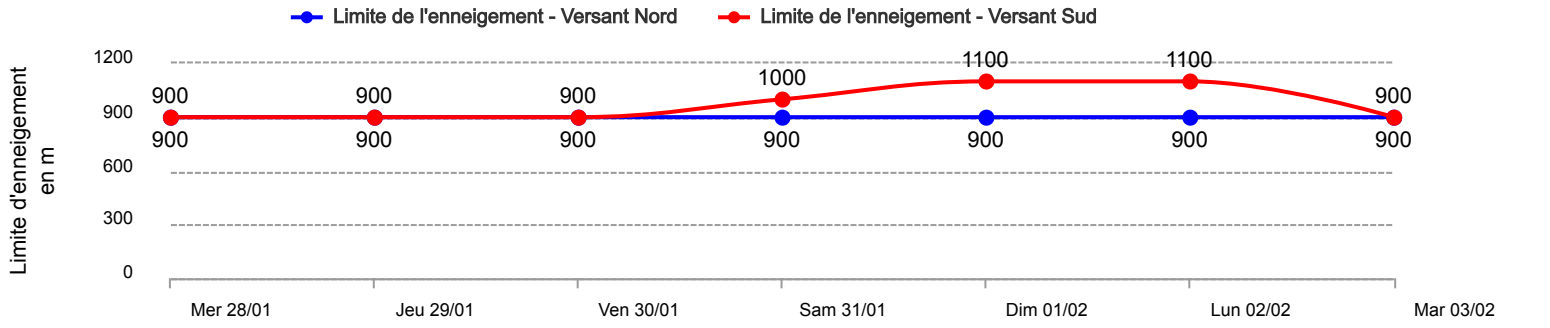

Pour consulter la vigilance en cours, veuillez vous rendre sur le site https://vigilance.meteofrance.fr/fr

Météo-France - 73 avenue de Paris, 94165 Saint-Mandé cedex - Contact : contact@meteo.fr

Bulletin neige & avalanches par téléphone au

0 892 68 10 20 Service 0,35 € / min + prix appel

Rédigé par Météo-France avec la contribution des observateurs du réseau nivo-météorologiques. Partenariat : ANMSM (Maires de Stations de Montagne), DSF (Domaines Skiables de France), ADSP (Directeurs de Pistes et de la Sécurité des Stations de Sports d'Hiver) et autres acteurs de la montagne.