GOBIERNO DE ESPAÑA
VICEPRESIDENCIA TERCERA DEL GOBIERNO
MINISTERIO PARA LA TRANSICIÓN ECOLÓGICA Y EL RETO DEMOGRÁFICO

Boletín de información nivológica y de peligro de aludes

Pirineo Catalán

aemet Agencia Estatal de Meteorología

miércoles, 4 de febrero de 2026

Pronóstico hasta las 24 horas del jueves, día 5 de febrero

(Válido fuera de pistas de esquí balizadas y abiertas)

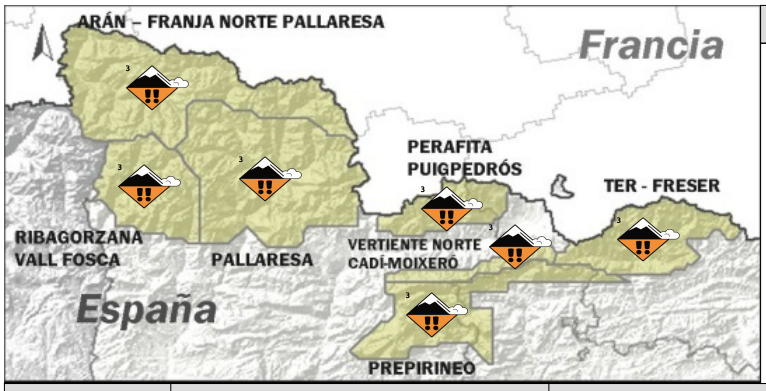

Problemas de aludes

Placas de viento

Nieve húmeda

Macizo	Peligro	Problemas de aludes, cota, orientación, tamaño	Innivación observada (m)
Arán - Franja norte Pallaresa	3 Notable	Placas de viento: 2000, N O E S, 3 Nieve húmeda: 2000, N O E S, 2	2026-02-04 N S Cotas bajas
Ribagorzana - Vall Fosca	3 Notable	Placas de viento: 2000, N O E S, 3 Nieve húmeda: 2000, N O E S, 2	2026-02-04 N S Cotas bajas
Pallaresa	3 Notable	Placas de viento: 2000, N O E S, 3 Nieve húmeda: 2000, N O E S, 2	2026-02-04 N S Cotas bajas

AEMET. Se autoriza la reproducción de su contenido citando la fuente.

Boletín de información nivológica y de peligro de aludes

Pirineo Catalán

Perafita - Puigpedrós	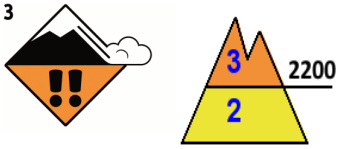 **Notable**	**Placas de viento** 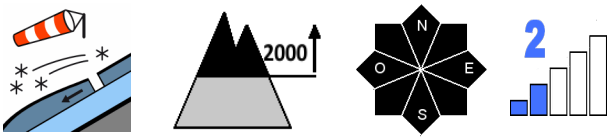 **Nieve húmeda** 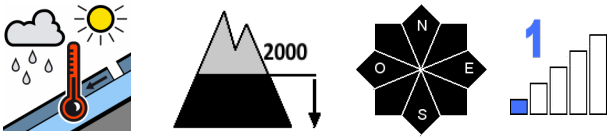	2026-02-04 Cotas bajas
Ter - Freser	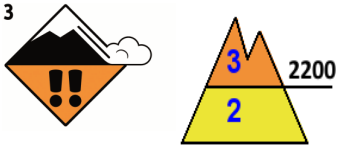 **Notable**	**Placas de viento** 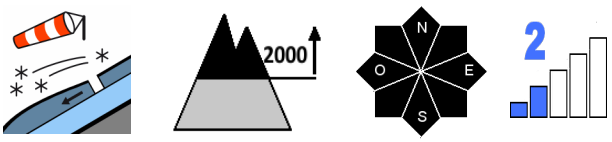 **Nieve húmeda** 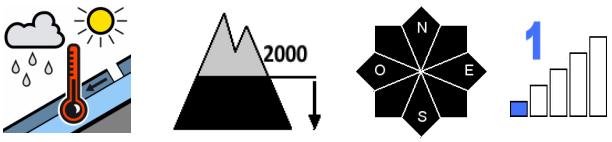	2026-02-04 Cotas bajas
Vertiente norte Cadí - Moixeró	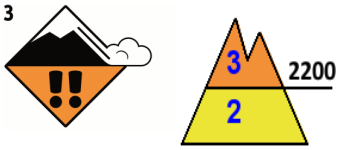 **Notable**	**Placas de viento** 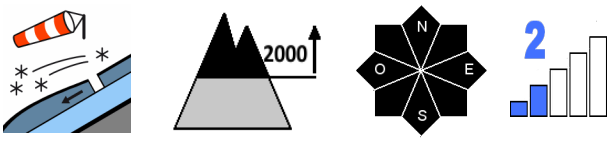 **Nieve húmeda** 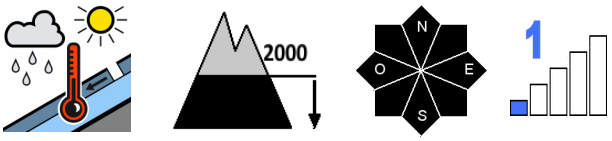	2026-02-04 Cotas bajas
Prepirineo	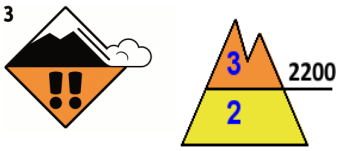 **Notable**	**Placas de viento** 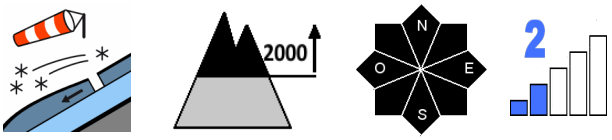 **Nieve húmeda** 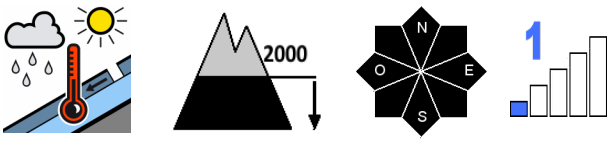	2026-02-04 Cotas bajas

Estado del manto y observaciones recientes

El paso de sucesivas borrascas está dejando precipitaciones en la cordillera, alternándose registros significativos con cantidades más discretas. La cota de nieve también ha fluctuado, si bien, por encima de unos 1800-2000 metros las precipitaciones han sido mayoritariamente sólidas. En las 24 horas anteriores a las 08 UTC de hoy ha nevado débilmente a partir de unos 1100-1200 metros, con acumulaciones de 1-5 l/m2, ocasionalmente algo más, lo que ha supuesto incrementos de nieve nueva de unos pocos cm en algunos enclaves, mientras que en otros, debido al viento, se han producido reducciones de unos 5 cm. Estas cantidades se

AEMET. Se autoriza la reproducción de su contenido citando la fuente.

incrementarán ligeramente durante el día de hoy por encima de unos 1400-1500 metros.

El manto es continuo desde cotas bajas, con espesores que rondan los 120-180 cm a unos 2100-2200 metros, aunque presentan mucha variabilidad debido a la acción del viento, superándose ampliamente estas cifras en ventisqueros y zonas de acumulación. En la mayoría de sectores, estos valores están en máximos para lo que cabría esperar para las fechas en que nos encontramos.

En cotas altas, la nieve presenta muy grandes acumulaciones, manteniéndose seca y muy venteada en superficie, al tiempo que, en umbrías, se observan estratos débiles internos, así como una antigua capa débil persistente en la base del manto. En cotas inferiores la nieve está más humedecida, debido a las lluvias del lunes, aunque con el descenso de la cota de nieve, la superficie vuelve a presentarse seca.

Evolución del manto y peligro de aludes para el jueves, día 5

Problema de nieve reciente, placas de viento y capas débiles persistentes en cotas altas. Problema de nieve húmeda y deslizamientos basales en cotas bajas.

Mañana, jueves, van a continuar las precipitaciones, ascendiendo la cota de nieve hasta unos 1800-2000 metros en las horas centrales. De tal manera que por encima de esas altitudes en los macizos occidentales se sumarán otros 10-20 cm a los caídos hoy, localmente más, siendo las acumulaciones menos significativas en el sector oriental. En cotas inferiores las cantidades serán menores, ya que lloverá durante parte del periodo. Así, serán frecuentes las purgas de nieve reciente en las laderas suficientemente inclinadas de cotas altas, de tamaño pequeño (riesgo de caída) o mediano (capaz de enterrar a una persona), sin descartar que alguno pueda superar estas dimensiones en el área occidental. En cotas medias y bajas el manto se humidificará con las lluvias, por lo que se esperan aludes de nieve húmeda del mismo tamaño que los anteriores, incluso podría producirse algún deslizamiento basal en zonas herbosas o de piedra lisa, en cuyo caso podría movilizar más cantidad de nieve y llegar a ser grande.

El mayor peligro se sitúa en cotas altas. Seguirán soplando vientos fuertes de componentes oeste y sur, que nuevamente formarán placas en muchas orientaciones, aunque con preferencia en vertientes este y norte, que en ocasiones pueden localizarse alejadas de crestas y collados, así como quedar ocultas tras nevadas posteriores. Estas estructuras se sumarán a las generadas en episodios previos, que abarcan todas las orientaciones y que aún se mantienen inestables, pudiendo colapsar, tanto unas como otras, ante una sobrecarga débil (paso de un solo esquiador). Además, en las umbrías, no se descarta que las capas débiles persistentes sigan activas, especialmente en zonas de manto delgado. Ambos tipos de problemas podrán dar lugar a aludes de tamaño 2 o 3 (grande, capaz de destruir un vehículo).

Predicción meteorológica para el jueves, día 5

Intervalos nubosos de madrugada, aumentando pronto a muy nuboso o cubierto. Al final del día tenderá a disminuir la nubosidad, sobre todo en los macizos orientales, donde quedará poco nuboso. Periodos de visibilidad localmente reducida. Se esperan precipitaciones débiles o moderadas en el área occidental, sin descartar que localmente puedan ser persistentes, siendo menos intensas y frecuentes en la oriental. Cota de nieve en torno a 1500-1600 metros al inicio y final del día, ascendiendo transitoriamente a 1800-2000 metros en las horas

AEMET. Se autoriza la reproducción de su contenido citando la fuente.

centrales. No se descarta alguna tormenta ocasional. Temperaturas sin cambios o en ligero ascenso. Heladas débiles o moderadas, localmente fuertes y persistentes en la alta montaña. Viento moderado o fuerte de componentes oeste y sur, más intenso en cotas altas y zonas expuestas, donde soplará muy fuerte durante las horas centrales.

Datos en la atmósfera libre:

Altitud de la isoterma de 0 ºC: 2500 m
Altitud de la isoterma de -10 ºC: 4200 m

Viento a 1500 m: S de 50 km/h a 70 km/h
Viento a 3000 m: SW de 70 km/h a 90 km/h

Evolución para el viernes día 6

Los problemas de nieve húmeda y deslizamientos basales tienden a desaparecer.

Escala europea de peligro de aludes

Débil | Limitado | Notable | Fuerte | Muy Fuerte

Problemas de aludes

Nieve reciente | Placas de viento | Capas débiles persistentes | Nieve húmeda | Deslizamientos basales | Sin problema evidente

Nota1: Se recuerda que, siempre que haya nieve, la ausencia total de peligro no existe. Hay que tener presente que en circunstancias desfavorables, con aludes de tamaño 1 (alud pequeño o colada) y tamaño 2 (alud mediano), se pueden sufrir severos daños personales.

Nota2: Los BPA se elaboran en base a información meteorológica así como al estado del manto nivoso a través de sondeos puntuales. Se advierte a los usuarios de la variabilidad de esta información al extrapolarla a zonas extensas de montaña. Por ello, AEMET no se hace responsable de su uso para la toma de decisiones que conciernen a la seguridad personal, ni de los riesgos físicos o materiales de ellas derivadas.

AEMET. Se autoriza la reproducción de su contenido citando la fuente.