GOBIERNO DE ESPAÑA
VICEPRESIDENCIA TERCERA DEL GOBIERNO
MINISTERIO PARA LA TRANSICIÓN ECOLÓGICA Y EL RETO DEMOGRÁFICO

Boletín de información nivológica y de peligro de aludes

Pirineo Navarro y Aragonés

aemet Agencia Estatal de Meteorología

miércoles, 4 de febrero de 2026

Pronóstico hasta las 24 horas del jueves, día 5 de febrero

(Válido fuera de pistas de esquí balizadas y abiertas)

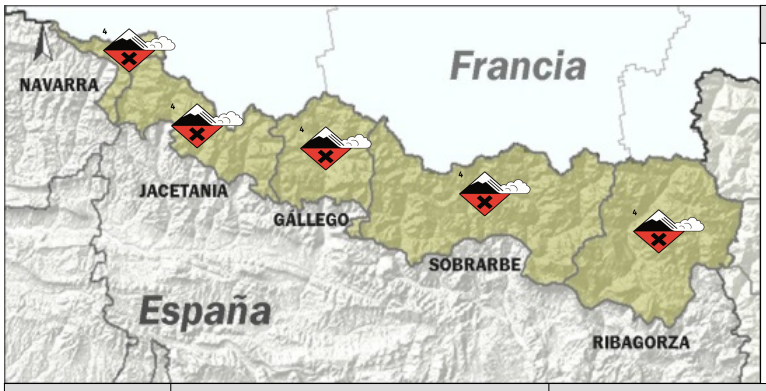

Problemas de aludes

Placas de viento

Nieve húmeda

Macizo	Peligro	Problemas de aludes, cota, orientación, tamaño	Innivación observada (m)
Navarra	4 4 / 3 2200 Fuerte	**Placas de viento** 2000 N O E S 3 **Nieve húmeda** 2000 N O E S 2	2026-02-04 N S Cotas bajas
Jacetania	4 4 / 3 2200 Fuerte	**Placas de viento** 2000 N O E S 3 **Nieve húmeda** 2000 N O E S 2	2026-02-04 N S Cotas bajas
Gállego	4 4 / 3 2200 Fuerte	**Placas de viento** 2000 N O E S 3 **Nieve húmeda** 2000 N O E S 2	2026-02-04 N S Cotas bajas

AEMET. Se autoriza la reproducción de su contenido citando la fuente.

Sobrarbe	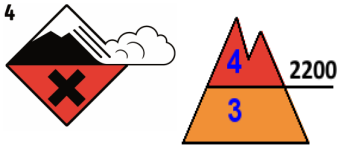 **Fuerte**	**Placas de viento** 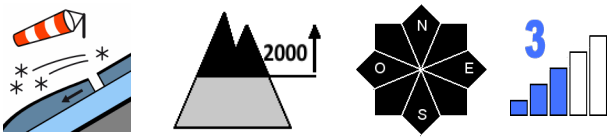 **Nieve húmeda** 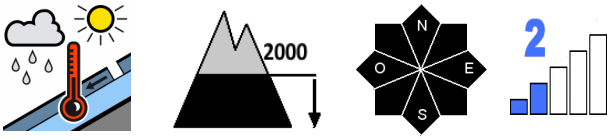	2026-02-04 Cotas bajas
Ribagorza	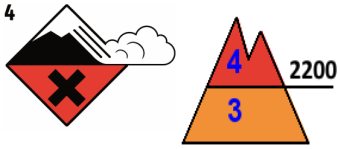 **Fuerte**	**Placas de viento** 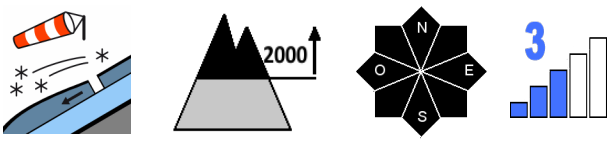 **Nieve húmeda** 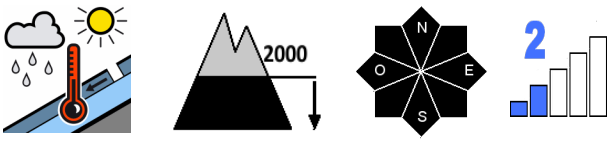	2026-02-04 Cotas bajas

Estado del manto y observaciones recientes

El paso de sucesivas borrascas está dejando precipitaciones en la cordillera, alternándose registros significativos con cantidades más discretas. La cota de nieve también ha fluctuado, si bien, por encima de unos 1800-2000 metros las precipitaciones han sido mayoritariamente sólidas. En las 24 horas anteriores a las 08 UTC de hoy ha nevado a partir de unos 1000-1100 metros, con acumulaciones de 5-10 l/m2, lo que ha supuesto unos 5-10 cm de nieve nueva, aunque en algunos enclaves, debido al viento, se han producido reducciones de unos 10 cm. Estas cantidades se incrementarán durante el día de hoy, ya que de nuevo se esperan unos 5-15 cm por encima de unos 1400-1500 metros, localmente más.

El manto es continuo desde cotas bajas, con espesores que alcanzan los 50-70 cm a 1300-1500 metros, y rondan los 140-180 cm a unos 1800 metros. A 2200-2400 metros, aunque presentan mayor variabilidad debido a la acción del viento, se superan fácilmente los 200 cm, aún más en ventisqueros y zonas de acumulación. Estos valores están muy por encima de lo que cabría esperar para las fechas en que nos encontramos.

En cotas altas la nieve se mantiene seca y muy venteada. Hay numerosas placas de viento en muchas orientaciones, que pueden colapsar ante esfuerzos débiles y propagar la fractura con facilidad. Además, en las umbrías, también encontramos estratos débiles persistentes, que siguen mostrando reactividad. En cotas inferiores la nieve se encuentra más humedecida, debido a las lluvias del lunes, aunque con el descenso de la cota de nieve, la superficie vuelve a presentarse seca.

En las últimas horas se han reportado dos aludes medianos de nieve reciente seca y salida puntual, a 2000-2250 metros y orientación nordeste en el Sobrarbe. Así como algunos disparos positivos en el Gállego, que han desencadenado placas friables a 2000-2250 metros en vertiente norte.

AEMET. Se autoriza la reproducción de su contenido citando la fuente.

Evolución del manto y peligro de aludes para el jueves, día 5

Problema de nieve reciente, placas de viento y capas débiles persistentes en cotas altas. Problema de nieve húmeda y deslizamientos basales en cotas bajas.

Mañana, jueves, van a continuar las precipitaciones, ascendiendo la cota de nieve hasta unos 1800-2000 metros en las horas centrales. De tal manera que por encima de esas altitudes se sumarán otros 15-30 cm a los caídos hoy, localmente más. En cotas inferiores las cantidades serán menores, ya que lloverá durante parte del periodo. Así, serán frecuentes las purgas de nieve reciente en las laderas suficientemente inclinadas de cotas altas, de tamaño pequeño (riesgo de caída) o mediano (capaz de enterrar a una persona), sin descartar que alguno pueda superar estas dimensiones. En cotas medias y bajas el manto se humidificará con las lluvias, por lo que se esperan aludes de nieve húmeda del mismo tamaño que los anteriores, incluso podría producirse algún deslizamiento basal en zonas herbosas o de piedra lisa, en cuyo caso podría movilizar más cantidad de nieve y llegar a ser grande.

El mayor peligro se sitúa en cotas altas. Seguirán soplando vientos fuertes de componentes oeste y sur, que nuevamente formarán placas en muchas orientaciones, aunque con preferencia en vertientes este y norte, que en ocasiones pueden localizarse alejadas de crestas y collados, así como quedar ocultas tras nevadas posteriores. Estas estructuras se sumarán a las generadas en episodios previos, que abarcan todas las orientaciones y que aún se mantienen inestables, pudiendo colapsar, tanto unas como otras, ante una sobrecarga débil (paso de un solo esquiador). Además, en las umbrías, podemos encontrar capas débiles persistentes en el interior del manto, que siguen dando muestras de reactividad, especialmente en zonas de manto delgado. Ambos tipos de problemas podrán dar lugar a aludes de tamaño 2 o 3 (grande, capaz de destruir un vehículo), aunque no se descarta que localmente alcancen el tamaño 4 (muy grande, capaz de destruir un camión o vagón de tren). Por último, cabe recordar la proliferación de cornisas y la posibilidad de desencadenamiento de aludes bajo estas en caso de ruptura.

Predicción meteorológica para el jueves, día 5

Pirineo navarro:

Nuboso de madrugada, aumentando pronto a muy nuboso o cubierto, aunque disminuyendo algo la nubosidad por la tarde. Visibilidad localmente reducida. Se esperan precipitaciones débiles o localmente moderadas, sin descartar que puedan ser persistentes en algunas zonas. Cota de nieve en torno a 1500-1600 metros al inicio y final del día, ascendiendo transitoriamente a 2000 metros en las horas centrales. No se descarta alguna tormenta ocasional. Temperaturas mínimas en ligero ascenso o sin cambios. Máximas en ascenso. Heladas débiles. Viento de componentes oeste y sur, generalmente fuerte o muy fuerte, más intenso en cotas altas y zonas expuestas durante las horas centrales.

Pirineo aragonés:

Predominio de cielos muy nubosos o cubiertos, aunque ocasionalmente podría abrirse algún claro de madrugada. Visibilidad localmente reducida. Se esperan precipitaciones débiles o moderadas, que localmente podrán ser persistentes o fuertes. Cota de nieve en torno a 1500-1600 metros al inicio y final del día, ascendiendo transitoriamente a 1800-2000 metros en las horas centrales. No se descarta alguna tormenta ocasional. Temperaturas en ligero

AEMET. Se autoriza la reproducción de su contenido citando la fuente.

ascenso, localmente sin cambios en los macizos orientales. Heladas débiles o moderadas, localmente fuertes y persistentes en la alta montaña. Viento moderado o fuerte de componentes oeste y sur, más intenso en cotas altas y zonas expuestas, donde soplará muy fuerte durante las horas centrales.

Datos en la atmósfera libre:

Altitud de la isoterma de 0 ºC: 2400 m
Altitud de la isoterma de -10 ºC: 4000 m

Viento a 1500 m: S de 50 km/h a 80 km/h
Viento a 3000 m: SW de 80 km/h a 100 km/h

Evolución para el viernes día 6

Los problemas de nieve húmeda y deslizamientos basales tienden a desaparecer.

(Información elaborada a partir de los datos recibidos de los refugios de Linza, Lizara, Panticosa, Bachimaña, Góriz, Pineta, Estós, Angel Orús, La Renclusa, Cap de Llauset y Belagua, de las estaciones de esquí de Candanchú y Formigal, de la estación de esquí de fondo de Llanos del Hospital y de Ordesa Pradera)

Escala europea de peligro de aludes

Débil | Limitado | Notable | Fuerte | Muy Fuerte

Problemas de aludes

Nieve reciente | Placas de viento | Capas débiles persistentes | Nieve húmeda | Deslizamientos basales | Sin problema evidente

Nota1: Se recuerda que, siempre que haya nieve, la ausencia total de peligro no existe. Hay que tener presente que en circunstancias desfavorables, con aludes de tamaño 1 (alud pequeño o colada) y tamaño 2 (alud mediano), se pueden sufrir severos daños personales.

Nota2: Los BPA se elaboran en base a información meteorológica así como al estado del manto nivoso a través de sondeos puntuales. Se advierte a los usuarios de la variabilidad de esta información al extrapolarla a zonas extensas de montaña. Por ello, AEMET no se hace responsable de su uso para la toma de decisiones que conciernen a la seguridad personal, ni de los riesgos físicos o materiales de ellas derivadas.

AEMET. Se autoriza la reproducción de su contenido citando la fuente.