Donnerstag 05.02.2026

Veröffentlicht am 04.02.2026 um 17:00

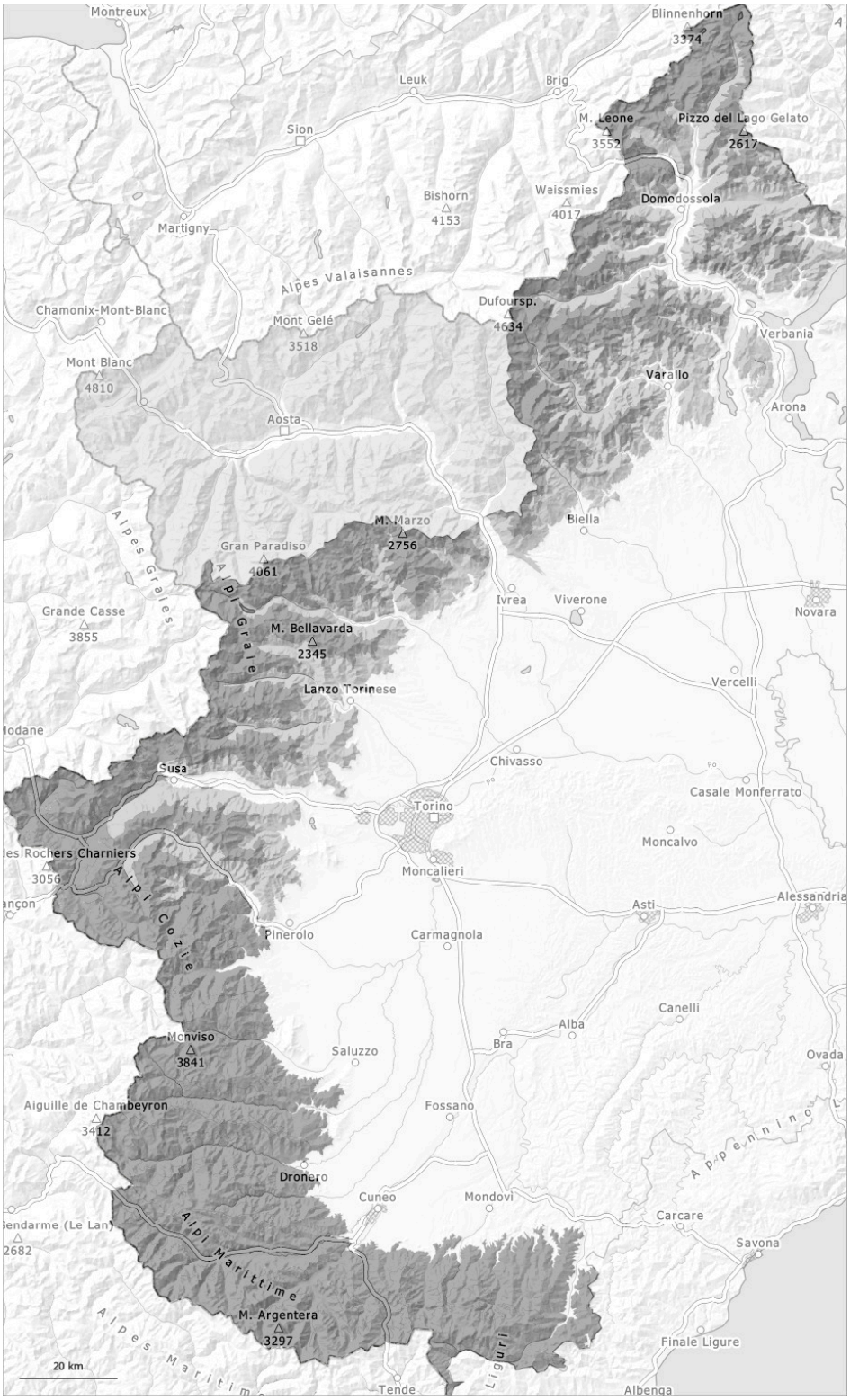

1	2	3	4	5
gering	mäßig	erheblich	groß	sehr groß

Gefahrenstufe 3 - Erheblich

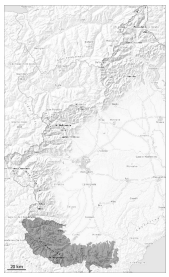

Tendenz: Lawinengefahr bleibt gleich
am Freitag, den 06.02.2026

Triebschnee

Waldgrenze

Neuschnee

Mit Neuschnee und Erwärmung weiterhin heikle Lawinensituation. Neu- und Triebschnee sind die Hauptgefahr.

Mit Neuschnee und starkem Südwestwind entstanden störanfällige Triebschneeansammlungen. Sie können leicht ausgelöst werden und vereinzelt sehr groß werden. Dies vor allem an steilen Hängen oberhalb der Waldgrenze sowie in Rinnen, Mulden und hinter Geländekanten. Die Gefahrenstellen sind teils überschneit und schwer zu erkennen.

Lawinen können oft in den verschiedenen Triebschneeschichten ausgelöst werden. Mit der tageszeitlichen Erwärmung und der Sonneneinstrahlung sind bereits viele mittlere und mehrfach große spontane trockene Lawinen möglich.

Wummgeräusche und Risse beim Betreten der Schneedecke sowie spontane Lawinenabgänge sind deutliche Zeichen eines schwachen Schneedeckenaufbaus. Touren erfordern Erfahrung in der Beurteilung der Lawinengefahr und eine vorsichtige Routenwahl.

Schneedecke

Gefahrenmuster gm.6: lockerer schnee und wind

Oberhalb von rund 1000 m liegt noch viel Schnee. Seit Dienstag fielen oberhalb von rund 1500 m verbreitet 30 bis 50 cm Schnee, lokal auch mehr. Mit starkem Westwind entstanden frische Triebschneeansammlungen.
Neu- und Triebschnee liegen verbreitet auf einer schwachen Altschneedecke.

Tendenz

Bis am Vormittag fällt verbreitet Schnee oberhalb von rund 700 m. Leichter Anstieg der Lawinengefahr mit Neuschnee und Wind.

Gefahrenstufe 3 - Erheblich

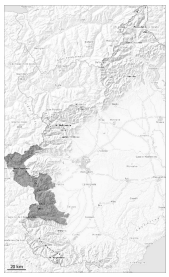

Tendenz: Lawinengefahr bleibt gleich
am Freitag, den 06.02.2026

Triebschnee

Waldgrenze

Neuschnee

Erhebliche Lawinengefahr. Neu- und Triebschnee bilden die Hauptgefahr.

Mit Neuschnee und mäßigem Wind entstanden teils große Triebschneeansammlungen. Triebschneeansammlungen können schon von einzelnen Wintersportlern ausgelöst werden. Dies vor allem an steilen Hängen sowie in Rinnen, Mulden und hinter Geländekanten auch in mittleren Lagen. Mit der tageszeitlichen Erwärmung und der Sonneneinstrahlung sind einige kleine und mittlere spontane trockene Lawinen möglich.
Die Gefahrenstellen sind teils überschneit schwer zu erkennen. Wummgeräusche und Risse beim Betreten der Schneedecke sowie spontane Lawinenabgänge sind deutliche Zeichen eines schwachen Schneedeckenaufbaus.
Lawinen können v.a. an steilen Schattenhängen in tieferen Schichten ausgelöst werden.
Eine vorsichtige Routenwahl und Entlastungsabstände werden empfohlen.

Schneedecke

Gefahrenmuster gm.6: lockerer schnee und wind | gm.1: bodennahe schwachschicht

Seit Dienstag fielen verbreitet 20 bis 25 cm Schnee, lokal auch mehr. Mit Neuschnee und mäßigem bis starkem Wind aus südlichen Richtungen entstanden vor allem oberhalb der Waldgrenze heikle Triebschneeansammlungen. Neu- und Triebschnee liegen vor allem an windgeschützten Schattenhängen auf weichen Schichten.

Mittlere und hohe Lagen: Im unteren Teil der Schneedecke sind vor allem an sehr steilen Schattenhängen vereinzelt störanfällige Schwachschichten vorhanden.

Tendenz

Bis am Vormittag fällt gebietsweise Schnee oberhalb von rund 1000 m. Leichter Anstieg der Lawinengefahr mit Neuschnee und Wind.

Gefahrenstufe 3 - Erheblich

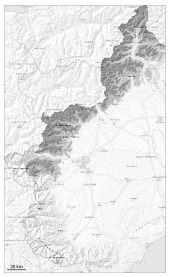

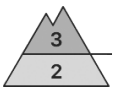

Waldgrenze

Tendenz: Lawinengefahr bleibt gleich
am Freitag, den 06.02.2026

Triebschnee

Waldgrenze

Neuschnee

In mittleren und hohen Lagen erhebliche Lawinengefahr.

Mit Neuschnee und teils starkem Wind aus westlichen Richtungen entstanden störanfällige Triebschneeansammlungen. Dies vor allem an steilen Hängen sowie in Rinnen, Mulden und hinter Geländekanten auch in mittleren Lagen. Die frischen Triebschneeansammlungen können mit geringer Belastung ausgelöst werden. Die Gefahrenstellen sind teils überschneit und kaum zu erkennen.

Mit der tageszeitlichen Erwärmung und der Sonneneinstrahlung sind einige kleine und mittlere spontane trockene Lawinen möglich.

Lawinen können v.a. an steilen Schattenhängen in tieferen Schichten ausgelöst werden. Mit Neuschnee und Wind sind mehrere mittlere und vereinzelt große spontane trockene Lawinen möglich.

Entlastungsabstände und Einzelabfahrten werden empfohlen.

Schneedecke

Gefahrenmuster gm.6: lockerer schnee und wind | gm.1: bodennahe schwachschicht

Seit Dienstag fielen oberhalb von rund 1500 m bis zu 15 cm Schnee. Mit Neuschnee und mäßigem Wind entstanden am Dienstag weitere Triebschneeansammlungen. Neu- und Triebschnee liegen vor allem an windgeschützten Schattenhängen auf weichen Schichten.

Mittlere und hohe Lagen: Im unteren Teil der Schneedecke sind vor allem an sehr steilen Schattenhängen vereinzelt störanfällige Schwachschichten vorhanden.

Tendenz

Bis am Vormittag fällt gebietsweise Schnee oberhalb von rund 1000 m. Leichter Anstieg der Lawinengefahr mit Neuschnee und Wind.